BUTLLETÍ DEL PERILL D'ALLAUS DEL PRINCIPAT D'ANDORRA

Servei meteorològic nacional
Principat d'Andorra

Préparé le 27/04/2026 16:00
Prochaine mise à jour le 28/04/2026 à 16h

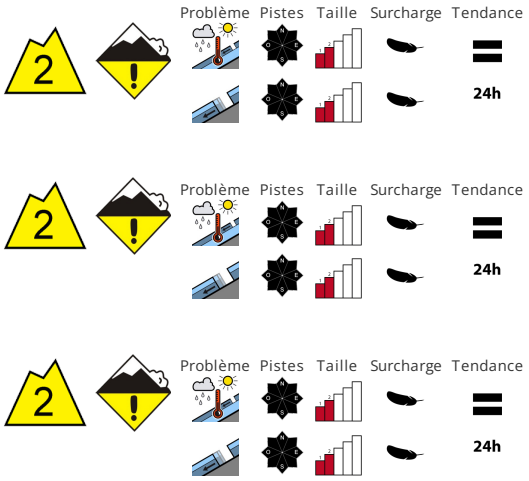

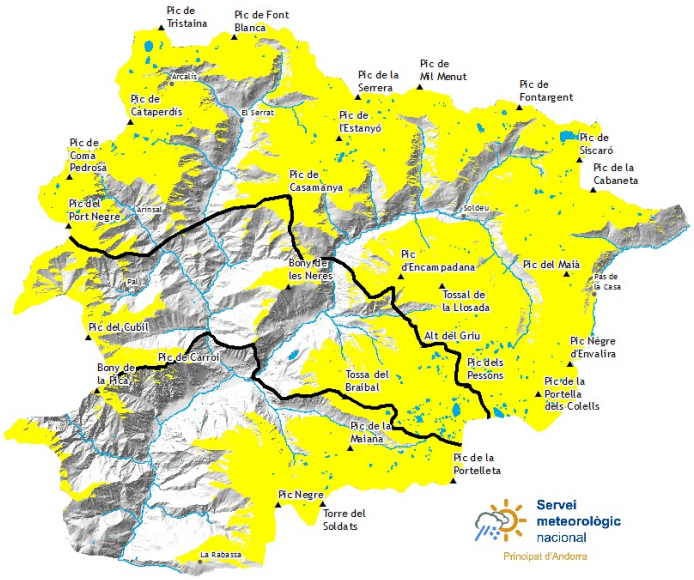

STABILITÉ DU MANTEAU NEIGEUX

Les conditions sont printanières. Des avalanches humides et mouillées de moyenne taille sont ils sont possibles avec l'humidification. En outre, des avalanches de glissement sont possibles à tout moment.. Prudence en présence de fissures de glissement.. À toutes les expositions le danger d'avalanches mouillées et de glissement augmente au sein du degré de danger en cours de journée au grade 1 (faible). Le danger d'avalanches subsiste. Des départs spontanés d'avalanches et les observations sur le terrain confirment la structure fragile du manteau neigeux.

QUALITÈ DE LA NEIGE

De manière généralisée le manteau neigeux est humide.. Le rayonnement nocturne est généralement fortement réduit.. Les conditions météorologiques entraînent le matin une humidification croissante du manteau neigeux. La pluie entraîne à partir de midi partiellement une perte de solidité au sein du manteau neigeux. Les zones présentant des fissures de glissement doivent être évitées.. Les randonnées devraient être commencées et terminées très tôt..

EPAISSEUR DE NEIGE HORS PISTE

Zone nord		Epaisseur de neige		
Nival manteau		1500m	2000m	2500m
N	1800 m	0 cm	100 cm	200 cm
S	2200 m	0 cm	0 cm	150 cm

Zone centre		Epaisseur de neige		
Nival manteau		1500m	2000m	2500m
N	1800 m	0 cm	90 cm	130 cm
S	2200 m	0 cm	0 cm	100 cm

Zone sud		Epaisseur de neige		
Nival manteau		1500m	2000m	2500m
N	1800 m	0 cm	90 cm	130 cm
S	2200 m	0 cm	0 cm	90 cm

Govern d'Andorra

EAWS
EUROPEAN AVALANCHE WARNING SERVICES

Aquest butlletí ha estat elaborat seguint les normes i recomanacions de l'**European Avalanche Warning Services**, del qual el **Servei meteorològic Nacional** n'és membre

BUTLLETÍ DEL PERILL D'ALLAUS DEL PRINCIPAT D'ANDORRA

Servei meteorològic nacional
Principat d'Andorra

Des informations détaillées par espace naturel protégé

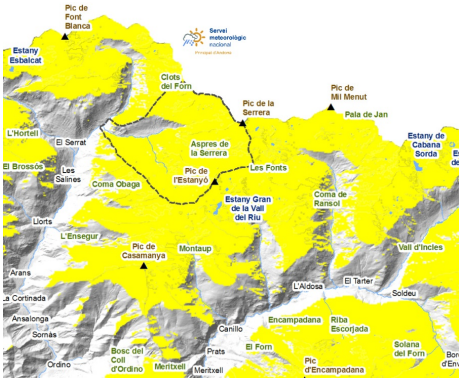

SORTENY

L'enneigement devient de plus en plus précaire. Le soleil du matin et les précipitations de l'après-midi humidifient le manteau, et le gel nocturne n'est ni bon ni efficace, ce qui rend la circulation sur la neige qui n'a pas été compactée tout au long de la saison est plus difficile. , , ,

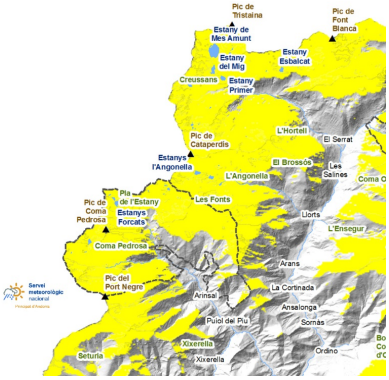

COMAPEDROSA

La neige est plus humide que la semaine dernière. Attention aux ponts de glace au-dessus des torrents, car ils seront fragilisés par l'augmentation du débit des rivières et l'affaiblissement du manteau neigeux. , , ,

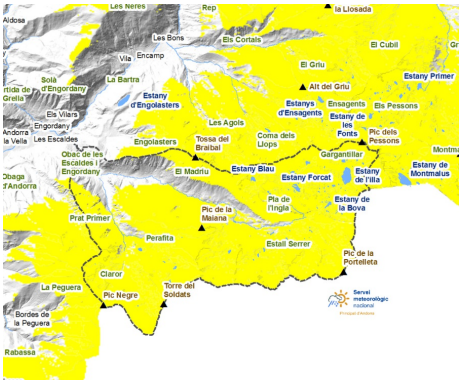

MADRIU-PERAFITA-CLAROR

L'humidité atteint les couches les plus profondes du manteau, favorisant un cycle d'avalanches naturelles de neige mouillée et de glissements basaux. Depuis l'Estall Serrer en aval, il ne reste plus de neige continue. , , ,

Govern d'Andorra

EAWS
EUROPEAN AVALANCHE WARNING SERVICES

Aquest butlletí ha estat elaborat seguint les normes i recomanacions de l'**European Avalanche Warning Services**, del qual el **Servei meteorològic Nacional** n'és membre

BUTLLETÍ DEL PERILL D'ALLAUS DEL PRINCIPAT D'ANDORRA

Servei meteorològic nacional
Principat d'Andorra

Couche de neige fraiche des derniers jours (De 24 h mesurée à 06:00 h UTC)

	23/04/2026	24/04/2026	25/04/2026	26/04/2026
FEDA (Central)	0 cm	0 cm	0 cm	0 cm
Engolasters - FEDA	0 cm	0 cm	0 cm	0 cm
Bony de les Neres	0 cm	0 cm	0 cm	0 cm
Sorteny	0 cm	0 cm	0 cm	0 cm
Les Fonts d'Arinsal	0 cm	0 cm	0 cm	0 cm
Aixàs	0 cm	0 cm	0 cm	0 cm
Perafita	0 cm	0 cm	0 cm	0 cm
Tossa Espiolets	0 cm	0 cm	0 cm	0 cm
Grau Roig - FEDA	0 cm	0 cm	0 cm	0 cm
Fontverd	0 cm	0 cm	0 cm	0 cm
Coll Ordino	0 cm	0 cm	0 cm	0 cm
Ransol - FEDA	0 cm	0 cm	0 cm	0 cm
Setúria	0 cm	0 cm	0 cm	0 cm
Caborreu	0 cm	0 cm	0 cm	0 cm
La Solana	0 cm	0 cm	0 cm	0 cm
Coll Pa	0 cm	0 cm	0 cm	0 cm
Envalira Antenes	0 cm	0 cm	0 cm	0 cm
Vall del Riu FEDA	0 cm	0 cm	0 cm	0 cm