Bulletin d'estimation du risque d'avalanche
(valable en dehors des pistes balisées et ouvertes)

MASSIF : Mercantour

Rédigé le lundi 27 avril 2026 à 15h

Estimation des risques pour le : MARDI 28 AVRIL

MANTEAU NEIGEUX PRINTANIER DE FIN DE SAISON BIEN STABLE

2

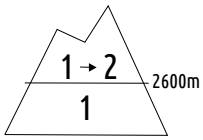

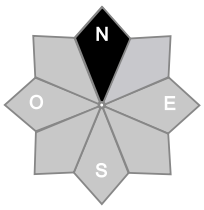

Au-dessus de 2600m indice de risque faible évoluant en limité, plus bas indice faible.

Départs spontanés : seulement en ubacs raides de haute altitude

Déclenchements provoqués : seulement en ubacs raides de haute altitude

Indices de risque : 5 très fort - 4 fort - 3 marqué - 2 limité - 1 faible -- En noir : les pentes les plus dangereuses

Stabilité du manteau neigeux

Situation avalancheuse typique : neige humide

Déclenchements provoqués : le manteau neigeux est très faible pour une fin avril, et très stable. Les instabilités ne sont possibles que dans de rares pentes raides plein nord de haute altitude, au-dessus de 2600/2700 m, où le manteau neigeux n'est pas totalement humidifié jusqu'au sol. Un skieur évoluant en fin de journée peut alors initier un départ de neige humide sur toute l'épaisseur du manteau neigeux, générant une avalanche de taille moyenne. Dans les autres orientations, le manteau neigeux est très stable et le fait de pousser de la neige de névé humide avec les skis ne constitue pas un danger d'avalanche.

Départs spontanés : très rares et seulement possibles en versants plein nord de haute altitude. Taille petite à moyenne.

Qualité de la neige

Enneigement très faible pour la période, après plus d'un mois sans précipitations notables et avec un iso 0 souvent à plus de 3000 m, l'enneigement est digne d'une mi mai. A la nivôse de Millefonts, on ne mesure plus que 70 cm de neige.

Enneigement skiable à partir de 2000/2100 m en ubacs, avec beaucoup de relief en surface en raison de l'intense fonte jusqu'à 2500/2600 m environ

État de la neige en surface : manteau neigeux sous forme de névé qui continue de fondre rapidement. Les pentes nord de haute altitude (> 2600 m) ne sont pas encore totalement transformées. Faible regel nocturne, puis reprise rapide de l'humidification et de la fonte en cours de journée dans toutes les expositions.

Aperçu météo pour le mardi 28 avril

	nuit	matin	après-midi	soir
	Rares averses dans une ambiance tiède			
Pluie-Neige		2 700 m		
Iso 0 °C	3 200 m	3 100 m	3 000 m	3 100 m
Vent 2000 m	5 km/h	15 km/h	25 km/h	5 km/h
Vent 3000 m	15 km/h	25 km/h	25 km/h	15 km/h

Épaisseur de neige hors-piste

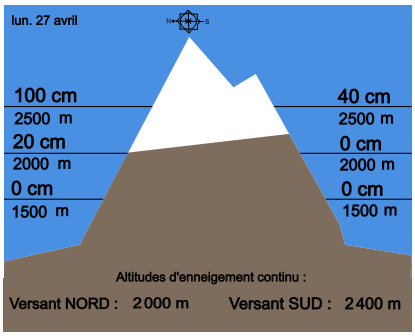

Précipitations à 1800 m

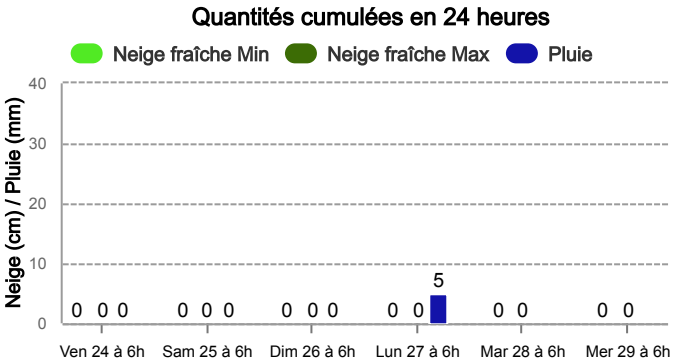

Tendance du mercredi 29 avril

2

Indice de risque limité

Pas d'évolution. Risque limité en neige humide ne concernant que les versants nord de haute montagne

Pour consulter la vigilance en cours, veuillez vous rendre sur le site https://vigilance.meteofrance.fr/fr

Météo-France - 73 avenue de Paris, 94165 Saint-Mandé cedex - Contact : contact@meteo.fr

Rédigé par Météo-France avec la contribution des observateurs du réseau nivo-météorologiques. Partenariat : ANMSM (Maires de Stations de Montagne), DSF (Domaines Skiables de France), ADSP (Directeurs de Pistes et de la Sécurité des Stations de Sports d'Hiver) et autres acteurs de la montagne.

Bulletin neige & avalanches par téléphone au

0 892 68 10 20 Service 0,35 € / min + prix appel

Bulletin d'estimation du risque d'avalanche

(valable en dehors des pistes balisées et ouvertes)

MASSIF : Mercantour

Rédigé le lundi 27 avril 2026 à 15h

Conditions nivo-météo des 7 derniers jours

	mar. 21/04				mer. 22/04				jeu. 23/04				ven. 24/04				sam. 25/04				dim. 26/04				lun. 27/04			
	03h	09h	15h	21h	03h	09h	15h	21h	03h	09h	15h	21h	03h	09h	15h	21h	03h	09h	15h	21h	03h	09h	15h	21h	03h	09h	15h	21h
Météo																												
Vent (km/h)	35	40	40	40	35	35	35	15	15	20	30	20	20	15	20	15	15	20	20	15	15	10	15	10	10	15	20	15
à 3000m																												
Vent (km/h)	15	15	20	10	15	25	20	20	20	20	30	15	10	10	15	10	10	10	20	10	10	10	15	10	10	15	20	10
à 2000m																												

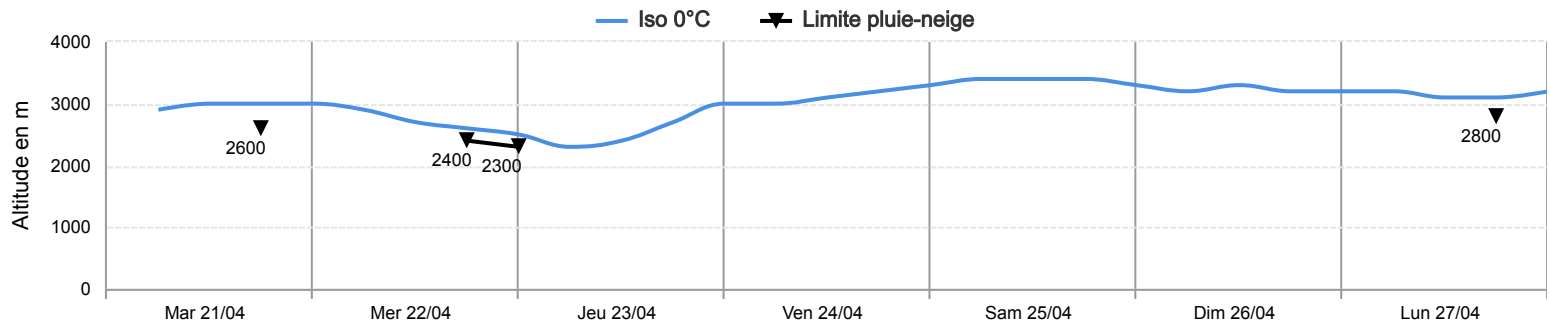

Neige fraîche à 06h

mar. 21/04	mer. 22/04	jeu. 23/04	ven. 24/04	sam. 25/04	dim. 26/04
0 cm	0 cm	0 cm	0 cm	0 cm	0 cm

Risque d'avalanche	mar. 21/04	mer. 22/04	jeu. 23/04	ven. 24/04	sam. 25/04	dim. 26/04	lun. 27/04
	2	2	2	2	2	2	2

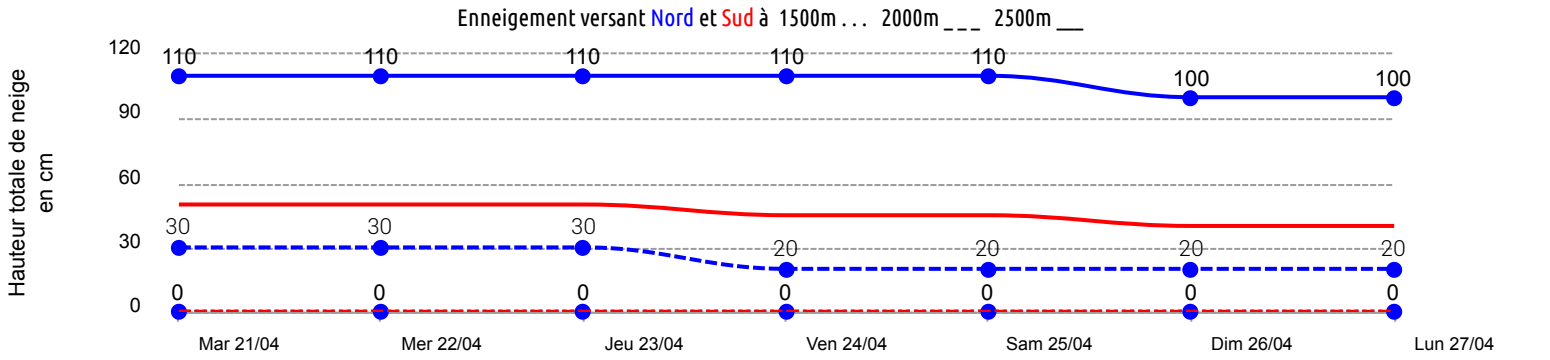

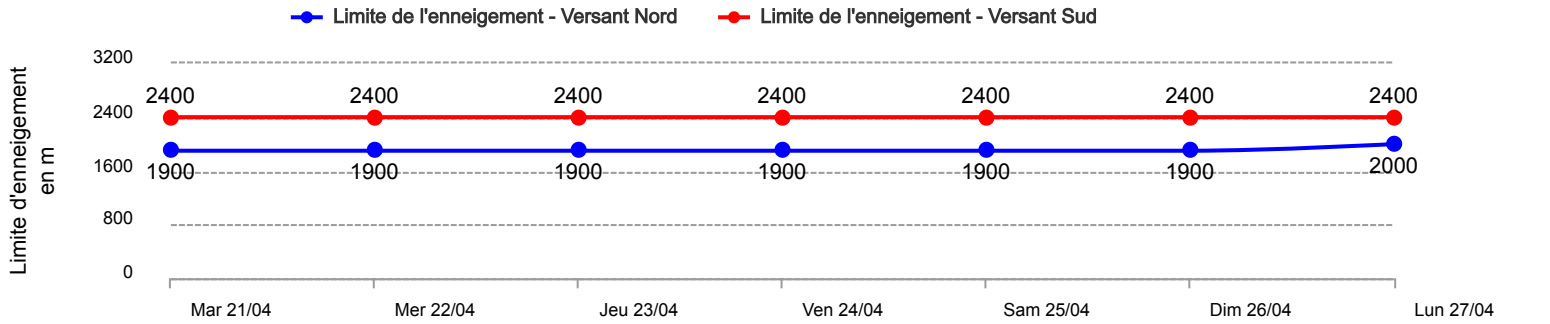

Pour consulter la vigilance en cours, veuillez vous rendre sur le site https://vigilance.meteofrance.fr/fr

Météo-France - 73 avenue de Paris, 94165 Saint-Mandé cedex - Contact : contact@meteo.fr

Bulletin neige & avalanches par téléphone au

0 892 68 10 20 Service 0,35 € / min + prix appel

Rédigé par Météo-France avec la contribution des observateurs du réseau nivo-météorologiques. Partenariat : ANMSM (Maires de Stations de Montagne), DSF (Domaines Skiables de France), ADSP (Directeurs de Pistes et de la Sécurité des Stations de Sports d'Hiver) et autres acteurs de la montagne.