RÉPUBLIQUE FRANÇAISE
Liberté Égalité Fraternité

METEO FRANCE
À VOS CÔTÉS, DANS UN CLIMAT QUI CHANGE

Bulletin d'estimation du risque d'avalanche
(valable en dehors des pistes balisées et ouvertes)

MASSIF : Aravis

Rédigé le lundi 27 avril 2026 à 16h

Estimation des risques pour le : MARDI 28 AVRIL

AVALANCHE DE NEIGE HUMIDE SOUS LES AVERSES

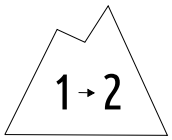

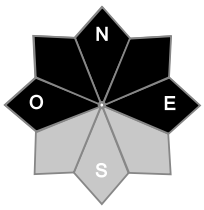

Indice de risque faible évoluant en limité.

Départs spontanés : avalanche de neige humide

Déclenchements provoqués : départs en neige humide sous les skis

Indices de risque : 5 très fort - 4 fort - 3 marqué - 2 limité - 1 faible -- En noir : les pentes les plus dangereuses

Stabilité du manteau neigeux

Situation avalancheuse typique : neige humide avalanches de fond

Départs spontanés :
* rares à quelques **avalanches de neige humide, plus nombreuses l'après-midi avec l'arrivée des précipitations.** Le regel, parfois plus hétérogène peut favoriser un départ dès la matinée. Taille 1 à 2 (petite à moyenne).
* quelques plaques de fond dans les zones herbeuses ou les dalles rocheuses, à toute heure du jour ou de la nuit. En dessous 2500 m. Taille 2 (moyenne). Au-dessus de 2400 m, dans les versants est, ouest et nord, de petits départs ponctuels peuvent déclencher, en cascade, une plaque de fond. Rare taille 3 (grande).

Déclenchements provoqués :
* avalanches de neige humide. Facile à déclencher tous versants. Départ ponctuel sous les skis. Taille 1 à 2. Causé par les averses et la couverture nuageuse.

Qualité de la neige

Enneigement :
Pour la saison, l'enneigement est déficitaire sous 2500 m
On peut chausser les skis au-dessus de 2000 m en sud et 1600 m en nord.

Qualité de la neige ce mardi matin :
* sous 2400 m, neige de névé avec un regel nocturne correct
* au-dessus de 2400 m, neige de printemps avec un regel nocturne correct

Aperçu météo pour le mardi 28 avril

	nuit	matin	après-midi	soir

Voilé puis couvert dès la matinée, passage d'averses parfois orageuses l'après-midi. Entre 5/15 mm de pluie localement.

Pluie-Neige			2 600 m	2 500 m
Iso 0 °C	3 100 m	2 700 m	2 800 m	2 800 m
Vent 2000 m	↗ 10 km/h	↑ 15 km/h	→ 15 km/h	↖ 15 km/h
Vent 2500 m	↗ 20 km/h	↗ 20 km/h	↑ 20 km/h	↑ 30 km/h

Épaisseur de neige hors-piste

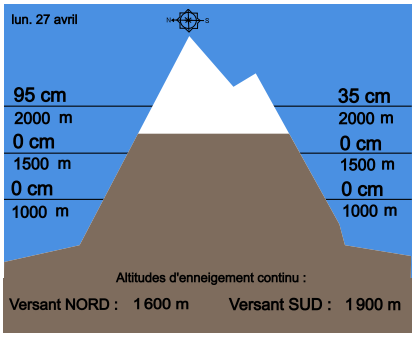

Précipitations à 1800 m

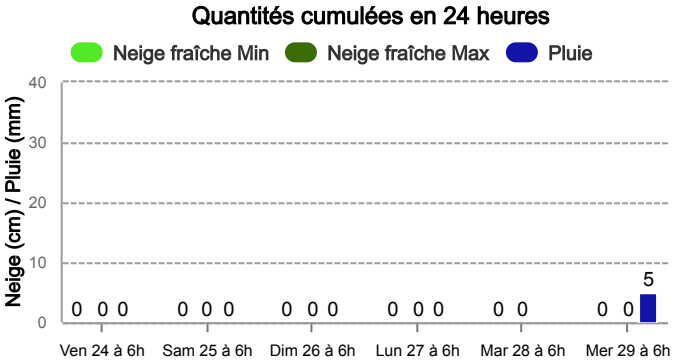

Tendance du mercredi 29 avril

Indice de risque limité

Maintien du risque. Mauvais regel la nuit suivante, avalanches en neige humide.

Pour consulter la vigilance en cours, veuillez vous rendre sur le site https://vigilance.meteofrance.fr/fr

Météo-France - 73 avenue de Paris, 94165 Saint-Mandé cedex - Contact : contact@meteo.fr

Rédigé par Météo-France avec la contribution des observateurs du réseau nivo-météorologiques. Partenariat : ANMSM (Maires de Stations de Montagne), DSF (Domaines Skiables de France), ADSP (Directeurs de Pistes et de la Sécurité des Stations de Sports d'Hiver) et autres acteurs de la montagne.

Bulletin neige & avalanches par téléphone au
0 892 68 10 20 Service 0,35 € / min + prix appel

RÉPUBLIQUE FRANÇAISE
Liberté Égalité Fraternité

METEO FRANCE
À VOS CÔTÉS, DANS UN CLIMAT QUI CHANGE

Bulletin d'estimation du risque d'avalanche

(valable en dehors des pistes balisées et ouvertes)

MASSIF : Aravis

Rédigé le lundi 27 avril 2026 à 16h

Conditions nivo-météo des 7 derniers jours

	mar. 21/04				mer. 22/04				jeu. 23/04				ven. 24/04				sam. 25/04				dim. 26/04				lun. 27/04			
	03h	09h	15h	21h	03h	09h	15h	21h	03h	09h	15h	21h	03h	09h	15h	21h	03h	09h	15h	21h	03h	09h	15h	21h	03h	09h	15h	21h
Météo																												
Vent (km/h)	20	20	20	20	20	20	10	10	10	20	15	20	10	5	10	5	10	15	20	10	5	10	10	10	10	10	20	20
à 2500m																												
Vent (km/h)	10	15	15	10	10	10	5	5	5	10	10	10	5	5	5	5	10	10	15	5	5	10	5	5	10	5	10	10
à 2000m																												

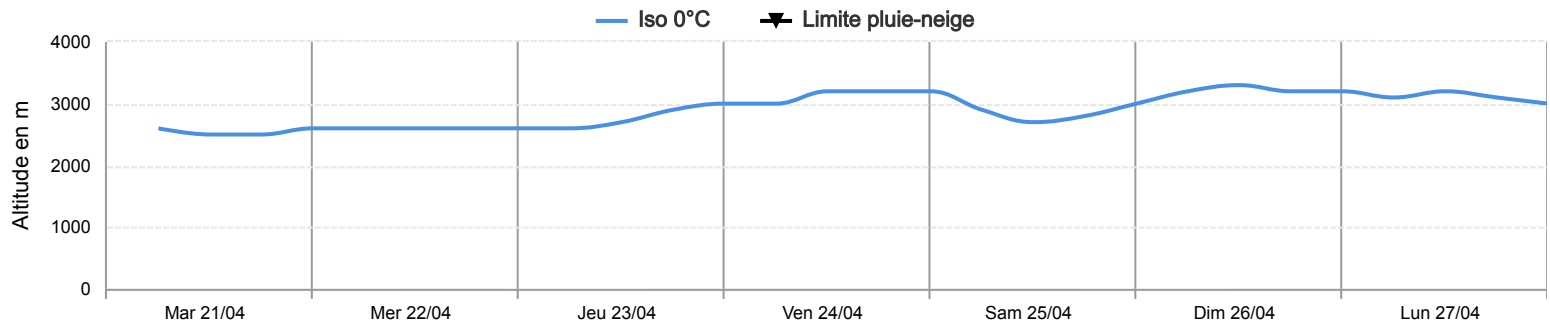

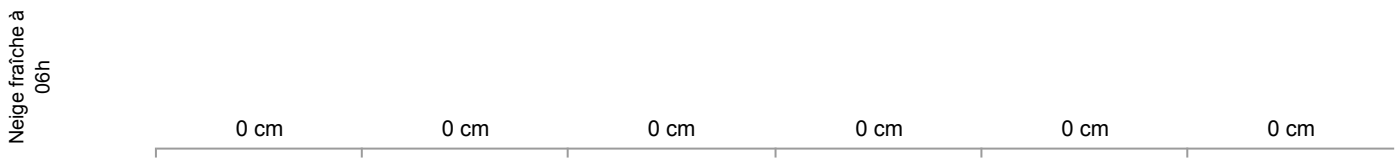

Risque d'avalanche	mar. 21/04	mer. 22/04	jeu. 23/04	ven. 24/04	sam. 25/04	dim. 26/04	lun. 27/04
	2	2	2	2	2	2	2

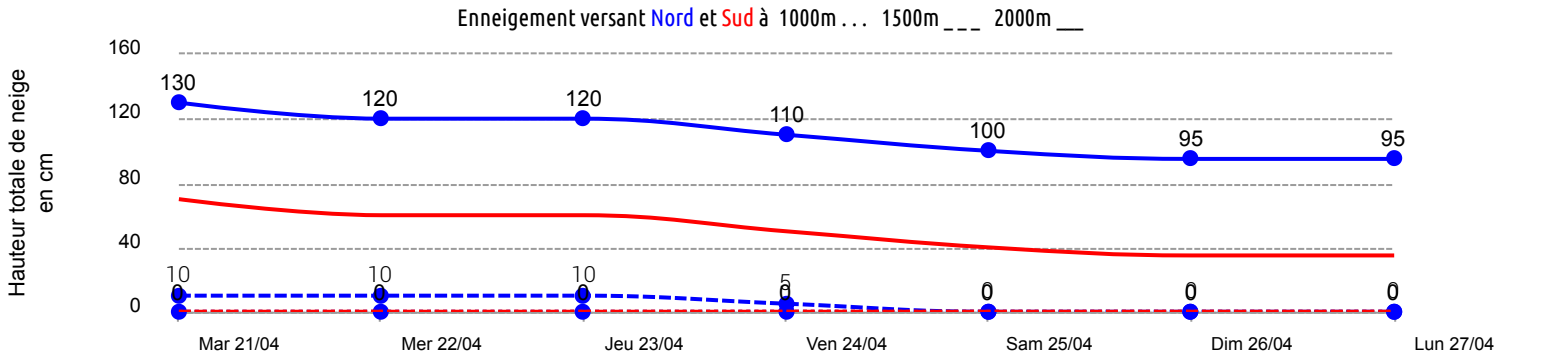

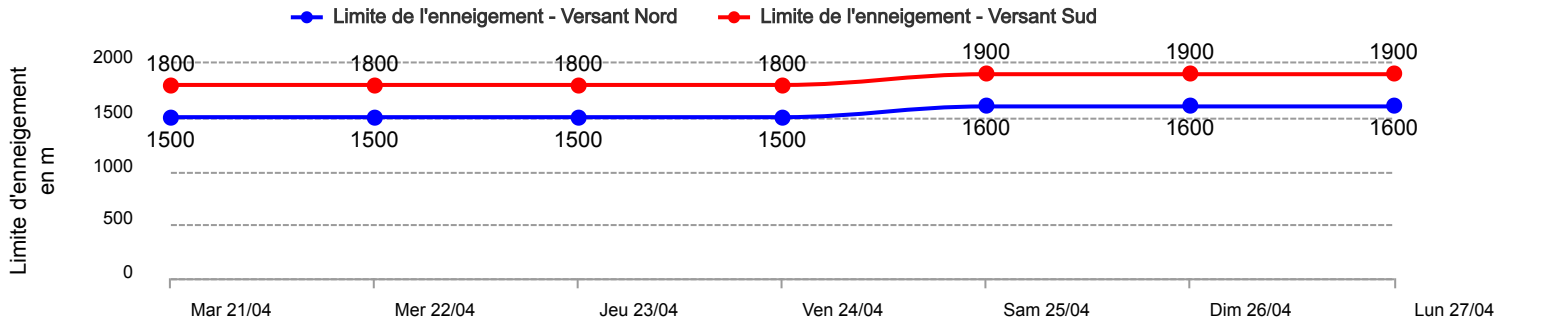

Pour consulter la vigilance en cours, veuillez vous rendre sur le site https://vigilance.meteofrance.fr/fr

Météo-France - 73 avenue de Paris, 94165 Saint-Mandé cedex - Contact : contact@meteo.fr

Bulletin neige & avalanches par téléphone au

0 892 68 10 20 Service 0,35 € / min + prix appel

Rédigé par Météo-France avec la contribution des observateurs du réseau nivo-météorologiques. Partenariat : ANMSM (Maires de Stations de Montagne), DSF (Domaines Skiables de France), ADSP (Directeurs de Pistes et de la Sécurité des Stations de Sports d'Hiver) et autres acteurs de la montagne.