RÉPUBLIQUE FRANÇAISE
Liberté Égalité Fraternité

METEO FRANCE
À VOS CÔTÉS, DANS UN CLIMAT QUI CHANGE

Bulletin d'estimation du risque d'avalanche

(valable en dehors des pistes balisées et ouvertes)

MASSIF : Aspe Ossau

Rédigé le lundi 27 avril 2026 à 16h

Estimation des risques pour le : MARDI 28 AVRIL

HUMIDIFICATION EN PROFONDEUR TOUJOURS EN COURS.

2

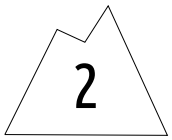

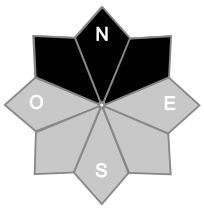

Indice de risque limité.

Départs spontanés : en neige humide, avalanches de fond moyennes à rarement grandes.

Déclenchements provoqués : en neige humide seulement.

Indices de risque : 5 très fort - 4 fort - 3 marqué - 2 limité - 1 faible -- En noir : les pentes les plus dangereuses

Stabilité du manteau neigeux

Situation avalancheuse typique : neige humide avalanches de fond

Départs spontanés :
Regel faible mais présent du manteau neigeux, peu d'activité à attendre aux premières heures de la journée, plutôt sous forme de départs ponctuels de neige humide en versants Est.
Activité augmentant en fréquence sous les éclaircies du matin puis les averses de l'après-midi, les coulées deviendront des avalanches de taille moyenne dans les pentes raides.
L'humidification pénétrant en profondeur dans le manteau neigeux au cours de la journée, quelques avalanches de fond de taille moyenne, voire grande (rarement), restent possibles dans l'après-midi et en fin de journée dans les pentes nord, partant du haut du massif. Départ à proximité des fissures déjà ouvertes et s'ouvrant au-dessus de 2500m.

Déclenchements provoqués : en neige humide seulement.
Déclenchement difficile de boulettes et de petites coulées de surface en pentes nord-est à est en début de matinée, puis déclenchement aisé de coulées et petites avalanches par un seul skieur ou randonneur en coupant une pente raide en neige très humide à détrempée, très localement une avalanche moyenne au plus fort de l'humidification dans les secteurs sud à ouest.

Autres :
- **corniches et ponts de neige** encore en place **fragiles et peu résistants**, pouvant **céder** dès le matin **spontanément** ou sous le **poids d'une seule personne, même s'ils semblent épais**
- neige regelée et durcie au-dessus de 2500/2600m, propice aux glissades en début de matinée,
- les **chemins de randonnée déjà déneigés** mais **situés sous les secteurs raides d'altitude encore chargés** peuvent être **atteints pas une avalanche de fond de taille moyenne à parfois grande** dans l'après-midi.

Qualité de la neige

Enneigement : plutôt bon pour la saison et débutant encore vers 1800m en nord et au-dessus de 2100m en sud. Les limites de cet enneigement remontent progressivement dans la douceur ambiante, sous les éclaircies matinales et les quelques averses de l'après-midi.
État de la neige :
Au petit matin, manteau neigeux tout juste ressaisi sous 2500m mais portant, plus au moins regelé en surface au dessus.
Dans la douceur ambiante, sous les éclaircies matinales puis les averses localement orageuses de l'après-midi, l'humidification en profondeur se poursuit, le manteau neigeux ramollit au fil des heures : neige devenant très humide à détrempée en versants nord au-dessus de 2400/2500m, souvent pourrie partout ailleurs.

Aperçu météo pour le mardi 28 avril

	nuit	matin	après-midi	soir
Développement de quelques averses orageuses l'après-midi, moins marquées que la veille				
Pluie-Neige				
Iso 0 °C	3 100 m	3 000 m	3 100 m	3 000 m
Vent 1500 m	10 km/h	10 km/h	20 km/h	15 km/h
Vent 3000 m	20 km/h	15 km/h	25 km/h	30 km/h

Pour consulter la vigilance en cours, veuillez vous rendre sur le site https://vigilance.meteofrance.fr/fr

Météo-France - 73 avenue de Paris, 94165 Saint-Mandé cedex - Contact : contact@meteo.fr

Rédigé par Météo-France avec la contribution des observateurs du réseau nivo-météorologiques. Partenariat : ANMSM (Maires de Stations de Montagne), DSF (Domaines Skiables de France), ADSP (Directeurs de Pistes et de la Sécurité des Stations de Sports d'Hiver) et autres acteurs de la montagne.

Bulletin neige & avalanches par téléphone au
0 892 68 10 20 Service 0,35 € / min + prix appel

Bulletin d'estimation du risque d'avalanche

(valable en dehors des pistes balisées et ouvertes)

MASSIF : Aspe Ossau

Rédigé le lundi 27 avril 2026 à 16h

Épaisseur de neige hors-piste

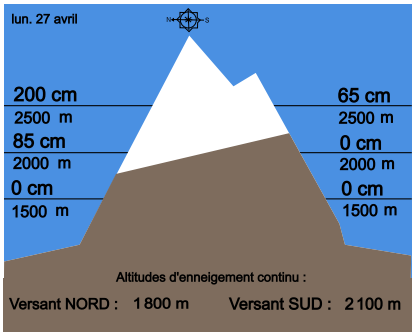

Précipitations à 1800 m

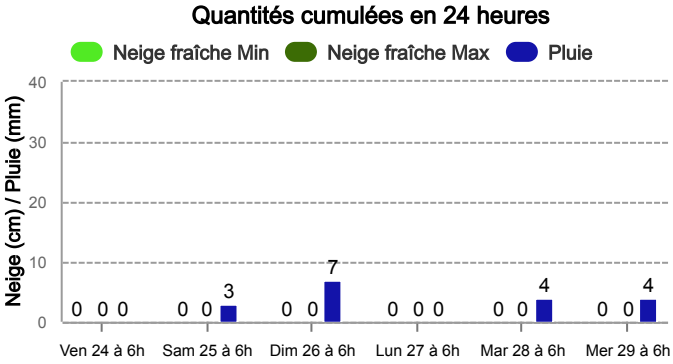

Tendance du mercredi 29 avril

Indice de risque limité

Activité plus matinale avec un regel médiocre ou absent

Pour consulter la vigilance en cours, veuillez vous rendre sur le site https://vigilance.meteofrance.fr/fr

Météo-France - 73 avenue de Paris, 94165 Saint-Mandé cedex - Contact : contact@meteo.fr

Rédigé par Météo-France avec la contribution des observateurs du réseau nivo-météorologiques. Partenariat : ANMSM (Maires de Stations de Montagne), DSF (Domaines Skiables de France), ADSP (Directeurs de Pistes et de la Sécurité des Stations de Sports d'Hiver) et autres acteurs de la montagne.

Bulletin neige & avalanches par téléphone au

0 892 68 10 20 Service 0,35 € / min + prix appel

RÉPUBLIQUE FRANÇAISE
Liberté Égalité Fraternité

METEO FRANCE
À VOS CÔTÉS, DANS UN CLIMAT QUI CHANGE

Bulletin d'estimation du risque d'avalanche

(valable en dehors des pistes balisées et ouvertes)

MASSIF : Aspe Ossau

Rédigé le lundi 27 avril 2026 à 16h

Conditions nivo-météo des 7 derniers jours

	mar. 21/04				mer. 22/04				jeu. 23/04				ven. 24/04				sam. 25/04				dim. 26/04				lun. 27/04			
	03h	09h	15h	21h	03h	09h	15h	21h	03h	09h	15h	21h	03h	09h	15h	21h	03h	09h	15h	21h	03h	09h	15h	21h	03h	09h	15h	21h
Météo																												
Vent (km/h)	20	35	40	55	40	30	20	15	30	30	35	35	40	35	20	15	20	25	15	25	25	20	20	20	20	20	20	25
à 3000m																												
Vent (km/h)	10	5	10	20	30	25	20	10	15	15	20	20	25	15	10	10	10	15	5	10	5	15	10	10	10	5	2	5
à 1500m																												

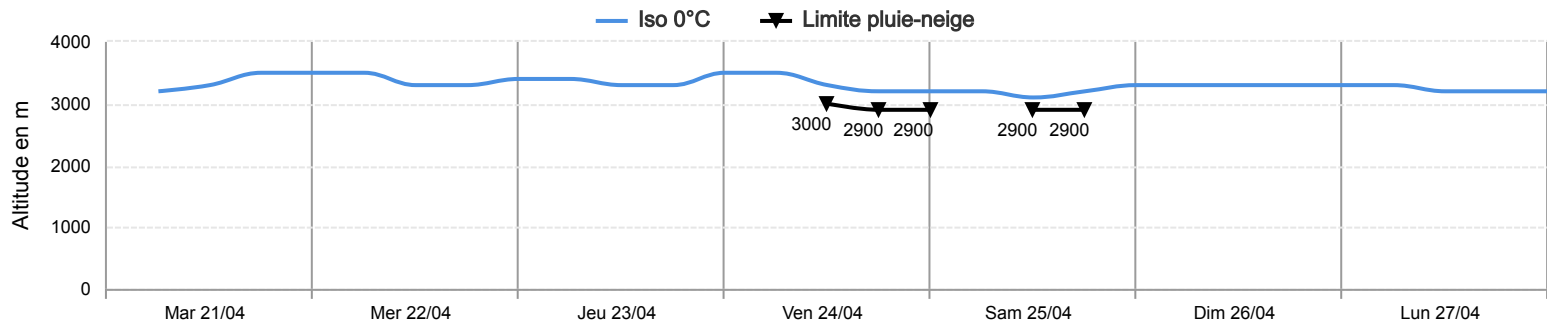

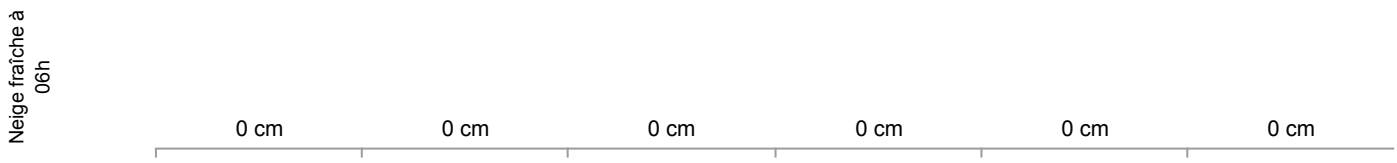

Risque d'avalanche	mar. 21/04	mer. 22/04	jeu. 23/04	ven. 24/04	sam. 25/04	dim. 26/04	lun. 27/04
	2	3	3	3	3	2	2

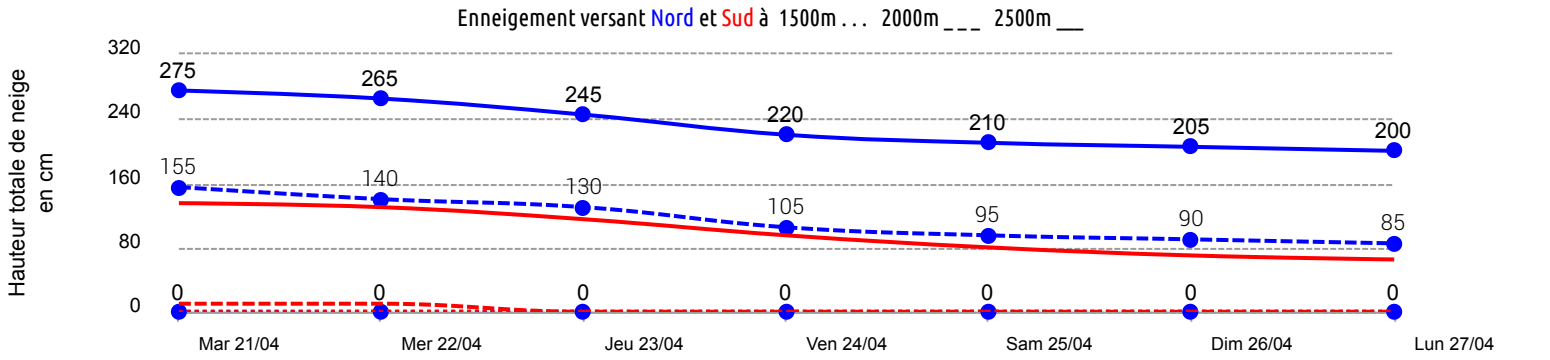

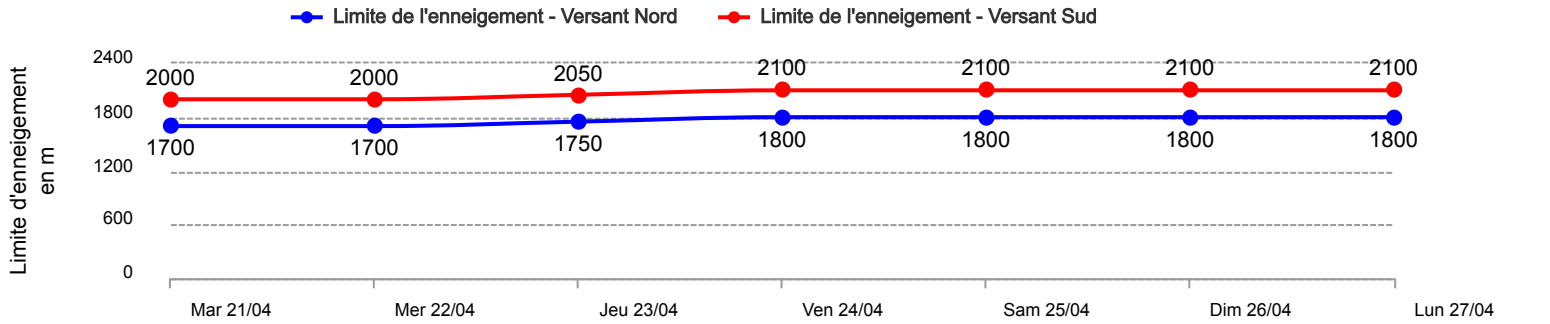

Pour consulter la vigilance en cours, veuillez vous rendre sur le site https://vigilance.meteofrance.fr/fr

Météo-France - 73 avenue de Paris, 94165 Saint-Mandé cedex - Contact : contact@meteo.fr

Rédigé par Météo-France avec la contribution des observateurs du réseau nivo-météorologiques. Partenariat : ANMSM (Maires de Stations de Montagne), DSF (Domaines Skiables de France), ADSP (Directeurs de Pistes et de la Sécurité des Stations de Sports d'Hiver) et autres acteurs de la montagne.

Bulletin neige & avalanches par téléphone au
0 892 68 10 20 Service 0,35 € / min + prix appel