Bulletin d'estimation du risque d'avalanche

(valable en dehors des pistes balisées et ouvertes)

MASSIF : Belledonne

Rédigé le lundi 27 avril 2026 à 16h

Estimation des risques pour le : MARDI 28 AVRIL

MANTEAU NEIGEUX PRINTANIER, RARE AVALANCHE DE "FONTE".

2

1 → 2

N O E S

Indice de risque faible évoluant en limité.

Départs spontanés : Rares avalanches humides ou départs au terrain, plutôt en faces "froides".

Déclenchements provoqués : Peu probables, ou sous les skis en neige très humide (pentes raides)...

Indices de risque : 5 très fort - 4 fort - 3 marqué - 2 limité - 1 faible -- En noir : les pentes les plus dangereuses

Stabilité du manteau neigeux

Situation avalancheuse typique : neige humide

Départs spontanés : Regel nocturne correct en altitude, parfois médiocre sous 2500m avec l'arrivée du voile nuageux. En journée sous les averses, de rares coulées seront possibles dans les pentes Est, Nord ou Ouest, surtout sous 2600 à 2700m (limite de la pluie). Exceptionnellement, plutôt en Nord, une grande avalanche de taille 3 ne peut être exclue si l'humidification atteint une couche fragile plus enfouie, avec départ linéaire et/ou au terrain possible. Plus haut, les chutes de neige freinent l'humidification. Très localement une petite purge est possible dans la neige récente, sous les rochers.

Déclenchements provoqués : Peu probables, hormis un risque limité de coulée ponctuelle sous les skis en terrain raide et bien humidifié. Au-dessus de 2600m, possibilité de faire partir des coulées ponctuelles dans les 7 à 15cm de neige récente bien humide.

Qualité de la neige

Qualification de l'enneigement : L'enneigement s'est bien réduit depuis début avril, il devient déficitaire en faces Sud et en moyenne montagne. Il reste correct dans les versants Nord d'altitude.

Limites skiables : Vers 1500/1700m en Nord à 1900/2200m suivant l'exposition au soleil, la raideur de la pente...

Qualité de la neige mardi : Regel correct en altitude, médiocre ou inexistant sous 2400 / 2500m. En matinée la couverture nuageuse retarde l'humidification. Dans l'après-midi les averses vont détremper le manteau neigeux sous 2600m, tandis qu'à plus haute altitude on peut attendre jusqu'à 7 à 15cm de neige humide.

Aperçu météo pour le mardi 28 avril

	nuit	matin	après-midi	soir
Ciel voilé à nuageux en matinée. L'après-midi les conditions se dégradent avec des averses parfois orageuses, donnant un peu de neige au-dessus de 2600m environ.				
Pluie-Neige			2 600 m	2 600 m
Iso 0 °C	3 100 m	2 800 m	2 900 m	2 900 m
Vent 2000 m	↗ 10 km/h	↗ 15 km/h	↗ 20 km/h	↖ 15 km/h
Vent 3000 m	↗ 15 km/h	↑ 15 km/h	↗ 30 km/h	↗ 30 km/h

Épaisseur de neige hors-piste

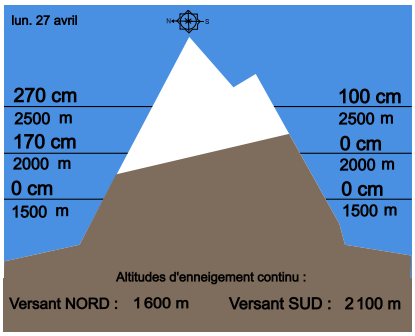

Précipitations à 1800 m

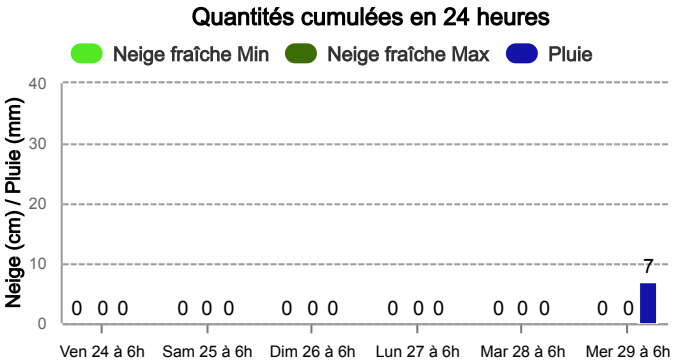

Tendance du mercredi 29 avril

2

Indice de risque limité

Mercredi, peu d'évolution du risque. Le regel nocturne est médiocre. Après de belles éclaircies en matinée, les nuages bourgeonnent rapidement et on attends de nouvelles averses parfois orageuses l'après-midi. L'humidification gagne encore en profondeur, avec toujours un faible risque de départ en plaque si l'humidification gagne des couches fragiles enfouies.

Pour consulter la vigilance en cours, veuillez vous rendre sur le site https://vigilance.meteofrance.fr/fr

Météo-France - 73 avenue de Paris, 94165 Saint-Mandé cedex - Contact : contact@meteo.fr

Rédigé par Météo-France avec la contribution des observateurs du réseau nivo-météorologiques. Partenariat : ANMSM (Maires de Stations de Montagne), DSF (Domaines Skiables de France), ADSP (Directeurs de Pistes et de la Sécurité des Stations de Sports d'Hiver) et autres acteurs de la montagne.

Bulletin neige & avalanches par téléphone au 0 892 68 10 20 Service 0,35 € / min + prix appel

RÉPUBLIQUE FRANÇAISE
Liberté Égalité Fraternité

METEO FRANCE
À VOS CÔTÉS, DANS UN CLIMAT QUI CHANGE

Bulletin d'estimation du risque d'avalanche

(valable en dehors des pistes balisées et ouvertes)

MASSIF : Belledonne

Rédigé le lundi 27 avril 2026 à 16h

Conditions nivo-météo des 7 derniers jours

	mar. 21/04				mer. 22/04				jeu. 23/04				ven. 24/04				sam. 25/04				dim. 26/04				lun. 27/04			
	03h	09h	15h	21h	03h	09h	15h	21h	03h	09h	15h	21h	03h	09h	15h	21h	03h	09h	15h	21h	03h	09h	15h	21h	03h	09h	15h	21h
Météo																												
Vent (km/h)	35	30	30	25	35	35	25	15	15	20	25	15	15	5	10	5	10	20	20	15	15	15	15	15	10	10	15	20
à 3000m																												
Vent (km/h)	10	10	20	10	10	15	20	10	10	15	15	10	10	5	15	10	10	15	15	10	10	10	10	10	5	5	10	10
à 2000m																												

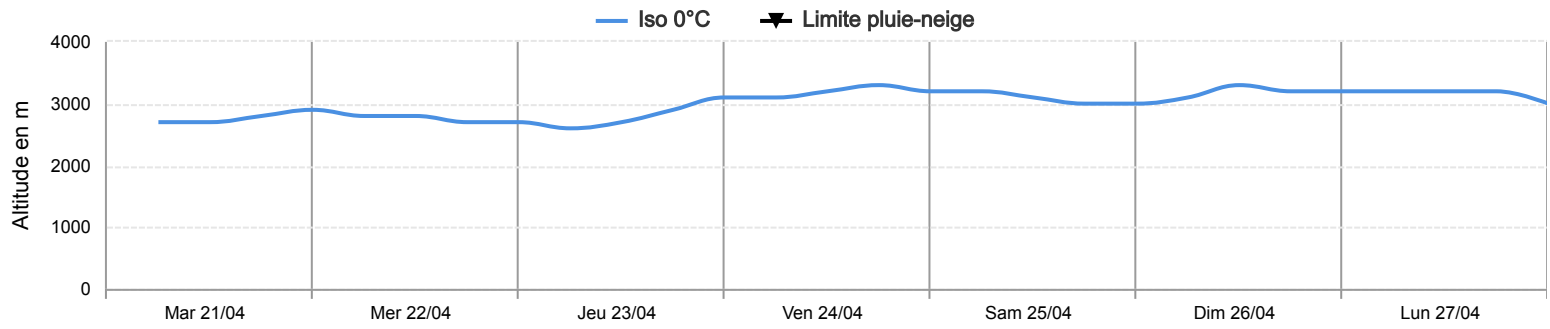

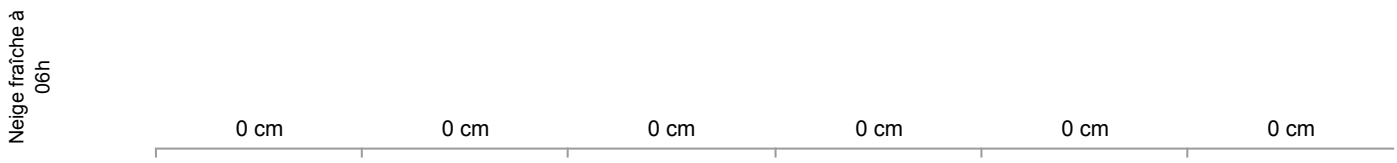

Risque d'avalanche	mar. 21/04	mer. 22/04	jeu. 23/04	ven. 24/04	sam. 25/04	dim. 26/04	lun. 27/04
	2	2	2	2	2	2	2

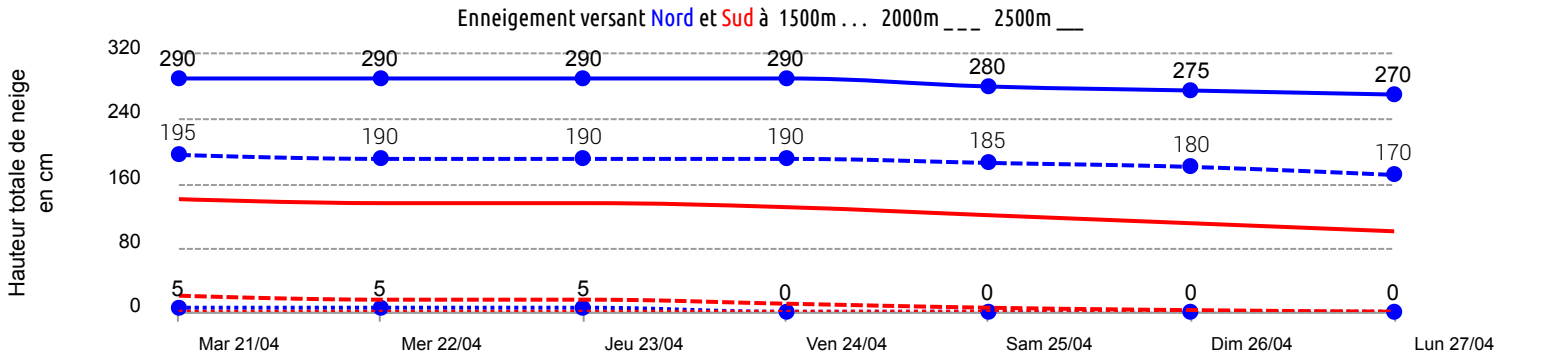

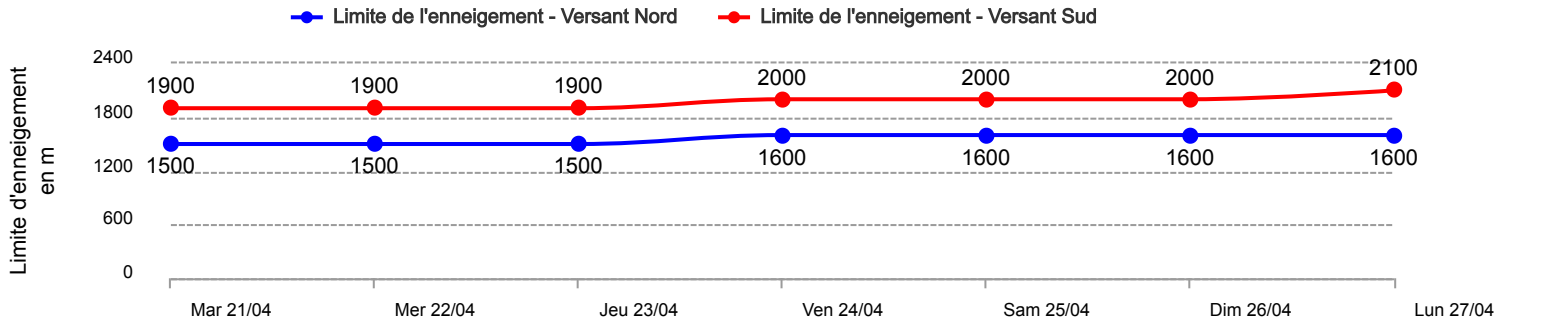

Pour consulter la vigilance en cours, veuillez vous rendre sur le site https://vigilance.meteofrance.fr/fr

Météo-France - 73 avenue de Paris, 94165 Saint-Mandé cedex - Contact : contact@meteo.fr

Rédigé par Météo-France avec la contribution des observateurs du réseau nivo-météorologiques. Partenariat : ANMSM (Maires de Stations de Montagne), DSF (Domaines Skiables de France), ADSP (Directeurs de Pistes et de la Sécurité des Stations de Sports d'Hiver) et autres acteurs de la montagne.

Bulletin neige & avalanches par téléphone au
0 892 68 10 20 Service 0,35 € / min + prix appel