Bulletin d'estimation du risque d'avalanche
(valable en dehors des pistes balisées et ouvertes)

MASSIF : Oisans

Rédigé le lundi 27 avril 2026 à 16h

Estimation des risques pour le : MARDI 28 AVRIL

MANTEAU NEIGEUX PRINTANIER, RARE AVALANCHE DE "FONTE", RETOUR DE LA NEIGE EN HAUTE-MONTAGNE

2

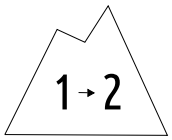

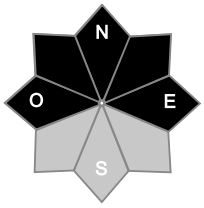

Indice de risque faible évoluant en limité.

Départs spontanés : Rares avalanches humides ou départs au terrain, plutôt en faces "froides". Une cassure large non exclue en Nord.

Déclenchements provoqués : Peu probables, ou sous les skis en neige très humide (pentes raides)...

Indices de risque : 5 très fort - 4 fort - 3 marqué - 2 limité - 1 faible -- En noir : les pentes les plus dangereuses

Stabilité du manteau neigeux

Situation avalancheuse typique : neige humide

Départs spontanés : Regel nocturne bon à très bon en altitude, correct sous 2500m. En matinée le manteau est stable, puis en journée l'humidification reprends difficilement sous le ciel nuageux, puis s'accélère sous 2600m avec l'arrivée de la pluie en journée. Dans les versants Ouest, Nord et Est, l'humidification gagne en profondeur et de rares avalanches humides peuvent se produire. Dans les versants Nord-Ouest à Nord-Est, une avalanche de grande taille serait exceptionnellement possible si l'humidification gagnerait des couches fragiles enfouies, dans quel cas un départ linéaire serait possible, voire un départ au terrain.
Au-dessus de 2600 à 2700m, la neige récente freine l'humidification. Les cumuls restent faibles, éventuellement une petite purge en neige récente humide sous les rochers.

Déclenchements provoqués : Peu probables, hormis un risque limité de coulée ponctuelle sous les skis en terrain raide et bien humidifié. Au-dessus de 2600m, possibilité de faire partir des coulées ponctuelles dans les 5 à 10cm de neige récente bien humide. En haute montagne, éventuellement des structures de plaques superficielles dans la neige fraîche.

Autres : Neige parfois durcie / croûtée par le regel.

Qualité de la neige

Qualification de l'enneigement : L'enneigement s'est bien réduit depuis début avril, il devient déficitaire en faces Sud et en bas de pentes. Il reste correct seulement dans les versants Nord d'altitude.

Limites skiables : Vers 1600/1800m en Nord à 2100/2400m suivant l'exposition au soleil, la raideur de la pente...

Qualité de la neige mardi : Neige bosselée, parfois croûtée / durcie par le regel (bon en altitude, correct sous 2500m). En journée, l'humidification est ralentie par la couverture nuageuse, pas ou très peu de dégel au-dessus de 3000m environ. L'après-midi, des averses apportent 5 à 10cm de neige humide au-dessus de 2600m, tandis que plus bas la pluie vient détremper le manteau. Neige froide au-dessus de 3200m environ.

Aperçu météo pour le mardi 28 avril

	nuit	matin	après-midi	soir

Ciel voilé au réveil, devenant franchement nuageux en cours de matinée. L'après-midi les conditions se dégradent, avec des averses parfois orageuses.

Pluie-Neige		2 400 m	2 600 m	
Iso 0 °C	3 100 m	3 000 m	3 000 m	2 900 m
Vent 2500 m	↗ 5 km/h	↑ 15 km/h	↑ 20 km/h	↖ 15 km/h
Vent 3500 m	↗ 15 km/h	↑ 20 km/h	↗ 25 km/h	↖ 20 km/h

Épaisseur de neige hors-piste

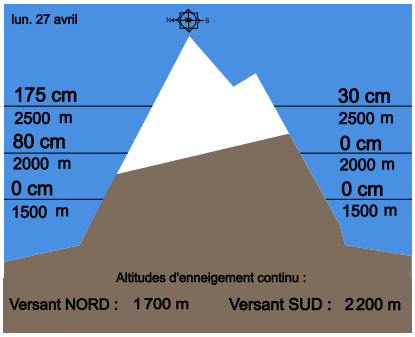

Précipitations à 1800 m

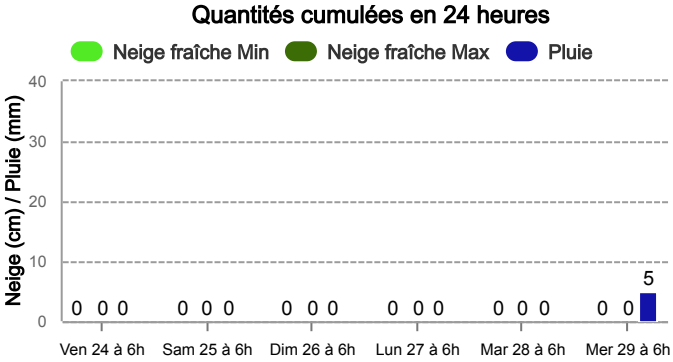

Tendance du mercredi 29 avril

2

Indice de risque limité

Mercredi, peu d'évolution du risque. Le regel nocturne est médiocre. Après de belles éclaircies en matinée, les nuages bourgeonnent rapidement et on attends de nouvelles averses parfois orageuses l'après-midi. L'humidification gagne encore en profondeur, avec toujours un faible risque de départ en plaque si l'humidification gagne des couches fragiles enfouies.

Pour consulter la vigilance en cours, veuillez vous rendre sur le site https://vigilance.meteofrance.fr/fr

Météo-France - 73 avenue de Paris, 94165 Saint-Mandé cedex - Contact : contact@meteo.fr

Rédigé par Météo-France avec la contribution des observateurs du réseau nivo-météorologiques. Partenariat : ANMSM (Maires de Stations de Montagne), DSF (Domaines Skiables de France), ADSP (Directeurs de Pistes et de la Sécurité des Stations de Sports d'Hiver) et autres acteurs de la montagne.

Bulletin neige & avalanches par téléphone au

0 892 68 10 20 Service 0,35 € / min + prix appel

RÉPUBLIQUE FRANÇAISE
Liberté Égalité Fraternité

METEO FRANCE
À VOS CÔTÉS, DANS UN CLIMAT QUI CHANGE

Bulletin d'estimation du risque d'avalanche
(valable en dehors des pistes balisées et ouvertes)

MASSIF : Oisans

Rédigé le lundi 27 avril 2026 à 16h

Conditions nivo-météo des 7 derniers jours

	mar. 21/04				mer. 22/04				jeu. 23/04				ven. 24/04				sam. 25/04				dim. 26/04				lun. 27/04			
	03h	09h	15h	21h	03h	09h	15h	21h	03h	09h	15h	21h	03h	09h	15h	21h	03h	09h	15h	21h	03h	09h	15h	21h	03h	09h	15h	21h
Météo																												
Vent (km/h)	45	45	40	40	30	30	30	20	15	20	15	10	10	5	10	10	10	15	15	15	15	10	10	10	5	5	15	10
à 3500m																												
Vent (km/h)	30	35	30	20	15	15	20	10	10	10	10	10	5	5	10	5	5	10	10	10	10	5	5	5	5	5	10	5
à 2500m																												

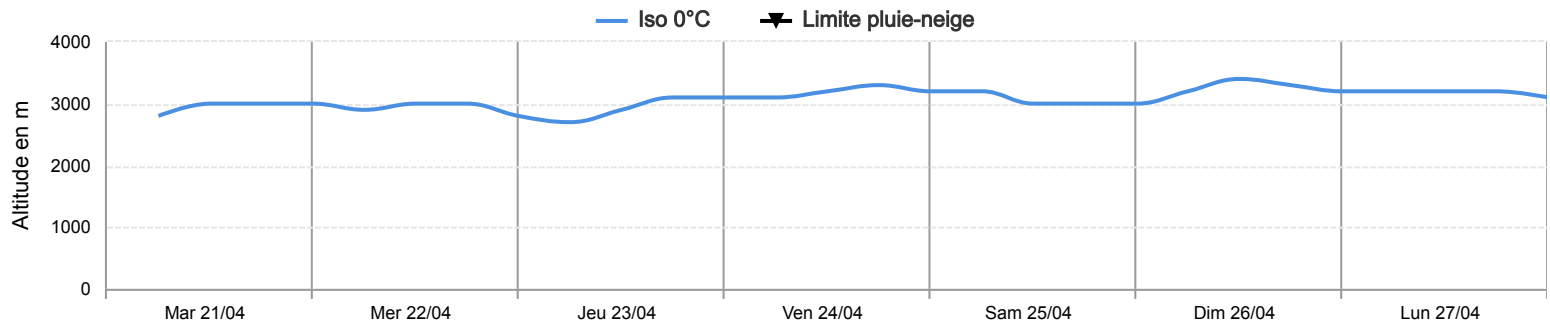

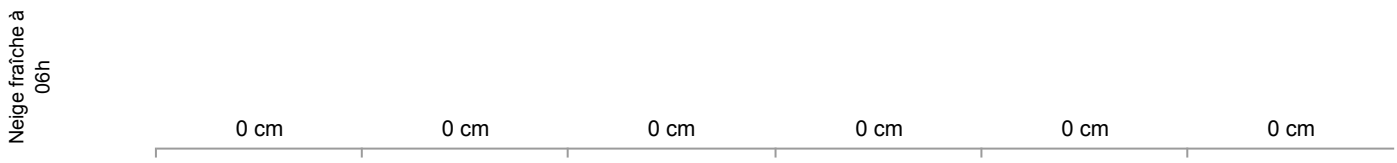

Risque d'avalanche	mar. 21/04	mer. 22/04	jeu. 23/04	ven. 24/04	sam. 25/04	dim. 26/04	lun. 27/04
	2	1	2	2	2	2	2

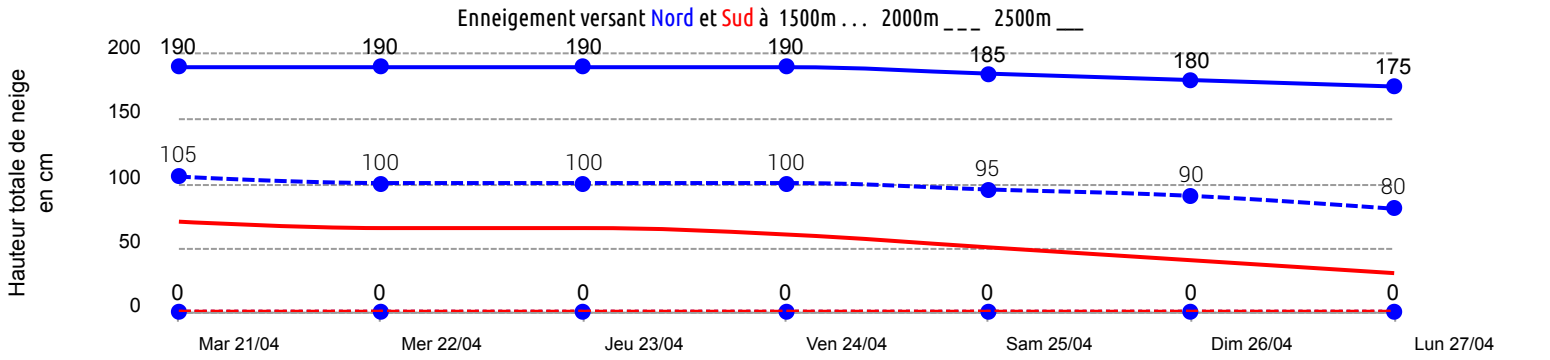

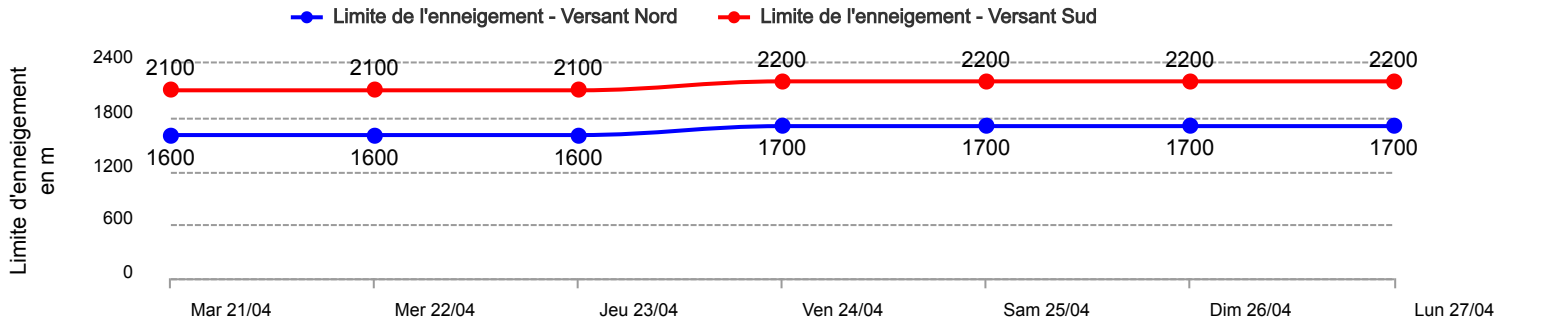

Pour consulter la vigilance en cours, veuillez vous rendre sur le site https://vigilance.meteofrance.fr/fr

Météo-France - 73 avenue de Paris, 94165 Saint-Mandé cedex - Contact : contact@meteo.fr

Rédigé par Météo-France avec la contribution des observateurs du réseau nivo-météorologiques. Partenariat : ANMSM (Maires de Stations de Montagne), DSF (Domaines Skiables de France), ADSP (Directeurs de Pistes et de la Sécurité des Stations de Sports d'Hiver) et autres acteurs de la montagne.

Bulletin neige & avalanches par téléphone au

0 892 68 10 20 Service 0,35 € / min + prix appel