Bulletin d'estimation du risque d'avalanche
(valable en dehors des pistes balisées et ouvertes)

MASSIF : Queyras

Rédigé le lundi 27 avril 2026 à 16h

Estimation des risques pour le : MARDI 28 AVRIL

MANTEAU NEIGEUX PRINTANIER - DENSE ET STABLE

2

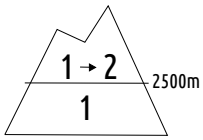

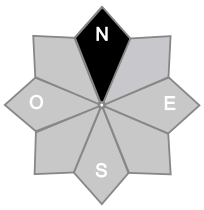

Au-dessus de 2500m indice de risque faible évoluant en limité, plus bas indice faible.

Départs spontanés : peu probables

Déclenchements provoqués : en neige humide sous les skis

Indices de risque : 5 très fort - 4 fort - 3 marqué - 2 limité - 1 faible -- En noir : les pentes les plus dangereuses

Stabilité du manteau neigeux

Situation avalancheuse typique : neige humide

Départs spontanés : peu probables au petit matin après un bon regel nocturne, puis petite activité en neige humide en journée sous l'effet de la douceur et des averses de pluie. Avalanches généralement superficielles de taille1. Une rare taille 2 reste possible dans les pentes nord au dessus de 2500 m.

Déclenchements provoqués : un skieur coupant une pente raide tardivement peut initier un départ de neige humide sous les skis. Taille limitée.

Qualité de la neige

Enneigement très déficitaire pour une mi-avril, notamment en adrets, souvent secs jusqu'à plus de 2500 m.
Hauteurs de neige observées : 35 cm à la Nivôse du Col Agnel à 2630 m.

Limite d'enneigement skiable : au plus bas à 2000 m en ubacs bien protégés ou sur pistes forestières vers le Briançonnais, plus souvent 2000/2100 m.

État de la neige de surface : manteau neigeux printanier, voire de névé en toute orientation sous 2500 m environ et en adrets d'altitude. Bon regel nocturne, puis reprise de l'humidification en journée. Quelques cm de fraîche possible sous une averse de neige en combes nord de haute altitude, au delà de 2800/3000 m.

Aperçu météo pour le mardi 28 avril

	nuit	matin	après-midi	soir

Ciel plus chargé avec des averses l'après-midi. 13° à 2000 m et 4° à 3000 m.

Pluie-Neige			2700 m	
Iso 0 °C	3100 m	3000 m	3100 m	2900 m
Vent 2000 m	↗ 10 km/h	↑ 15 km/h	↗ 25 km/h	↖ 10 km/h
Vent 3000 m	→ 15 km/h	↗ 20 km/h	↗ 30 km/h	↑ 15 km/h

Épaisseur de neige hors-piste

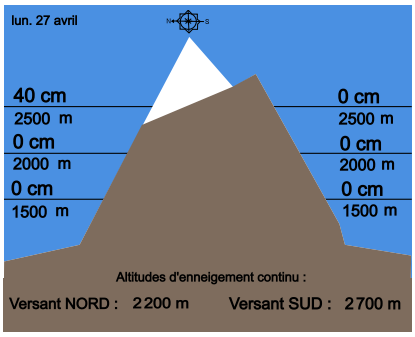

Précipitations à 1800 m

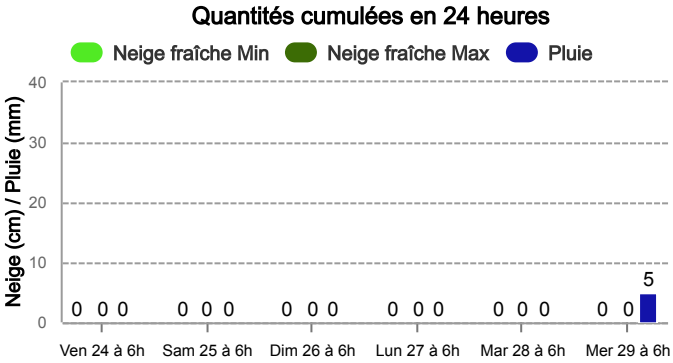

Tendance du mercredi 29 avril

2

Indice de risque limité

Maintien d"un risque limité avec à nouveau un regel nocturne correct puis la poursuite en journée de l'humidification et de la fonte du manteau neigeux.

Pour consulter la vigilance en cours, veuillez vous rendre sur le site https://vigilance.meteofrance.fr/fr

Météo-France - 73 avenue de Paris, 94165 Saint-Mandé cedex - Contact : contact@meteo.fr

Rédigé par Météo-France avec la contribution des observateurs du réseau nivo-météorologiques. Partenariat : ANMSM (Maires de Stations de Montagne), DSF (Domaines Skiables de France), ADSP (Directeurs de Pistes et de la Sécurité des Stations de Sports d'Hiver) et autres acteurs de la montagne.

Bulletin neige & avalanches par téléphone au
0 892 68 10 20 Service 0,35 € / min + prix appel

RÉPUBLIQUE FRANÇAISE
Liberté Égalité Fraternité

METEO FRANCE
À VOS CÔTÉS, DANS UN CLIMAT QUI CHANGE

Bulletin d'estimation du risque d'avalanche

(valable en dehors des pistes balisées et ouvertes)

MASSIF : Queyras

Rédigé le lundi 27 avril 2026 à 16h

Conditions nivo-météo des 7 derniers jours

	mar. 21/04				mer. 22/04				jeu. 23/04				ven. 24/04				sam. 25/04				dim. 26/04				lun. 27/04			
	03h	09h	15h	21h	03h	09h	15h	21h	03h	09h	15h	21h	03h	09h	15h	21h	03h	09h	15h	21h	03h	09h	15h	21h	03h	09h	15h	21h
Météo																												
Vent (km/h)	30	30	35	25	30	35	35	15	15	25	20	10	10	15	20	15	15	10	15	20	20	20	20	10	10	15	20	15
à 3000m	→	→	→	→	→	→	→	↘	←	←	↙	↙	←	↘	→	→	→	→	↘	→	↘	↖	↖	↻	↑	↗	↗	→
Vent (km/h)	10	15	30	10	10	20	25	10	10	20	20	5	5	10	20	5	5	10	25	10	5	10	25	10	5	10	20	10
à 2000m	→	→	↗	→	→	↗	→	←	←	←	↓	↖	↙	↗	↑	↗	↗	↘	↓	↓	↙	↙	↑	↑	↓	↑	↗	↗

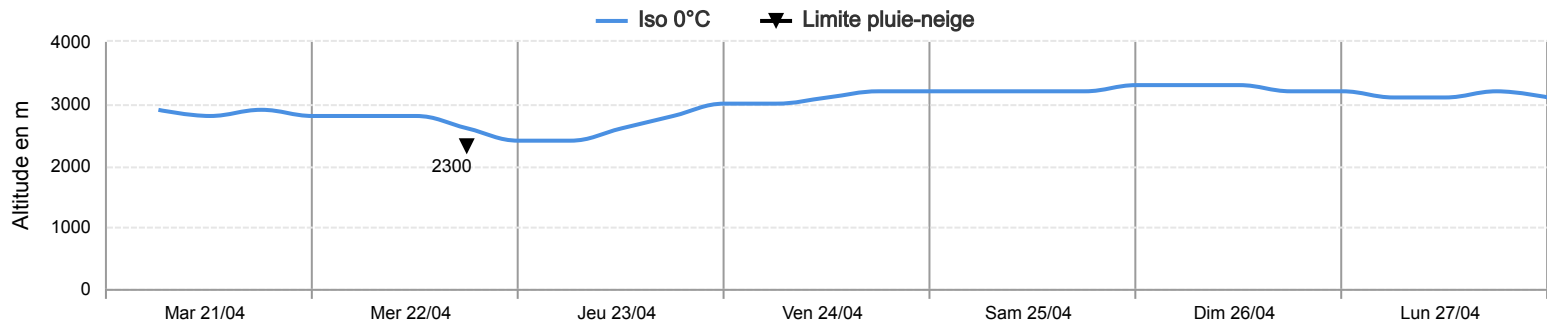

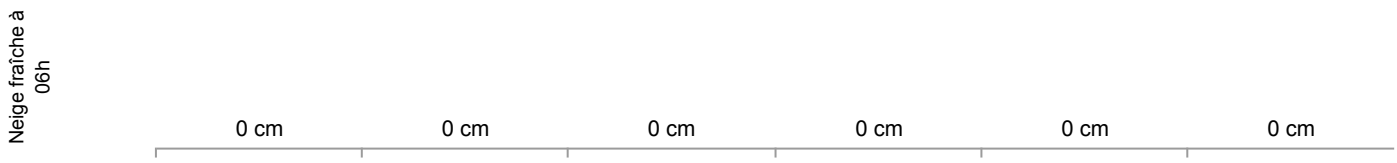

Risque d'avalanche	mar. 21/04	mer. 22/04	jeu. 23/04	ven. 24/04	sam. 25/04	dim. 26/04	lun. 27/04
	2	1	2	2	2	2	2

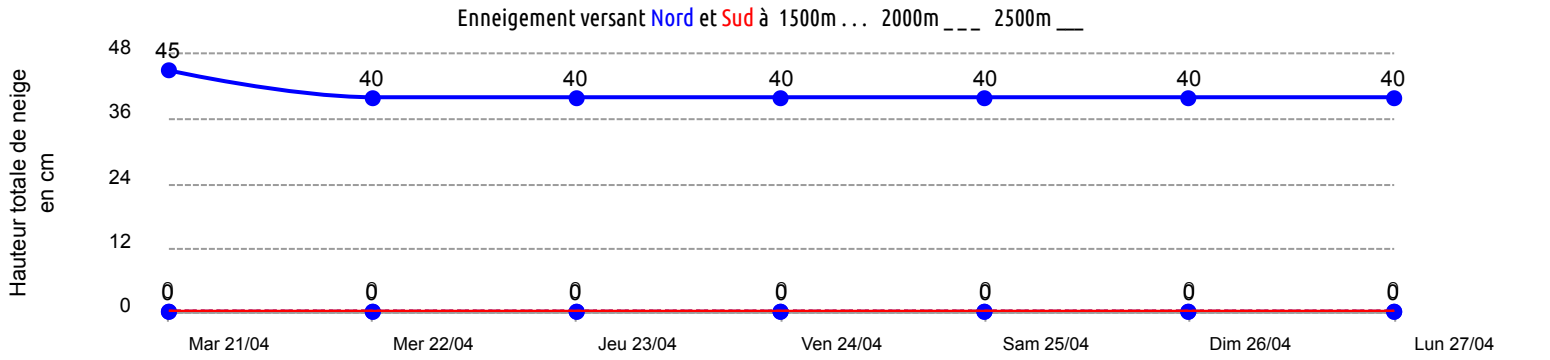

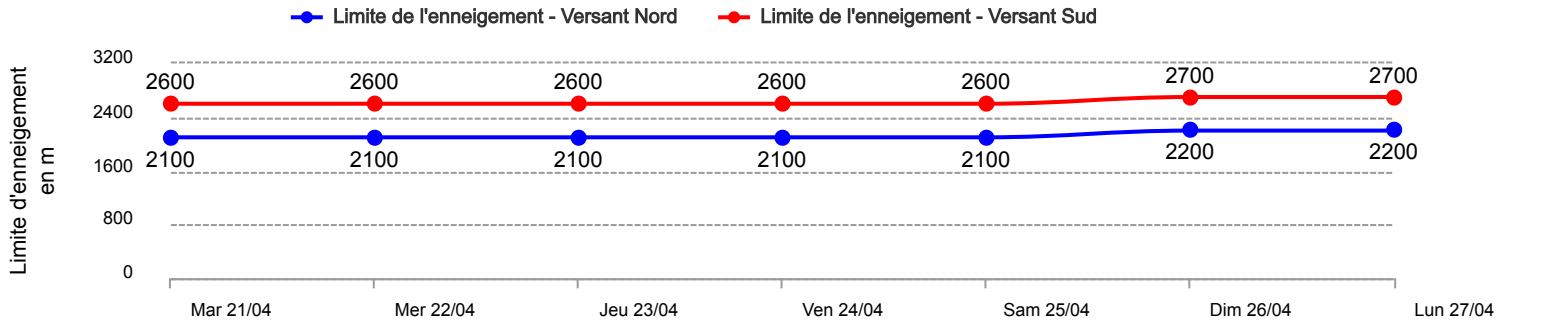

Pour consulter la vigilance en cours, veuillez vous rendre sur le site https://vigilance.meteofrance.fr/fr

Météo-France - 73 avenue de Paris, 94165 Saint-Mandé cedex - Contact : contact@meteo.fr

Rédigé par Météo-France avec la contribution des observateurs du réseau nivo-météorologiques. Partenariat : ANMSM (Maires de Stations de Montagne), DSF (Domaines Skiables de France), ADSP (Directeurs de Pistes et de la Sécurité des Stations de Sports d'Hiver) et autres acteurs de la montagne.

Bulletin neige & avalanches par téléphone au

0 892 68 10 20 Service 0,35 € / min + prix appel