GOBIERNO DE ESPAÑA
VICEPRESIDENCIA TERCERA DEL GOBIERNO
MINISTERIO PARA LA TRANSICIÓN ECOLÓGICA Y EL RETO DEMOGRÁFICO

Boletín de información nivológica y de peligro de aludes

Pirineo Navarro y Aragonés

aemet Agencia Estatal de Meteorología

martes, 28 de abril de 2026

Pronóstico hasta las 24 horas del miércoles, día 29 de abril

(Válido fuera de pistas de esquí balizadas y abiertas)

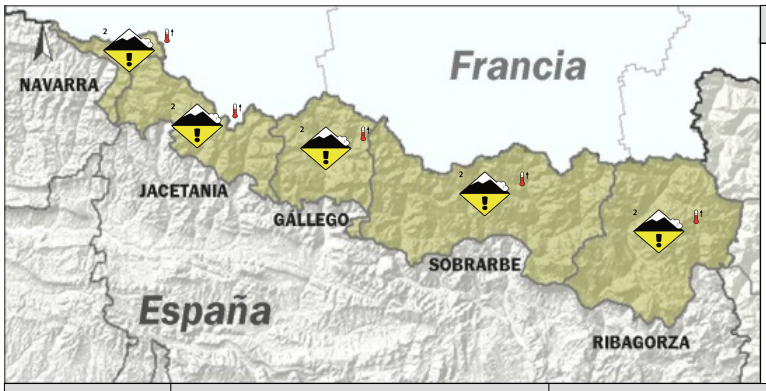

Problemas de aludes

Nieve húmeda

Deslizamientos basales

Macizo	Peligro	Problemas de aludes, cota, orientación, tamaño	Innivación observada (m)
Navarra	2 – 2 – Limitado	Nieve húmeda: 1 – N, O, E, S Deslizamientos basales: 2 – N, O, E, S	2026-04-28 N / S Cota más baja caras N
Jacetania	2 – 2 – Limitado	Nieve húmeda: 2 – N, O, E, S Deslizamientos basales: 2 – N, O, E, S	2026-04-28 N / S Cota más baja caras N
Gállego	2 – 2 – Limitado	Nieve húmeda: 2 – N, O, E, S Deslizamientos basales: 2 – N, O, E, S	2026-04-28 N / S Cota más baja caras N

AEMET. Se autoriza la reproducción de su contenido citando la fuente.

Boletín de información nivológica y de peligro de aludes

Pirineo Navarro y Aragonés

Sobrarbe	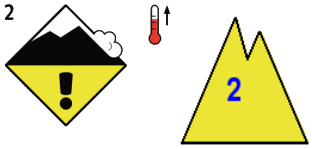 **Limitado**	**Nieve húmeda**  **Deslizamientos basales** 	2026-04-28 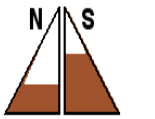 Cota más baja caras N
Ribagorza	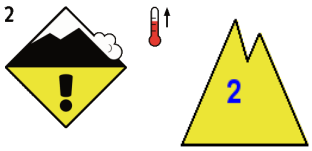 **Limitado**	**Nieve húmeda** **Deslizamientos basales** 	2026-04-28 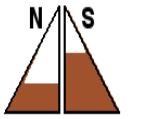 Cota más baja caras N

Estado del manto y observaciones recientes

Prosiguen los procesos de merma y humidificación del manto nivoso a consecuencia de la insolación, las temperaturas elevadas y los chubascos vespertinos, que ayer dejaron alrededor de 10-15 l/m2. Este se halla básicamente restringido a cotas altas y presenta una clara asimetría norte-sur, con las solanas muy peladas y las umbrías con cierta continuidad a partir de 2200 metros, aunque cada vez muestran mayores afloramientos rocosos. En algunos enclaves de éstas todavía se reportan valores en torno a 70-80 cm por encima de 2150 metros. La nieve está muy humidificada, con predominio de grano redondo y rehielo nocturno prácticamente inexistente.

Evolución del manto y peligro de aludes para el miércoles, día 29

Problema de nieve húmeda. Problema de deslizamientos basales.

A partir de media mañana ya se podrán producir aludes de nieve húmeda. El peligro aumentará a lo largo del día con la insolación y las posibles precipitaciones. Estos aludes podrán ser naturales o accidentales y de tamaño pequeño (riesgo de caída) o mediano (capaz de enterrar a una persona).

También se podrán producir algunos deslizamientos basales, preferentemente en laderas herbosas o de roca lisa con la suficiente inclinación y en zonas con grietas de deslizamiento visibles. Serán generalmente de tamaño mediano, aunque no se descarta que localmente puedan adquirir una dimensión mayor.

Predicción meteorológica para el miércoles, día 29

AEMET. Se autoriza la reproducción de su contenido citando la fuente.

Nuboso o con intervalos de nubes medias y altas y de evolución diurna. Calima ligera. Probables algunos chubascos dispersos en la segunda mitad del día, que podrán ir acompañados de tormenta. Cota de nieve: 2800-3000 metros. Temperaturas mínimas en ligero ascenso y máximas con pocos cambios. Viento flojo o moderado de componente sur, con intervalos fuertes en cotas altas.

Datos en la atmósfera libre:

Altitud de la isoterma de 0 ºC: 3100 m
Altitud de la isoterma de -10 ºC: 4700 m

Viento a 1500 m: S 25 km/h
Viento a 3000 m: S 50 km/h

Evolución para el jueves día 30

Nivel de peligro con pocos cambios.

(Información elaborada a partir de los datos recibidos de los refugios de Linza, Lizara, Respomuso, Panticosa, Bachimaña, Góriz, Pineta, Estós, Angel Orús, La Renclusa y Cap de Llauset, de la estación de esquí de Panticosa (lagos) y de Ordesa Pradera)

Escala europea de peligro de aludes

Débil | Limitado | Notable | Fuerte | Muy Fuerte

Problemas de aludes

Nieve reciente | Placas de viento | Capas débiles persistentes | Nieve húmeda | Deslizamientos basales | Sin problema evidente

Nota1: Se recuerda que, siempre que haya nieve, la ausencia total de peligro no existe. Hay que tener presente que en circunstancias desfavorables, con aludes de tamaño 1 (alud pequeño o colada) y tamaño 2 (alud mediano), se pueden sufrir severos daños personales.

Nota2: Los BPA se elaboran en base a información meteorológica así como al estado del manto nivoso a través de sondeos puntuales. Se advierte a los usuarios de la variabilidad de esta información al extrapolarla a zonas extensas de montaña. Por ello, AEMET no se hace responsable de su uso para la toma de decisiones que conciernen a la seguridad personal, ni de los riesgos físicos o materiales de ellas derivadas.

AEMET. Se autoriza la reproducción de su contenido citando la fuente.