Mittwoch 29.04.2026

Veröffentlicht am 28.04.2026 um 17:00

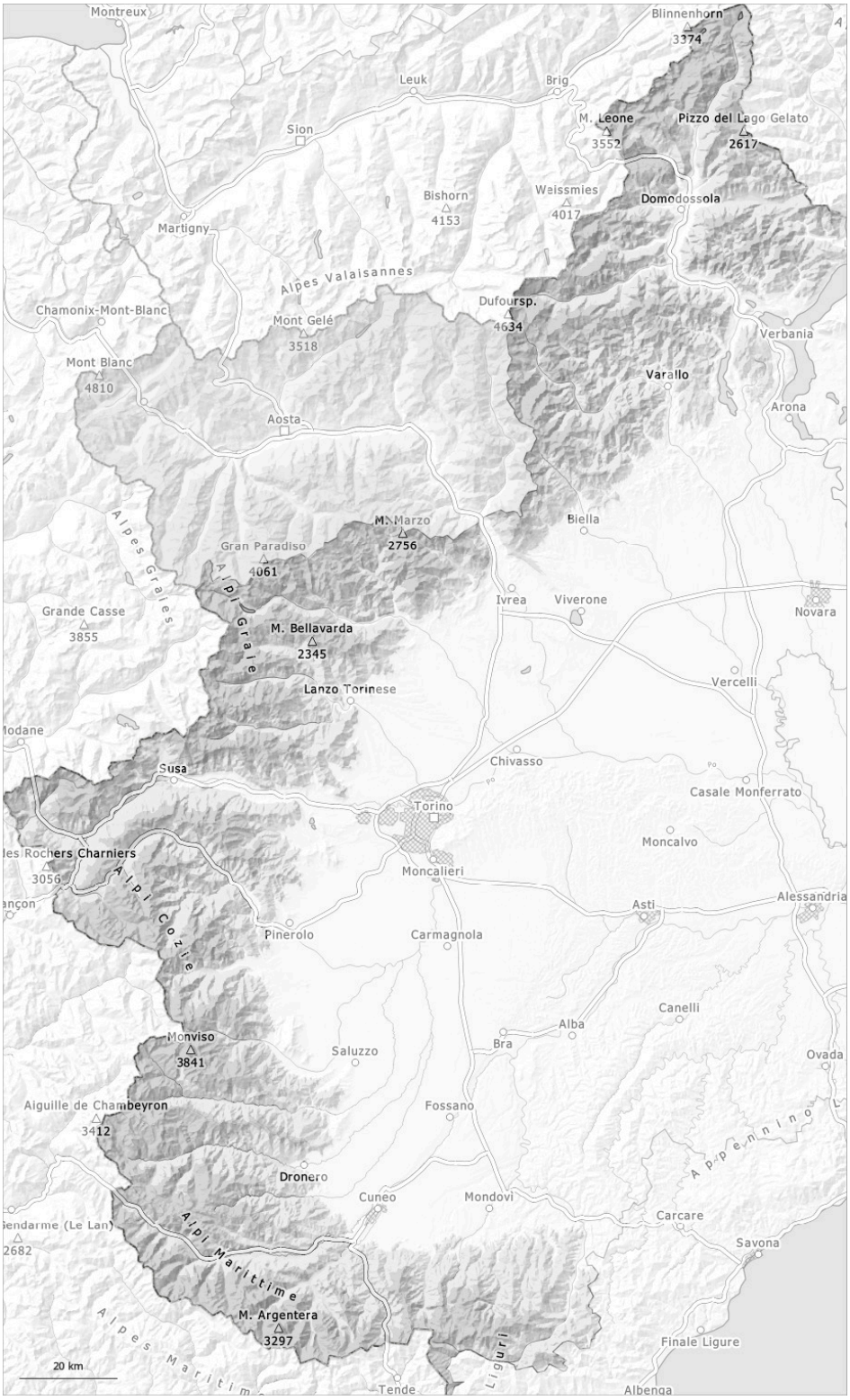

1	2	3	4	5
gering	mäßig	erheblich	groß	sehr groß

Gefahrenstufe 2 - Mäßig

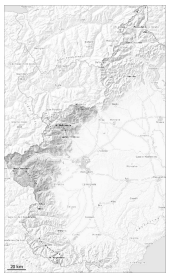

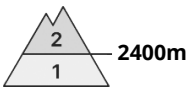

Tendenz: Lawinengefahr bleibt gleich
am Donnerstag, den 30.04.2026

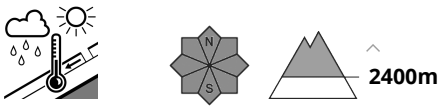

Nassschnee

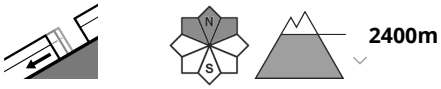

Gleitschnee

Feuchte und nasse Lawinen sind die Hauptgefahr.

In den letzten Stunden fielen lokal oberhalb von rund 2500 m 2 bis 5 cm Schnee. Heute ist es bewölkt. Oberhalb von rund 2500 m: Heute fällt lokal etwas Schnee.

Diese Wetterbedingungen führen ab dem Morgen an allen Expositionen zwischen etwa 2100 und 2700 m zu einer Anfeuchtung der Schneedecke. Mit der Durchnässung sind feuchte Rutsche und Lawinen möglich, aber diese können vereinzelt mittlere Größe erreichen. Dies besonders an steilen Hängen in hohen Lagen und an sehr steilen West-, Nord- und Osthängen in tiefen und mittleren Lagen.

Schneedecke

Gefahrenmuster gm.3: regen auf schnee

Mit milden Temperaturen verfestigte sich die Schneedecke in den letzten Tagen.

Bedeckte Nacht: Die Schneeoberfläche ist nur in hohen Lagen tragfähig gefroren. Tiefe und mittlere Lagen: Die Schneeoberfläche ist kaum gefroren.

Der Regen führt im Tagesverlauf oberhalb von rund 2600 m zu einer raschen Anfeuchtung der Schneedecke.
Unterhalb von rund 2400 m liegt an Südhängen nur wenig Schnee.

Gefahrenstufe 2 - Mäßig

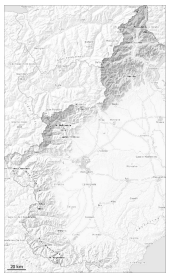

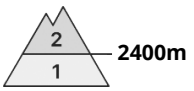

Tendenz: Lawinengefahr bleibt gleich
am Donnerstag, den 30.04.2026

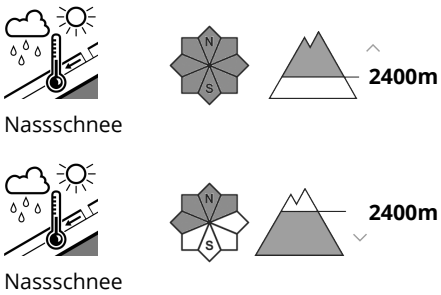

Feuchte und nasse Lawinen sind die Hauptgefahr.

Gestern fielen gebietsweise oberhalb von rund 2500 m 5 cm Schnee, lokal bis zu 10 cm.
Heute ist es bewölkt. Bis am Abend fällt lokal etwas Schnee. Es fällt Regen bis auf 2300 m.

Die Schneeoberfläche gefriert nur knapp und weicht rasch auf. Der Neuschnee verbindet sich recht gut mit dem Altschnee. Einzelne meist kleine spontane Lawinen sind aber möglich.

Die hohe Luftfeuchtigkeit führt ab dem Morgen an allen Expositionen vor allem in mittleren Lagen zu einer Anfeuchtung der Schneedecke. Mit der Durchnässung sind feuchte Rutsche und Lawinen möglich, aber diese können vereinzelt mittlere Größe erreichen.

In den Hauptniederschlagsgebieten und an steilen Hängen ist die Lawinengefahr etwas höher.

Schneedecke

Gefahrenmuster gm.4: kalt auf warm / warm auf kalt | gm.3: regen auf schnee

Hohe Lagen und Hochgebirge: Mit starken Temperaturschwankungen verfestigte sich die Schneedecke. Der obere Teil der Schneedecke ist feucht, mit einer aus lockerem Schnee bestehenden Oberfläche, die auf einer kaum tragfähigen Kruste liegt. Dies in den Gebieten mit Schneefall.

Unterhalb von rund 2500 m: Die Schneedecke ist feucht. Zudem liegt an Südhängen nur wenig Schnee.

Tendenz

Leichter Anstieg der Gefahr von feuchten Lawinen mit der tageszeitlichen Erwärmung und der Sonneneinstrahlung.

Gefahrenstufe 2 - Mäßig

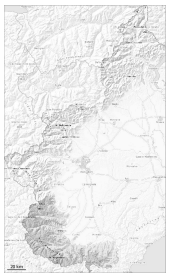

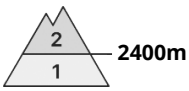

Tendenz: Lawinengefahr bleibt gleich
am Donnerstag, den 30.04.2026

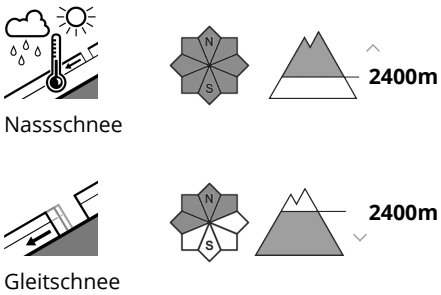

Feuchte und nasse Lawinen sind die Hauptgefahr.

Gestern fiel Regen bis auf 2600 m. Am Morgen ist es bewölkt. Ab dem Mittag fällt lokal Regen bis auf 2500 m. Die Tourenverhältnisse sind ungünstig.

Die Wetterbedingungen führten an allen Expositionen in allen Höhenlagen zu einer Anfeuchtung der Schneedecke.

Mit der Durchnässung sind jederzeit spontane feuchte Lawinen möglich, aber diese können vereinzelt mittlere Größe erreichen. Dies besonders an steilen Hängen in hohen Lagen und an sehr steilen West-, Nord- und Osthängen in tiefen und mittleren Lagen.

Schneedecke

Gefahrenmuster gm.3: regen auf schnee | gm.10: frühjahrssituation

Oberhalb von rund 2500 m: Mit milden Temperaturen verfestigte sich die Schneedecke in den letzten Tagen. Die Schneeoberfläche konnte in der bedeckten Nacht kaum abkühlen und weicht rasch auf.

Unterhalb von rund 2500 m: Der Regen führte verbreitet zu einer massiven Anfeuchtung der Schneedecke. Zudem liegt an Südhängen nur wenig Schnee.