ICGC Institut Cartogràfic i Geològic de Catalunya

Servei Meteorològic de Catalunya meteo.cat

Boletín de peligro de aludes para el Pirineo de Catalunya
Del 28/04/2026 al 29/04/2026

(Válido fuera pistas de esquí y zonas no controladas)

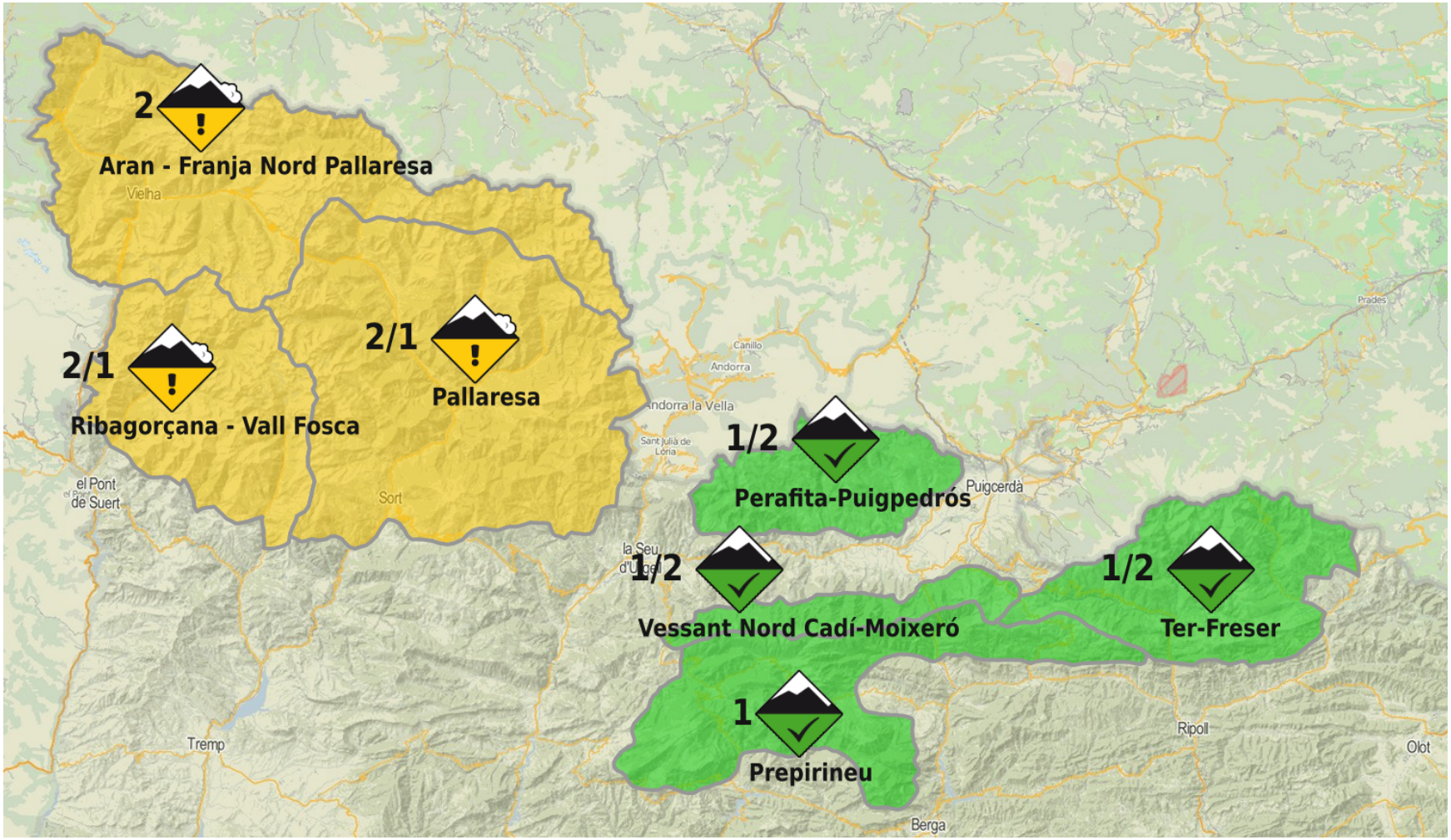

5 MUY FUERTE	4 FUERTE	3 NOTABLE	2 LIMITADO	1 DÉBIL

ICGC Institut Cartogràfic i Geològic de Catalunya

Servei Meteorològic de Catalunya

Boletín de peligro de aludes Aran - Franja Nord Pallaresa Del 28/04/2026 al 29/04/2026

(Válido fuera pistas de esquí y zonas no controladas)

LIMITADO (2)

Situación primaria

Deslizamientos basales | **Distribución** | **Tamaño** | **Origen** | **Tendencia**

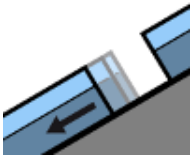

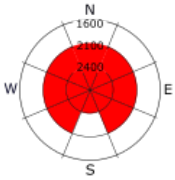

Situación secundaria

Nieve húmeda | **Distribución** | **Tamaño** | **Origen** | **Tendencia**

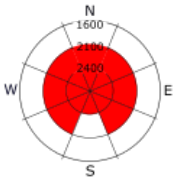

Estado del manto nivoso

El manto se presenta húmedo en su conjunto dadas las lluvias de los últimos días y las altas temperaturas y fuerte insolación. El rehielo superficial del manto es muy débil, restringido a la noche y madrugada sólo. Continuarán los problemas asociados a la fusión del manto.

Son posibles deslizamientos basales, especialmente por encima de unos 2.000 m, en vertientes propicias sobre sustrato liso herboso o rocoso, que podrán alcanzar hasta tamaño 2, medio, en cualquier orientación y hora del día. Habrá que prestar atención a la aparición de grietas en el manto y evitar estos puntos.

También son posibles aludes naturales de nieve húmeda, de tamaño pequeño o medio, así como frecuente caída de bolas, principalmente de media mañana hasta la tarde, en laderas de fuerte pendiente y bajo puntos oscuros como paredes o resaltes rocosos y árboles.

Distribución del manto nivoso

Hay nieve en el suelo con cierta continuidad y esquiable por encima de unos 2.100 m en umbrías y es más discontinua en solanas, a partir de 2.200 m. Los espesores a unos 2.300 m rondan los 100-130 cm, con sobreacumulaciones que todavía se acercan a los 200 cm. Los valores son los normales para la época.

Tendencia para las próximas 48-72h

Nuevos chubascos de cara al jueves y temperaturas altas continuarán manteniendo la inestabilidad del manto por problemas de nieve húmeda. Evolución del peligro: ESTACIONARIO o en LEVE AUMENTO.

El próximo boletín será emitido el día 2026-04-29

5 MUY FUERTE	4 FUERTE	3 NOTABLE	2 LIMITADO	1 DÉBIL

EAWS EUROPEAN AVALANCHE WARNING SERVICES

ICGC Institut Cartogràfic i Geològic de Catalunya

meteo.cat Servei Meteorològic de Catalunya

Boletín de peligro de aludes Ribagorçana - Vall Fosca Del 28/04/2026 al 29/04/2026

(Válido fuera pistas de esquí y zonas no controladas)

LIMITADO (2), a partir de media mañana,
DÉBIL (1), hasta media mañana

Situación primaria

Nieve húmeda

Distribución

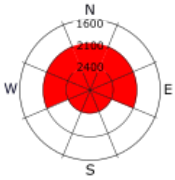

Tamaño

Origen

Tendencia

Situación secundaria

Deslizamientos basales

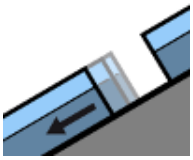

Distribución

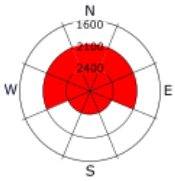

Tamaño

Origen

Tendencia

Estado del manto nivoso

A pesar del débil rehielo superficial que puede experimentar el manto de madrugada, con las altas temperaturas y fuerte radiación se ablanda rápidamente, y a lo largo del día se presenta húmedo en su totalidad. La nieve húmeda y deslizamientos basales siguen siendo los problemas por aludes.

Los aludes de nieve húmeda tendrán lugar principalmente de media mañana hasta la tarde, afectando a cualquier orientación, sobre todo en vertientes de fuerte inclinación y bajo resaltes rocosos o árboles. Los aludes serán por lo general de tamaño pequeño o medio. Los deslizamientos basales, restringidos a las vertientes de sustrato liso, herboso o rocoso, podrán darse también en cualquier orientación y ser de hasta tamaño medio. Habrá que prestar atención a la aparición de grietas en el manto y evitar estos puntos.

Se recomienda empezar las excursiones de montaña temprano y finalizarlas a media mañana.

Distribución del manto nivoso

Hay nieve por encima de unos 2.000 m en N, de forma más continua por encima de unos 2.100 m, y por encima de 2.300-2.400 m en S, a veces discontinua hasta las cumbres, y más continua en cubetas. Los grosores son irregulares pero están alrededor de 50-60 cm de media a unos 2.500 m.

Tendencia para las próximas 48-72h

Nuevos chubascos de cara al jueves y temperaturas altas continuarán manteniendo la inestabilidad del manto por problemas de nieve húmeda. Evolución del peligro: ESTACIONARIO o en LEVE AUMENTO.

El próximo boletín será emitido el día 2026-04-29

5 MUY FUERTE	4 FUERTE	3 NOTABLE	2 LIMITADO	1 DÉBIL

EAWS EUROPEAN AVALANCHE WARNING SERVICES

ICGC Institut Cartogràfic i Geològic de Catalunya

Servei Meteorològic de Catalunya

Boletín de peligro de aludes Pallaresa
Del 28/04/2026 al 29/04/2026

(Válido fuera pistas de esquí y zonas no controladas)

LIMITADO (2), a partir de media mañana,
DÉBIL (1), hasta media mañana

Situación primaria

Nieve húmeda

Distribución

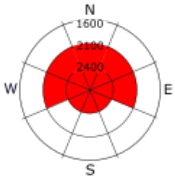

Tamaño

Origen

Tendencia

Situación secundaria

Deslizamientos basales

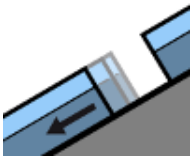

Distribución

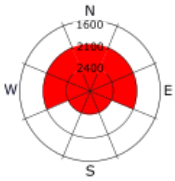

Tamaño

Origen

Tendencia

Estado del manto nivoso

A pesar del débil rehielo superficial que puede experimentar el manto de madrugada, con las altas temperaturas y fuerte radiación se ablanda rápidamente, y a lo largo del día se presenta húmedo en su totalidad. La nieve húmeda y deslizamientos basales siguen siendo los problemas por aludes.

Los aludes de nieve húmeda tendrán lugar principalmente de media mañana hasta la tarde, afectando a cualquier orientación, sobre todo en vertientes de fuerte inclinación y bajo resaltes rocosos o árboles. Los aludes serán por lo general de tamaño pequeño o medio. Los deslizamientos basales, restringidos a las vertientes de sustrato liso, herboso o rocoso, podrán darse también en cualquier orientación y ser de hasta tamaño medio. Habrá que prestar atención a la aparición de grietas en el manto y evitar estos puntos.

Se recomienda empezar las excursiones de montaña temprano y finalizarlas a media mañana.

Distribución del manto nivoso

Hay nieve por encima de unos 2.000 m en N, de forma más continua por encima de unos 2.100 m, y por encima de 2.300-2.400 m en S, a veces discontinua hasta las cumbres, y más continua en cubetas. El manto se presenta a menudo discontinuo y con espesores irregulares y variables, retrocediendo progresivamente en espesor y extensión.

Tendencia para las próximas 48-72h

Nuevos chubascos de cara al jueves y temperaturas altas continuarán manteniendo la inestabilidad del manto por problemas de nieve húmeda. Evolución del peligro: ESTACIONARIO o en LEVE AUMENTO.

El próximo boletín será emitido el día 2026-04-29

5 MUY FUERTE	4 FUERTE	3 NOTABLE	2 LIMITADO	1 DÉBIL

EAWS EUROPEAN AVALANCHE WARNING SERVICES

ICGC Institut Cartogràfic i Geològic de Catalunya

meteo.cat Servei Meteorològic de Catalunya

Boletín de peligro de aludes Perafita-Puigpedrós Del 28/04/2026 al 29/04/2026

(Válido fuera pistas de esquí y zonas no controladas)

DÉBIL (1), LIMITADO (2), a partir de mediodía

Situación primaria

Nieve húmeda

Distribución

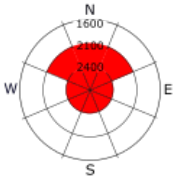

Tamaño

Origen

Tendencia

Situación secundaria

Deslizamientos basales

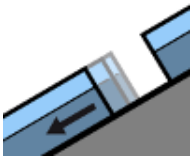

Distribución

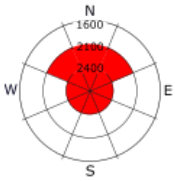

Tamaño

Origen

Tendencia

Estado del manto nivoso

El manto sigue muy húmedo por las últimas lluvias y las altas temperaturas. De madrugada puede haber un débil y superficial rehielo del manto, que desaparece rápidamente durante las primeras horas de la mañana. Los problemas siguen siendo de nieve húmeda y deslizamientos basales. Los aludes de nieve húmeda tendrán lugar principalmente de mediodía hasta la tarde, afectando a cualquier orientación, sobre todo en vertientes de fuerte inclinación y bajo resaltes rocosos o árboles. Los aludes serán por lo general de tamaño pequeño, y localmente alcanzar hasta tamaño 2, mediano. Los deslizamientos basales, restringidos a las vertientes de sustrato liso, herboso o rocoso, podrán darse también en cualquier orientación y ser de tamaño mediano. Habrá que prestar atención a la aparición de grietas en el manto y evitar estos puntos. Se recomienda empezar las excursiones de montaña temprano y finalizarlas a mediodía.

Distribución del manto nivoso

Hay nieve esquiable en umbrías por encima de unos 2.200 m en orientaciones N y presencia de nieve en S por encima de unos 2.300 m de forma discontinua. El manto se presenta a menudo discontinuo, sobre todo en S, y con espesores irregulares, retrocediendo progresivamente en espesor y extensión.

Tendencia para las próximas 48-72h

Nuevos chubascos de cara al jueves y temperaturas altas continuarán manteniendo la inestabilidad del manto por problemas de nieve húmeda. Evolución del peligro: ESTACIONARIO o en LEVE AUMENTO.

El próximo boletín será emitido el día 2026-04-29

5 MUY FUERTE	4 FUERTE	3 NOTABLE	2 LIMITADO	1 DÉBIL

EAWS EUROPEAN AVALANCHE WARNING SERVICES

ICGC Institut Cartogràfic i Geològic de Catalunya

Servei Meteorològic de Catalunya

Boletín de peligro de aludes Vessant Nord Cadí-Moixeró Del 28/04/2026 al 29/04/2026

(Válido fuera pistas de esquí y zonas no controladas)

DÉBIL (1), LIMITADO (2), a partir de mediodía.

Situación primaria

Nieve húmeda

Distribución

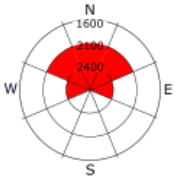

Tamaño

Origen

Tendencia

Estado del manto nivoso

El manto sigue muy húmedo por las últimas lluvias y las altas temperaturas. De madrugada puede haber un débil y superficial rehielo del manto, que desaparece rápidamente durante las primeras horas de la mañana. Los aludes de nieve húmeda tendrán lugar principalmente de mediodía hasta la tarde, afectando a cualquier orientación, sobre todo a las canales y en laderas de fuerte inclinación, y bajo resaltes rocosos o árboles. Serán por lo general aludes de pequeño tamaño, y localmente podrán alcanzar hasta tamaño 2, mediano. Las canales, donde el manto nivoso tiene más grosor, pueden convertirse en los sectores más peligrosos, así como el terreno trampa donde un alud pequeño podría llegar a enterrarnos. Se recomienda empezar las actividades de montaña temprano y finalizarlas a mediodía.

Distribución del manto nivoso

Hay nieve por encima de unos 2.000 m en N y de unos 2.200 m en Sur, de forma muy escasa y discontinua. Los espesores rondan, a umbrías, los 80-100 cm a unos 2.300 m. Estos valores están por encima de los normales para la época.

Tendencia para las próximas 48-72h

Nuevos chubascos de cara al jueves y temperaturas altas continuarán manteniendo la inestabilidad del manto por problemas de nieve húmeda. Evolución del peligro: ESTACIONARIO o en LEVE AUMENTO.

El próximo boletín será emitido el día 2026-04-29

5 MUY FUERTE	4 FUERTE	3 NOTABLE	2 LIMITADO	1 DÉBIL

EAWS EUROPEAN AVALANCHE WARNING SERVICES

ICGC Institut Cartogràfic i Geològic de Catalunya

Servei Meteorològic de Catalunya

Boletín de peligro de aludes Prepirineu
Del 28/04/2026 al 29/04/2026

(Válido fuera pistas de esquí y zonas no controladas)

DÉBIL (1).

Situación primaria

Nieve húmeda

Distribución

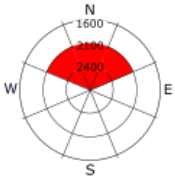

Tamaño

Origen

Tendencia

Estado del manto nivoso

El manto nivoso va quedando restringido a las cotas más altas del sector y en canales y cubetas. De madrugada puede haber un débil y superficial rehielo del manto, que desaparece rápidamente durante las primeras horas de la mañana. Por lo general, el manto se presenta húmedo en su totalidad y los problemas quedan restringidos a aludes de nieve húmeda. La probabilidad de aludes se concentrará principalmente de media mañana hasta la tarde, afectando a cualquier orientación, sobre todo en vertientes de fuerte inclinación y bajo resaltes rocosos o árboles. Los aludes serán por lo general en forma de purgas o de pequeño tamaño. Se recomienda empezar las excursiones de montaña temprano y finalizarlas a media mañana.

Distribución del manto nivoso

En orientación S el manto es discontinuo y escaso hasta las cimas, en N hay presencia de nieve por encima de unos 2.100 m. El manto se presenta a menudo discontinuo y con espesores irregulares, retrocediendo progresivamente en espesor y extensión.

Tendencia para las próximas 48-72h

Nuevos chubascos de cara al jueves y temperaturas altas continuarán manteniendo la inestabilidad del manto por problemas de nieve húmeda. Evolución del peligro: ESTACIONARIO o en LEVE AUMENTO.

El próximo boletín será emitido el día 2026-04-29

5 MUY FUERTE	4 FUERTE	3 NOTABLE	2 LIMITADO	1 DÉBIL

EAWS EUROPEAN AVALANCHE WARNING SERVICES

ICGC Institut Cartogràfic i Geològic de Catalunya

Servei Meteorològic de Catalunya

Boletín de peligro de aludes Ter-Freser
Del 28/04/2026 al 29/04/2026

(Válido fuera pistas de esquí y zonas no controladas)

DÉBIL (1), LIMITADO (2), a partir de mediodía

Situación primaria

Deslizamientos basales

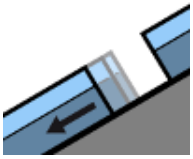

Distribución

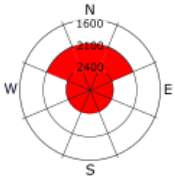

Tamaño

Origen

Tendencia

Situación secundaria

Nieve húmeda

Distribución

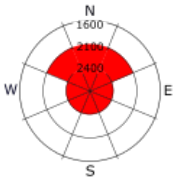

Tamaño

Origen

Tendencia

Estado del manto nivoso

El manto sigue muy húmedo por las últimas lluvias y las altas temperaturas. De madrugada puede haber un débil y superficial rehielo del manto, que desaparece rápidamente durante las primeras horas de la mañana. Los problemas siguen siendo de nieve húmeda y deslizamientos basales. Los aludes de nieve húmeda tendrán lugar principalmente de mediodía hasta la tarde, afectando a cualquier orientación, sobre todo en vertientes de fuerte inclinación y bajo resaltes rocosos o árboles. Los aludes serán por lo general de tamaño pequeño, y localmente alcanzar hasta tamaño 2, mediano. Los deslizamientos basales, restringidos a las vertientes de sustrato liso, herboso o rocoso, podrán darse también en cualquier orientación y ser de tamaño mediano. Habrá que prestar atención a la aparición de grietas en el manto y evitar estos puntos. Se recomienda empezar las excursiones de montaña temprano y finalizarlas a mediodía.

Distribución del manto nivoso

Hay nieve por encima de unos 2.000 m en N y de unos 2.200 m en S, de forma discontinua. El manto se presenta a menudo discontinuo y con espesores irregulares, retrocediendo progresivamente en espesor y extensión.

Tendencia para las próximas 48-72h

Nuevos chubascos de cara al jueves y temperaturas altas continuarán manteniendo la inestabilidad del manto por problemas de nieve húmeda. Evolución del peligro: ESTACIONARIO o en LEVE AUMENTO.

El próximo boletín será emitido el día 2026-04-29

5 MUY FUERTE	4 FUERTE	3 NOTABLE	2 LIMITADO	1 DÉBIL

EAWS EUROPEAN AVALANCHE WARNING SERVICES