BUTLLETÍ DEL PERILL D'ALLAUS DEL PRINCIPAT D'ANDORRA

Préparé le 28/04/2026 16:00
Prochaine mise à jour le 29/04/2026 à 16h

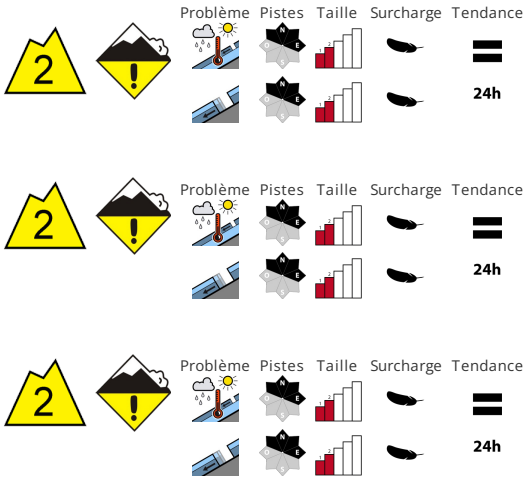

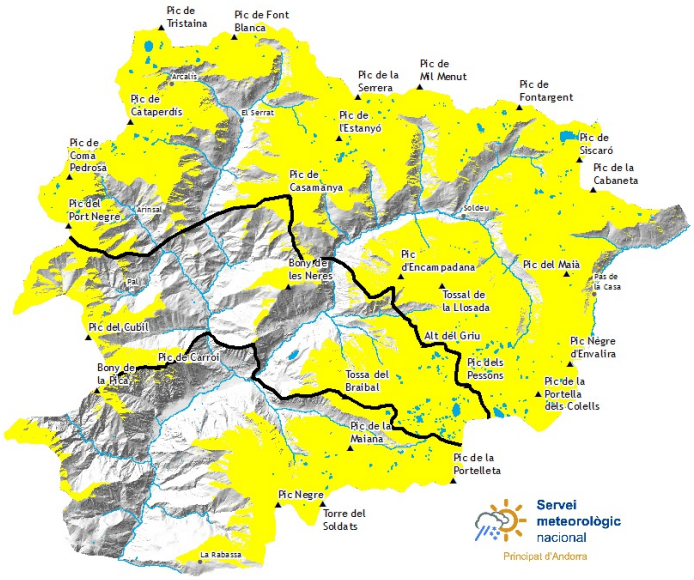

STABILITÉ DU MANTEAU NEIGEUX

Les conditions sont printanières. Des avalanches humides et mouillées de moyenne taille sont ils sont possibles avec l'humidification. Prudence en présence de fissures de glissement.. En outre, des avalanches de glissement sont possibles à tout moment.. Prudence surtout à partir des zones de départ pas encore totalement déchargées. À toutes les expositions le danger d'avalanches mouillées et de glissement augmente au sein du degré de danger en cours de journée au grade 1 (faible). Le danger d'avalanches subsiste. Des départs spontanés d'avalanches et les observations sur le terrain confirment la structure fragile du manteau neigeux.

QUALITÈ DE LA NEIGE

De manière généralisée le manteau neigeux est humide.. Le rayonnement nocturne est généralement fortement réduit.. Le soleil et la chaleur entraînent en cours de journée une humidification croissante du manteau neigeux. Les zones présentant des fissures de glissement doivent être évitées.. Les randonnées devraient être commencées et terminées très tôt..

EPAISSEUR DE NEIGE HORS PISTE

Zone nord		Epaisseur de neige			Zone centre		Epaisseur de neige			Zone sud		Epaisseur de neige		
Nival manteau		1500m	2000m	2500m	**Nival manteau**		1500m	2000m	2500m	**Nival manteau**		1500m	2000m	2500m
N	1800 m	0 cm	100 cm	200 cm	N	1800 m	0 cm	90 cm	130 cm	N	1800 m	0 cm	90 cm	130 cm
S	2200 m	0 cm	0 cm	150 cm	S	2200 m	0 cm	0 cm	100 cm	S	2200 m	0 cm	0 cm	90 cm

Govern d'Andorra

Aquest butlletí ha estat elaborat seguint les normes i recomanacions de l'**European Avalanche Warning Services**, del qual el **Servei meteorològic Nacional** n'és membre

BUTLLETÍ DEL PERILL D'ALLAUS DEL PRINCIPAT D'ANDORRA

Servei meteorològic nacional
Principat d'Andorra

Des informations détaillées par espace naturel protégé

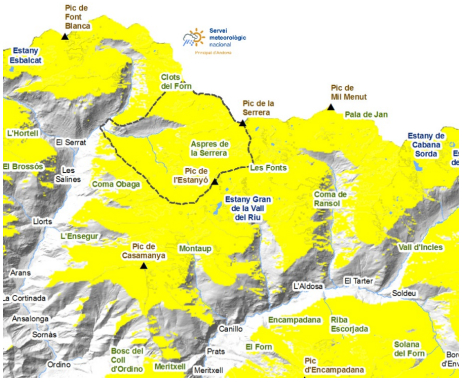

SORTENY

L'enneigement devient de plus en plus précaire. Le gel nocturne n'est ni bon ni efficace, donc la circulation dans la neige qui n'a pas été compactée tout au long de la saison est plus difficile. , , ,

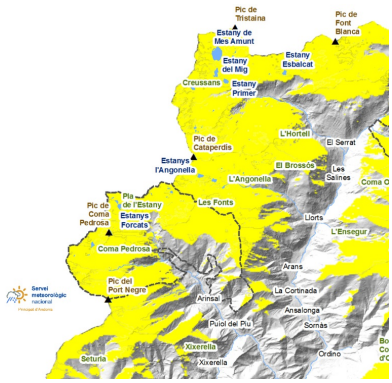

COMAPEDROSA

La neige est plus humide que la semaine dernière. Attention aux ponts de glace au-dessus des torrents, car ils seront fragilisés par l'augmentation du débit des rivières et l'affaiblissement du manteau neigeux. , , ,

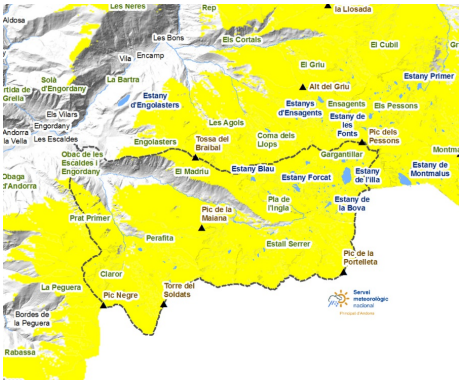

MADRIU-PERAFITA-CLAROR

L'humidité atteint les couches les plus profondes du manteau, favorisant un cycle d'avalanches naturelles de neige mouillée et de glissements basaux. Depuis l'Estall Serrer en aval, il ne reste plus de neige continue. , , ,

Govern d'Andorra

EAWS
EUROPEAN AVALANCHE WARNING SERVICES

Aquest butlletí ha estat elaborat seguint les normes i recomanacions de l'**European Avalanche Warning Services**, del qual el **Servei meteorològic Nacional** n'és membre

BUTLLETÍ DEL PERILL D'ALLAUS DEL PRINCIPAT D'ANDORRA

Servei meteorològic nacional
Principat d'Andorra

Couche de neige fraiche des derniers jours (De 24 h mesurée à 06:00 h UTC)

	24/04/2026	25/04/2026	26/04/2026	27/04/2026
FEDA (Central)	0 cm	0 cm	0 cm	0 cm
Aixàs	0 cm	0 cm	0 cm	0 cm
Engolasters - FEDA	0 cm	0 cm	0 cm	0 cm
Ransol - FEDA	0 cm	0 cm	0 cm	0 cm
Fontverd	0 cm	0 cm	0 cm	0 cm
Setúria	0 cm	0 cm	0 cm	3 cm
Coll Ordino	0 cm	0 cm	0 cm	0 cm
Bony de les Neres	0 cm	0 cm	0 cm	0 cm
Grau Roig - FEDA	0 cm	0 cm	0 cm	0 cm
Caborreu	0 cm	0 cm	0 cm	0 cm
Sorteny	0 cm	0 cm	0 cm	0 cm
Coll Pa	0 cm	0 cm	0 cm	0 cm
Perafita	0 cm	0 cm	0 cm	0 cm
Tossa Espiolets	0 cm	0 cm	0 cm	0 cm
La Solana	0 cm	0 cm	0 cm	0 cm
Vall del Riu FEDA	0 cm	0 cm	0 cm	0 cm
Envalira Antenes	0 cm	0 cm	0 cm	0 cm
Les Fonts d'Arinsal	0 cm	0 cm	0 cm	0 cm