Bulletin d'estimation du risque d'avalanche
(valable en dehors des pistes balisées et ouvertes)

MASSIF : Beaufortain

Rédigé le mardi 28 avril 2026 à 15h

Estimation des risques pour le : MERCREDI 29 AVRIL

HUMIDIFICATION EN PROFONDEUR ACCÉLÉRÉE PAR LES AVERSES

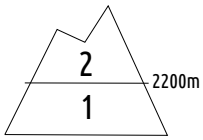

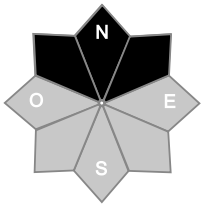

Au-dessus de 2200m indice de risque limité, plus bas indice faible.

Départs spontanés : très rares mais possibles grands départs en neige humide.

Déclenchements provoqués : coulées humides sous les skis.

Indices de risque : 5 très fort - 4 fort - 3 marqué - 2 limité - 1 faible -- En noir : les pentes les plus dangereuses

Stabilité du manteau neigeux

Situation avalancheuse typique : neige humide

Départs spontanés :
- Au dessus de 2200 m en versants Est et Ouest d'altitude, mais surtout en Nord, l'humidification s'accentue en journée sous les averses et gagne un peu plus en profondeur. **Un rare départ linéaire est encore possible** quand l'humidification atteint une couche fragile enfouie (très présentes à la base du manteau dans les versants Nord), **une moyenne à grande avalanche (taille 2 voir 3)** est alors possible.
- Sous 2200 m en Nord et à toute altitude en Sud, les pentes sont maintenant bien stabilisées, avec une neige dense de type névé sur toute l'épaisseur du manteau.

Déclenchements provoqués : peu probables sauf avalanche de neige humide (pourrie) sous les skis en coupant une pente trop humidifiée.

Autres : chutes de corniches signalées et attendues.

Qualité de la neige

Enneigement : déficitaire pour la saison à cause de la chaleur durablement excessive. La très haute montagne est quasi sèche à cause des épisodes de vent de l'hiver et de l'absence de précipitations significative ces dernières semaines.

Limite skiable : vers 1500 m en nord, 1900 m en sud en pente douce, bien plus haut en pente sud raide.

Qualité de la neige : Sous 2200 m en Nord et bien plus haut dans les autres orientations, neige de névé qui reste dense toute la journée. Au-dessus, difficile de trouver de bonnes conditions de ski de printemps, le regel est aléatoire, rendant parfois la neige pourrie dès le début de journée, cet état de neige se généralise l'après-midi sous les averses. Il faut monter au-dessus de 3000 m en plein Nord pour espérer trouver quelques restes de neige froide, très localement en vieille poudre, mais souvent bétonnée par le vent.

Aperçu météo pour le mercredi 29 avril

nuit	matin	après-midi	soir

Voilé à nuageux le matin, puis les cumulus se développent sur le relief pour donner quelques averses localement ORAGEUSES.

Pluie-Neige	2 700 m			
Iso 0 °C	2 800 m	2 900 m	3 000 m	3 000 m
Vent 2000 m	↖ 10 km/h	↗ 5 km/h	↗ 5 km/h	↗ 5 km/h
Vent 3000 m	↗ 25 km/h	↗ 10 km/h	↗ 10 km/h	→ 10 km/h

Épaisseur de neige hors-piste

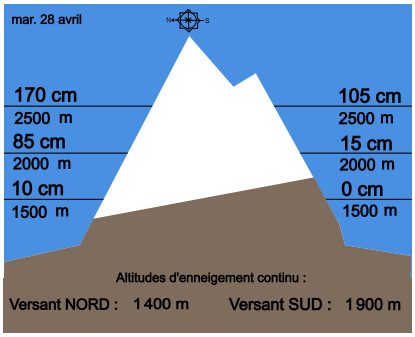

Précipitations à 1800 m

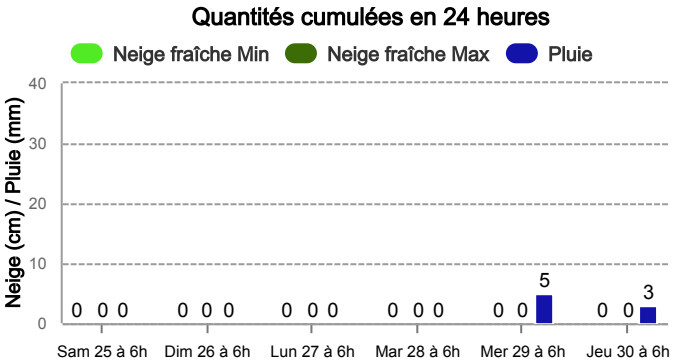

Tendance du jeudi 30 avril

Indice de risque limité

Risque stationnaire, le temps est plus sec mais la chaleur favorise des départs humides l'après-midi.

Pour consulter la vigilance en cours, veuillez vous rendre sur le site https://vigilance.meteofrance.fr/fr

Météo-France - 73 avenue de Paris, 94165 Saint-Mandé cedex - Contact : contact@meteo.fr

Rédigé par Météo-France avec la contribution des observateurs du réseau nivo-météorologiques. Partenariat : ANMSM (Maires de Stations de Montagne), DSF (Domaines Skiables de France), ADSP (Directeurs de Pistes et de la Sécurité des Stations de Sports d'Hiver) et autres acteurs de la montagne.

Bulletin neige & avalanches par téléphone au **0 892 68 10 20** Service 0,35 € / min + prix appel

RÉPUBLIQUE FRANÇAISE
Liberté Égalité Fraternité

METEO FRANCE
À VOS CÔTÉS, DANS UN CLIMAT QUI CHANGE

Bulletin d'estimation du risque d'avalanche
(valable en dehors des pistes balisées et ouvertes)

MASSIF : Beaufortain

Rédigé le mardi 28 avril 2026 à 15h

Conditions nivo-météo des 7 derniers jours

	mer. 22/04				jeu. 23/04				ven. 24/04				sam. 25/04				dim. 26/04				lun. 27/04				mar. 28/04			
	03h	09h	15h	21h	03h	09h	15h	21h	03h	09h	15h	21h	03h	09h	15h	21h	03h	09h	15h	21h	03h	09h	15h	21h	03h	09h	15h	21h
Météo																												
Vent (km/h)	25	25	15	10	10	20	15	10	5	15	20	10	10	20	25	10	10	10	15	15	10	10	15	15	15	15	20	25
à 3000m																												
Vent (km/h)	10	15	10	15	15	10	10	5	5	10	15	5	5	15	20	5	5	5	10	5	5	5	10	10	10	10	10	10
à 2000m																												

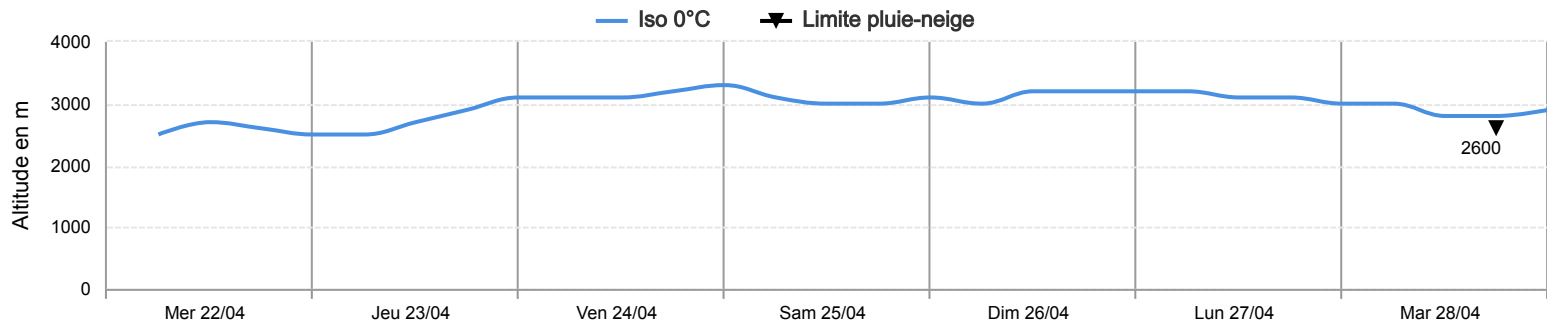

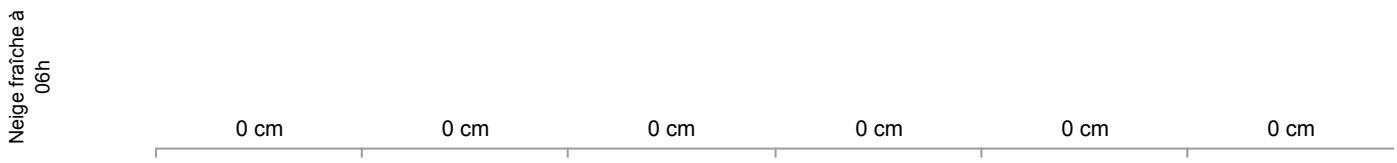

Risque d'avalanche	mer. 22/04	jeu. 23/04	ven. 24/04	sam. 25/04	dim. 26/04	lun. 27/04	mar. 28/04
	2	2	2	2	2	2	2

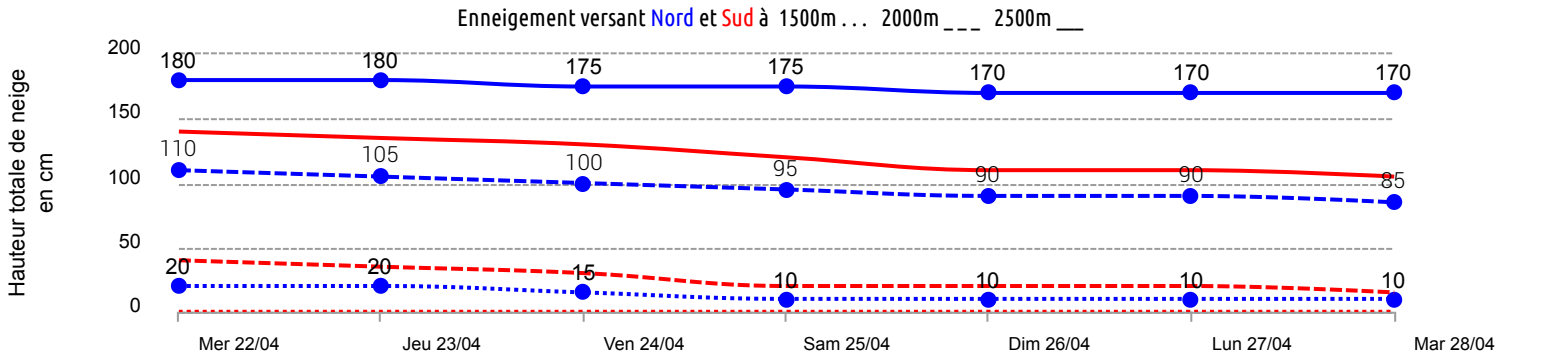

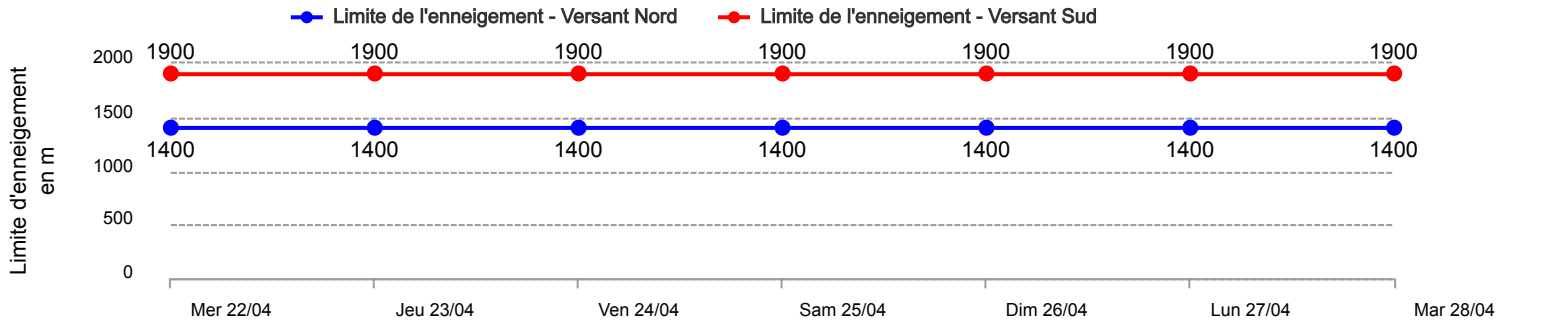

Pour consulter la vigilance en cours, veuillez vous rendre sur le site https://vigilance.meteofrance.fr/fr

Météo-France - 73 avenue de Paris, 94165 Saint-Mandé cedex - Contact : contact@meteo.fr

Bulletin neige & avalanches par téléphone au **0 892 68 10 20** Service 0,35 € / min + prix appel

Rédigé par Météo-France avec la contribution des observateurs du réseau nivo-météorologiques. Partenariat : ANMSM (Maires de Stations de Montagne), DSF (Domaines Skiables de France), ADSP (Directeurs de Pistes et de la Sécurité des Stations de Sports d'Hiver) et autres acteurs de la montagne.