Bulletin d'estimation du risque d'avalanche

(valable en dehors des pistes balisées et ouvertes)

MASSIF : Bauges

Rédigé le mardi 28 avril 2026 à 16h

Estimation des risques pour le : MERCREDI 29 AVRIL

MANTEAU NEIGEUX PRINTANIER.

1

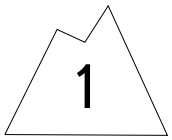

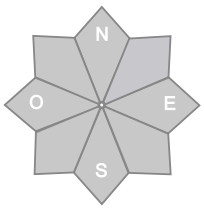

Indice de risque faible.

Départs spontanés : avalanche de neige humide

Déclenchements provoqués : De la neige humide peut couler sous les skis.

Indices de risque : 5 très fort - 4 fort - 3 marqué - 2 limité - 1 faible -- En noir : les pentes les plus dangereuses

Stabilité du manteau neigeux

Situation avalancheuse typique : neige humide avalanches de fond

Déclenchements provoqués :
* départ ponctuel en neige humide, sous les skis. Taille 1. Causé par le couvert nuageux et les averses.

Départs spontanés :
* rares avalanches de neige humide, plus nombreuses sous les averses puis au fil du réchauffement diurne. Le regel, parfois plus hétérogène peut favoriser un départ dès la matinée. Taille 1 (petite).
* rares plaques de fond dans les zones herbeuses ou les dalles rocheuses, à toute heure du jour ou de la nuit. Taille 2 (moyenne).

Qualité de la neige

Enneigement :
Pour la saison, l'enneigement est déficitaire à très déficitaire.
On peut chausser les skis au-dessus de 1700 m en nord. Les versants sud sont secs.

Qualité de la neige ce mercredi :
neige de névé à toute altitude avec un mauvais regel nocturne.

Aperçu météo pour le mercredi 29 avril

nuit	matin	après-midi	soir

Belle éclaircies le matin, puis des averses s'installent l'après-midi. De 7°C à 12°C à 1500 m.

Pluie-Neige	2 600 m			
Iso 0 °C	2 800 m	2 900 m	3 000 m	3 000 m
Vent 1500 m	10 km/h	10 km/h	10 km/h	5 km/h
Vent 2000 m	20 km/h	5 km/h	5 km/h	5 km/h

Épaisseur de neige hors-piste

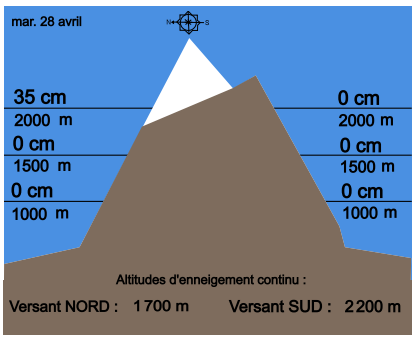

Précipitations à 1800 m

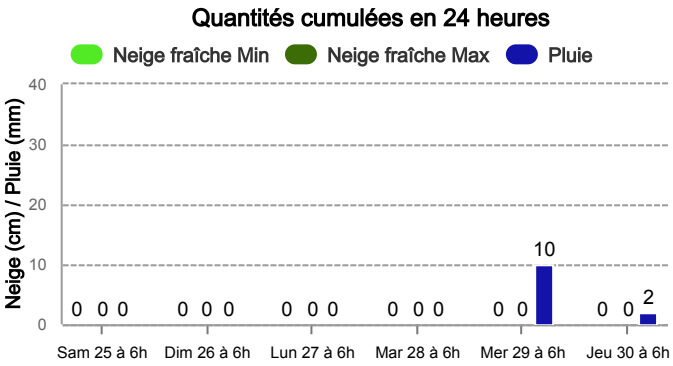

Tendance du jeudi 30 avril

1

Indice de risque faible

Départs de neige humide en journée. La journée est plus sèche et ensoleillée avec des cumulus qui gonflent dans les massifs.

Pour consulter la vigilance en cours, veuillez vous rendre sur le site https://vigilance.meteofrance.fr/fr

Météo-France - 73 avenue de Paris, 94165 Saint-Mandé cedex - Contact : contact@meteo.fr

Rédigé par Météo-France avec la contribution des observateurs du réseau nivo-météorologiques. Partenariat : ANMSM (Maires de Stations de Montagne), DSF (Domaines Skiables de France), ADSP (Directeurs de Pistes et de la Sécurité des Stations de Sports d'Hiver) et autres acteurs de la montagne.

Bulletin neige & avalanches par téléphone au

0 892 68 10 20 Service 0,35 € / min + prix appel

Bulletin d'estimation du risque d'avalanche

(valable en dehors des pistes balisées et ouvertes)

MASSIF : Bauges

Rédigé le mardi 28 avril 2026 à 16h

Conditions nivo-météo des 7 derniers jours

	mer. 22/04				jeu. 23/04				ven. 24/04				sam. 25/04				dim. 26/04				lun. 27/04				mar. 28/04			
	03h	09h	15h	21h	03h	09h	15h	21h	03h	09h	15h	21h	03h	09h	15h	21h	03h	09h	15h	21h	03h	09h	15h	21h	03h	09h	15h	21h
Météo																												
Vent (km/h)	20	15	10	10	10	10	10	10	10	10	10	10	15	10	20	25	10	15	15	10	10	5	10	15	15	15	25	15
à 2000m																												
Vent (km/h)	10	10	5	5	5	5	5	5	5	5	5	5	5	5	15	15	5	10	10	10	5	5	10	10	10	10	15	10
à 1500m																												

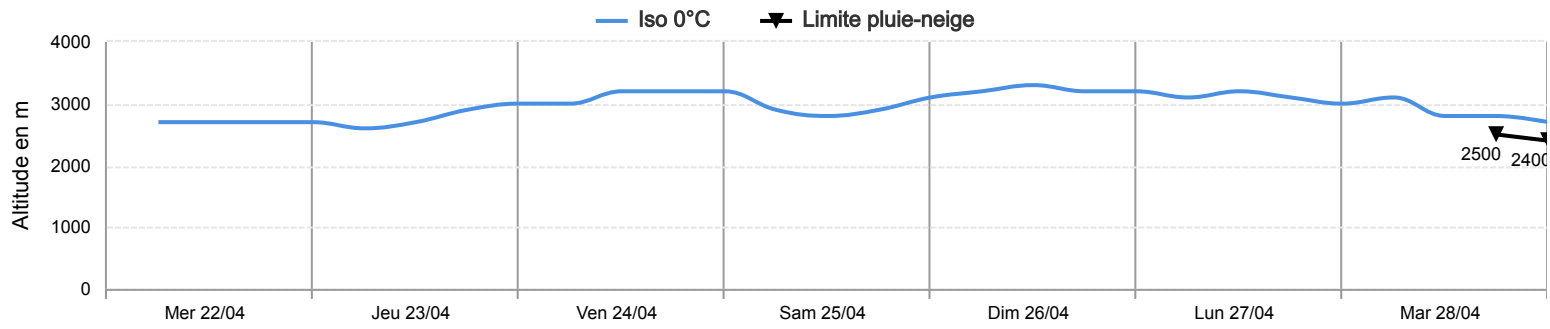

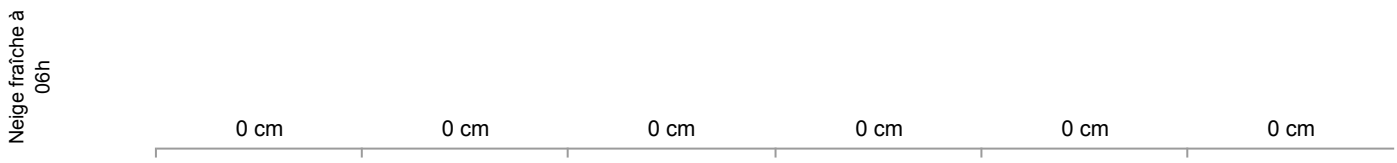

Risque d'avalanche	mer. 22/04	jeu. 23/04	ven. 24/04	sam. 25/04	dim. 26/04	lun. 27/04	mar. 28/04
	1	1	1	1	1	1	1

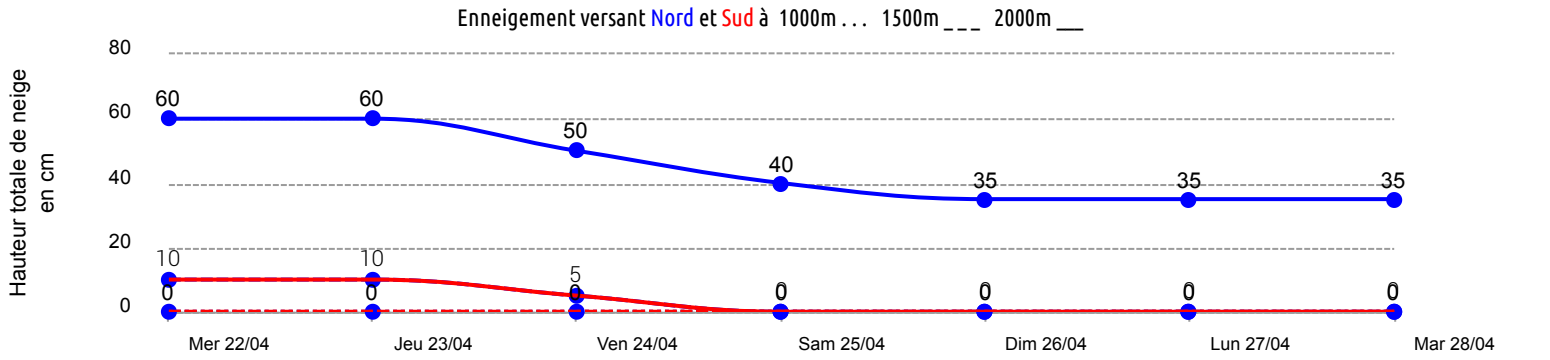

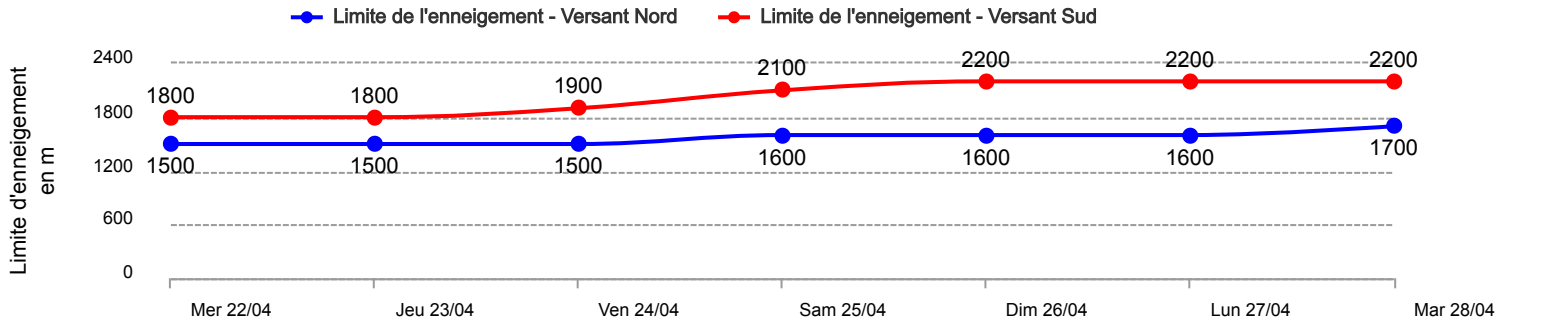

Pour consulter la vigilance en cours, veuillez vous rendre sur le site https://vigilance.meteofrance.fr/fr

Météo-France - 73 avenue de Paris, 94165 Saint-Mandé cedex - Contact : contact@meteo.fr

Bulletin neige & avalanches par téléphone au

0 892 68 10 20 Service 0,35 € / min + prix appel

Rédigé par Météo-France avec la contribution des observateurs du réseau nivo-météorologiques. Partenariat : ANMSM (Maires de Stations de Montagne), DSF (Domaines Skiables de France), ADSP (Directeurs de Pistes et de la Sécurité des Stations de Sports d'Hiver) et autres acteurs de la montagne.