Bulletin d'estimation du risque d'avalanche
(valable en dehors des pistes balisées et ouvertes)

MASSIF : Belledonne

Rédigé le mardi 28 avril 2026 à 16h

Estimation des risques pour le : MERCREDI 29 AVRIL

MANTEAU NEIGEUX DE PLUS EN PLUS HUMIDE SOUS 2600 / 2700M, RETOUR DE LA NEIGE A PLUS HAUTE ALTITUDE

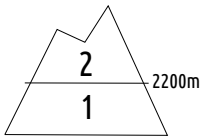

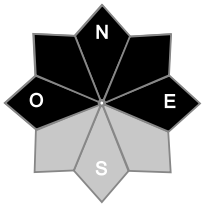

Au-dessus de 2200m indice de risque limité, plus bas indice faible.

Départs spontanés : Entre 2200 et 2700m, faible risque de départ d'une plaque sous la pluie.

Déclenchements provoqués : Peu probables. Coulées humides sous les skis en pente raide.

Indices de risque : 5 très fort - 4 fort - 3 marqué - 2 limité - 1 faible -- En noir : les pentes les plus dangereuses

Stabilité du manteau neigeux

Situation avalancheuse typique : neige humide

Mardi soir, des averses parfois orageuses donnent quelques cm de neige au-dessus de 2600 à 2700m. A plus basse altitude, la pluie accélère l'humidification du manteau neigeux.

Départs spontanés : Sous 2600 à 2700m l'humidification gagne en profondeur et pourrait faire partir de rares coulées humides de tailles petites à moyennes. Dans les versants Nord-Ouest à Nord-Est supérieurs à 2200m quelques couches fragiles "froides" peuvent subsister dans le manteau neigeux. Exceptionnellement, une grande avalanche avec une cassure linéaire ne peut être exclue dans le cas où l'humidification gagnerait ces couches fragiles enfouie. Au-dessus de 2600 / 2700m, les 7 à 15cm de neige récente sont stables. Eventuellement quelques départs en escargots sous les rochers.

Déclenchements provoqués : Peu probables, ou un risque limité de coulée ponctuelle sous les skis en terrain raide et bien humidifié. Au-dessus de 2600m, possibilité de faire partir des coulées ponctuelles dans les 7 à 15cm de neige récente bien humide.

Qualité de la neige

Qualification de l'enneigement : L'enneigement s'est bien réduit depuis début avril, il devient déficitaire sur le massif. Il est tout au mieux correct en Nord d'altitude.

Limites skiables : Vers 1600/1800m en Nord à 2000/2300m en versants ensoleillés.

Qualité de la neige mercredi : Pas de regel nocturne, ou très médiocre au-dessus de 2500 / 2600m. Neige gorgée d'eau sous 2600 / 2700m environ. Plus haut, 5 à 10cm de neige récente déjà très humide, collant aux skis. Mercredi après-midi sous les averses, 5 à 10cm de neige supplémentaires possibles au-dessus de 2700m.

Aperçu météo pour le mercredi 29 avril

nuit	matin	après-midi	soir

Temps encore assez nuageux en matinée. L'après-midi reprise de la convection, avec un risque d'averses de courtes durées mais temporairement soutenues, parfois orageuses.

	nuit	matin	après-midi	soir
Pluie-Neige	2 600 m		2 600 m	
Iso 0 °C	2 900 m	2 900 m	3 000 m	3 100 m
Vent 2000 m	↖ 15 km/h	↓ 10 km/h	↘ 15 km/h	↖ 10 km/h
Vent 3000 m	↗ 25 km/h	↑ 10 km/h	↗ 10 km/h	→ 10 km/h

Épaisseur de neige hors-piste

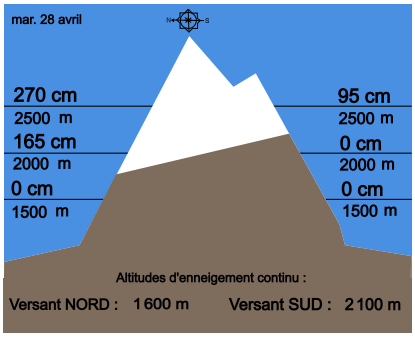

Précipitations à 1800 m

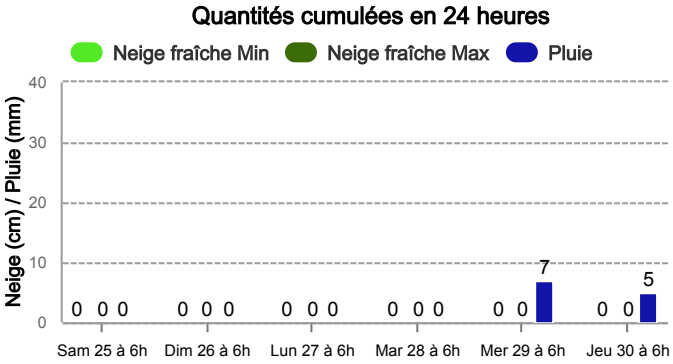

Tendance du jeudi 30 avril

Indice de risque limité

Jeudi on profitera de quelques éclaircies en matinées, puis de nouvelles averses (parfois orageuses) se développeront l'après-midi. Pas d'évolution du risque.

Pour consulter la vigilance en cours, veuillez vous rendre sur le site https://vigilance.meteofrance.fr/fr

Météo-France - 73 avenue de Paris, 94165 Saint-Mandé cedex - Contact : contact@meteo.fr

Rédigé par Météo-France avec la contribution des observateurs du réseau nivo-météorologiques. Partenariat : ANMSM (Maires de Stations de Montagne), DSF (Domaines Skiables de France), ADSP (Directeurs de Pistes et de la Sécurité des Stations de Sports d'Hiver) et autres acteurs de la montagne.

Bulletin neige & avalanches par téléphone au
0 892 68 10 20 Service 0,35 € / min + prix appel

RÉPUBLIQUE FRANÇAISE
Liberté Égalité Fraternité

METEO FRANCE
À VOS CÔTÉS, DANS UN CLIMAT QUI CHANGE

Bulletin d'estimation du risque d'avalanche

(valable en dehors des pistes balisées et ouvertes)

MASSIF : Belledonne

Rédigé le mardi 28 avril 2026 à 16h

Conditions nivo-météo des 7 derniers jours

	mer. 22/04				jeu. 23/04				ven. 24/04				sam. 25/04				dim. 26/04				lun. 27/04				mar. 28/04			
	03h	09h	15h	21h	03h	09h	15h	21h	03h	09h	15h	21h	03h	09h	15h	21h	03h	09h	15h	21h	03h	09h	15h	21h	03h	09h	15h	21h
Météo																												
Vent (km/h)	35	35	25	15	15	20	25	15	15	5	10	5	10	20	20	15	15	15	15	15	10	10	15	20	15	15	30	30
à 3000m																												
Vent (km/h)	10	15	20	10	10	15	15	10	10	5	15	10	10	15	15	10	10	10	10	10	5	5	10	10	10	15	20	15
à 2000m																												

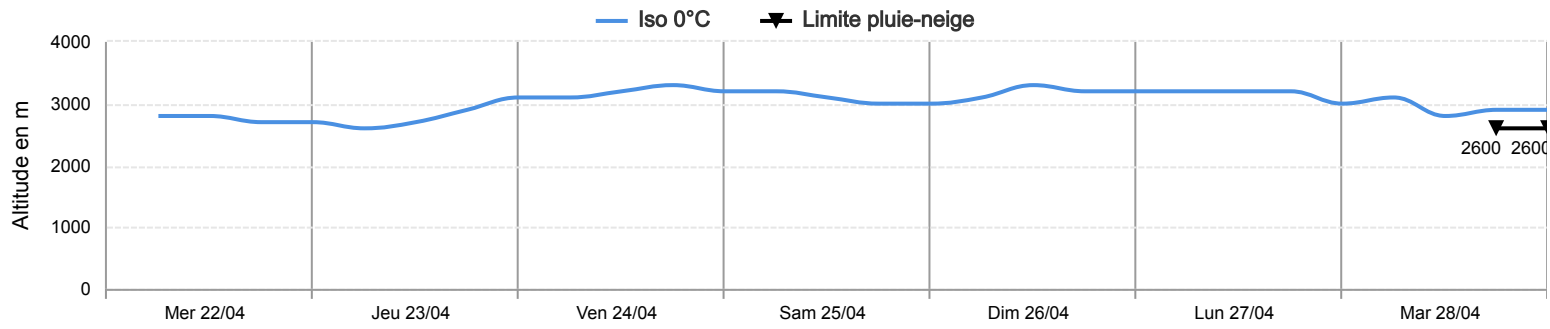

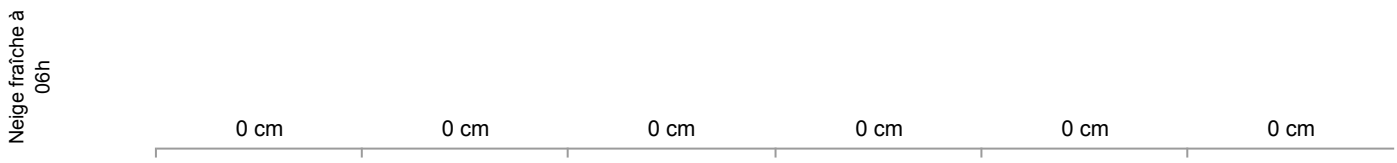

Risque d'avalanche	mer. 22/04	jeu. 23/04	ven. 24/04	sam. 25/04	dim. 26/04	lun. 27/04	mar. 28/04
	2	2	2	2	2	2	2

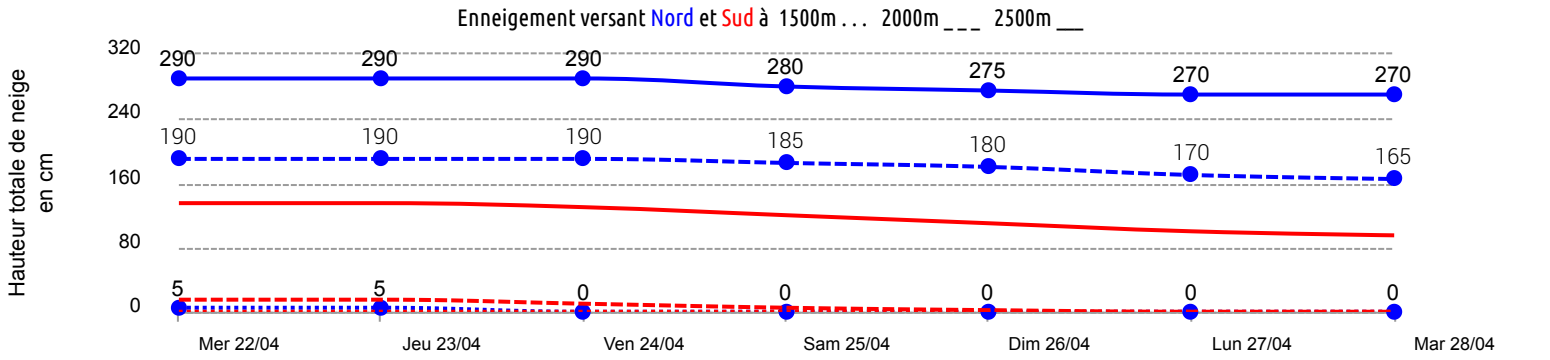

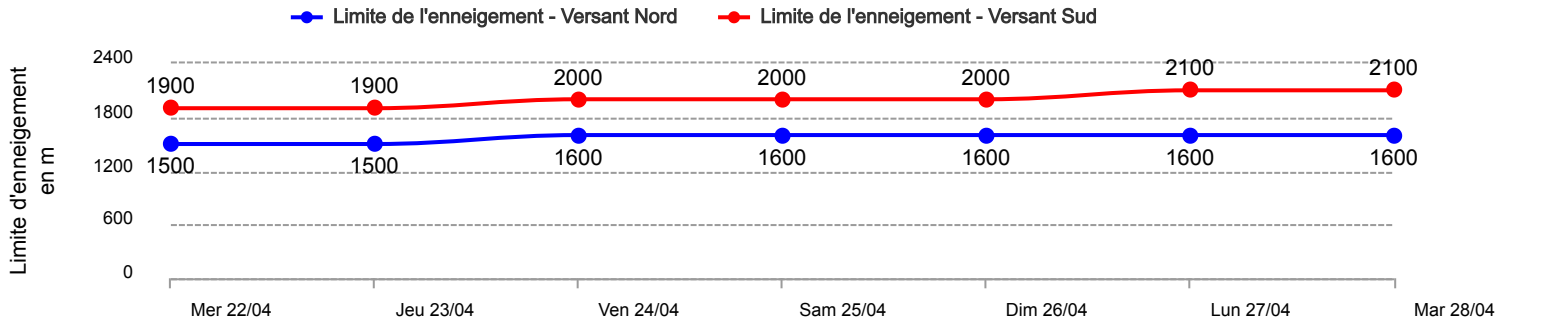

Pour consulter la vigilance en cours, veuillez vous rendre sur le site https://vigilance.meteofrance.fr/fr

Météo-France - 73 avenue de Paris, 94165 Saint-Mandé cedex - Contact : contact@meteo.fr

Bulletin neige & avalanches par téléphone au

0 892 68 10 20 Service 0,35 € / min + prix appel

Rédigé par Météo-France avec la contribution des observateurs du réseau nivo-météorologiques. Partenariat : ANMSM (Maires de Stations de Montagne), DSF (Domaines Skiables de France), ADSP (Directeurs de Pistes et de la Sécurité des Stations de Sports d'Hiver) et autres acteurs de la montagne.