Bulletin d'estimation du risque d'avalanche
(valable en dehors des pistes balisées et ouvertes)

MASSIF : Chablais

Rédigé le mardi 28 avril 2026 à 16h

Estimation des risques pour le : MERCREDI 29 AVRIL

AVALANCHE DE NEIGE HUMIDE PENDANT ET APRÈS LES AVERSES

2

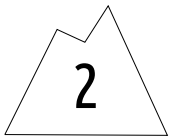

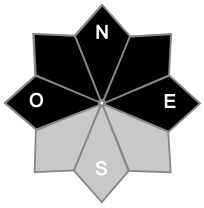

Indice de risque limité.

Départs spontanés : Avalanches de neige humide avec la pluie puis avec le réchauffement diurne.

Déclenchements provoqués : De la neige humide peut couler sous les skis.

Indices de risque : 5 très fort - 4 fort - 3 marqué - 2 limité - 1 faible -- En noir : les pentes les plus dangereuses

Stabilité du manteau neigeux

Situation avalancheuse typique : neige humide avalanches de fond

Départs spontanés :

* **Avalanches de neige humide** à toutes altitudes. Départs possibles pendant les chutes de pluie puis au fil du réchauffement diurne. Taille 1 (petite) à 2 (moyenne)

Facteur aggravant, **au-dessus de 2400 m en versants E/N/O : pendant et après les chutes de pluie, un départ en plaque est possible** si l'humification atteint une couche fragile enfouie dans le manteau neigeux. Cassure de 50/80 cm possibles. Taille 2 (moyenne).

* Quelques plaques de fond dans les pentes raides et lisses (pentes herbeuses, dalles rocheuses). Possibles à toute heure du jour et de la nuit. Taille 2 (moyenne).

Déclenchements provoqués :

* Déclenchements ponctuels de neige humide sous les pieds ou les skis. Facilement déclenchables. Causé par les précipitations pluvieuses puis par le réchauffement diurne. Taille 1 (petite) à 2 (moyenne).

Qualité de la neige

Enneigement :

Pour la saison, l'enneigement est déficitaire à toutes altitudes.
On peut chausser les skis au-dessus de 2000 m en sud et 1700 m en nord.

Qualité de la neige ce mercredi :

* En dessous de 2400 m, manteau neigeux humide en profondeur, voire neige de névé, avec un mauvais regel nocturne.
* Au-dessus de 2400 m : manteau neigeux printanier, humidifié en surface. Faible regel nocturne.

Aperçu météo pour le mercredi 29 avril

	nuit	matin	après-midi	soir

Belle éclaircies le matin, puis des averses s'installent l'après-midi. De 5°C à 9°C à 2000 m.

Pluie-Neige	2 500 m			
Iso 0 °C	2 700 m	2 900 m	3 000 m	3 000 m
Vent 2000 m	20 km/h	5 km/h	5 km/h	5 km/h
Vent 2500 m	30 km/h	10 km/h	5 km/h	5 km/h

Épaisseur de neige hors-piste

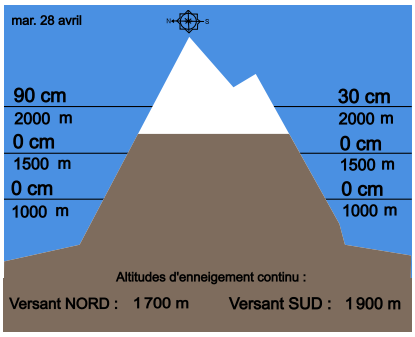

Précipitations à 1800 m

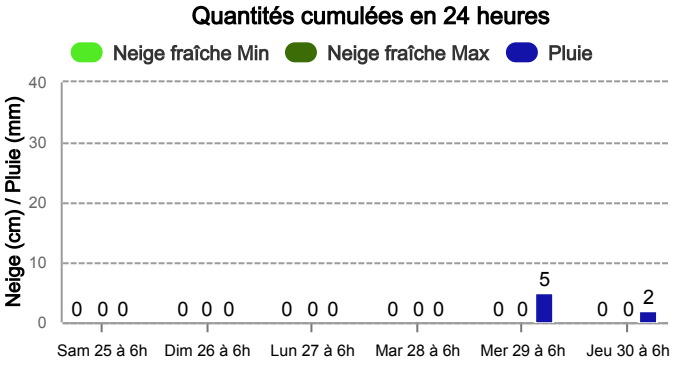

Tendance du jeudi 30 avril

2

Indice de risque limité

Départs de neige humide en journée. La journée est plus sèche et ensoleillée avec des cumulus qui gonflent dans les massifs.
Isotherme 0°C vers 3000 m.

Pour consulter la vigilance en cours, veuillez vous rendre sur le site https://vigilance.meteofrance.fr/fr

Météo-France - 73 avenue de Paris, 94165 Saint-Mandé cedex - Contact : contact@meteo.fr

Rédigé par Météo-France avec la contribution des observateurs du réseau nivo-météorologiques. Partenariat : ANMSM (Maires de Stations de Montagne), DSF (Domaines Skiables de France), ADSP (Directeurs de Pistes et de la Sécurité des Stations de Sports d'Hiver) et autres acteurs de la montagne.

Bulletin neige & avalanches par téléphone au 0 892 68 10 20 Service 0,35 € / min + prix appel

RÉPUBLIQUE FRANÇAISE
Liberté Égalité Fraternité

METEO FRANCE
À VOS CÔTÉS, DANS UN CLIMAT QUI CHANGE

Bulletin d'estimation du risque d'avalanche
(valable en dehors des pistes balisées et ouvertes)
MASSIF : Chablais

Rédigé le mardi 28 avril 2026 à 16h

Conditions nivo-météo des 7 derniers jours

	mer. 22/04				jeu. 23/04				ven. 24/04				sam. 25/04				dim. 26/04				lun. 27/04				mar. 28/04			
	03h	09h	15h	21h	03h	09h	15h	21h	03h	09h	15h	21h	03h	09h	15h	21h	03h	09h	15h	21h	03h	09h	15h	21h	03h	09h	15h	21h
Météo																												
Vent (km/h)	20	20	10	10	10	20	20	20	10	5	10	10	10	20	15	5	5	10	5	10	20	5	20	20	20	15	15	25
à 2500m																												
Vent (km/h)	15	10	5	5	5	15	10	10	5	5	5	5	10	15	15	5	5	10	5	5	10	5	10	10	10	10	10	15
à 2000m																												

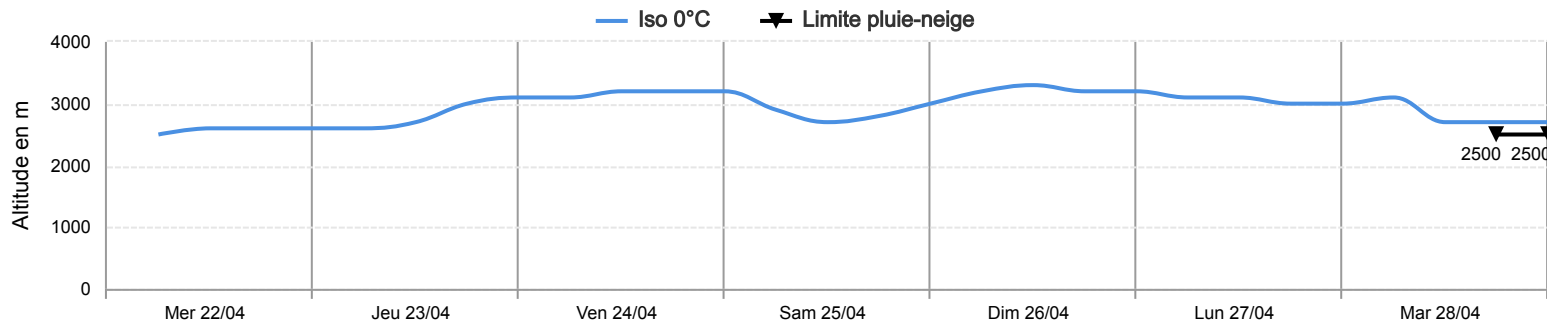

Neige fraîche à 06h

mer. 22/04	jeu. 23/04	ven. 24/04	sam. 25/04	dim. 26/04	lun. 27/04
0 cm	0 cm	0 cm	0 cm	0 cm	0 cm

Risque d'avalanche	mer. 22/04	jeu. 23/04	ven. 24/04	sam. 25/04	dim. 26/04	lun. 27/04	mar. 28/04
	2	2	2	2	2	2	2

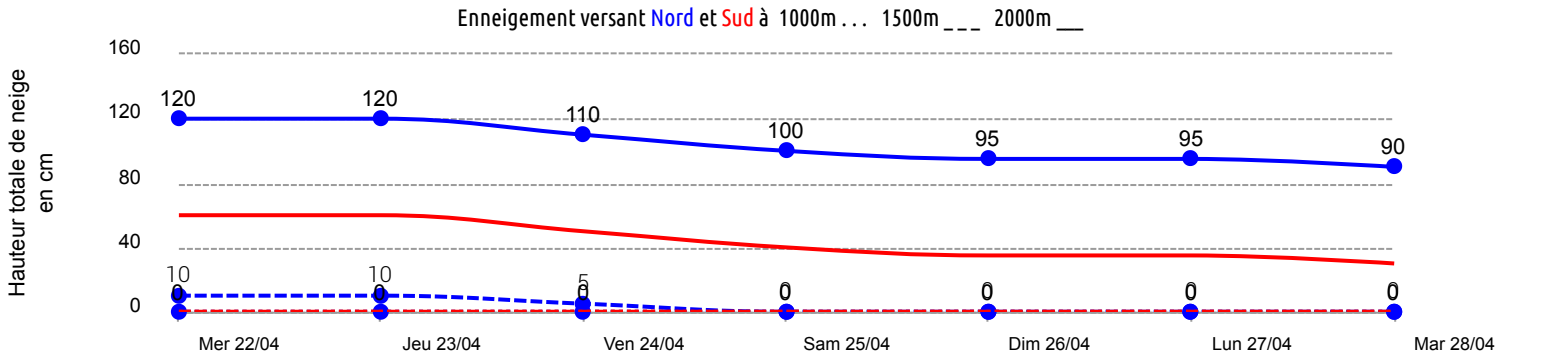

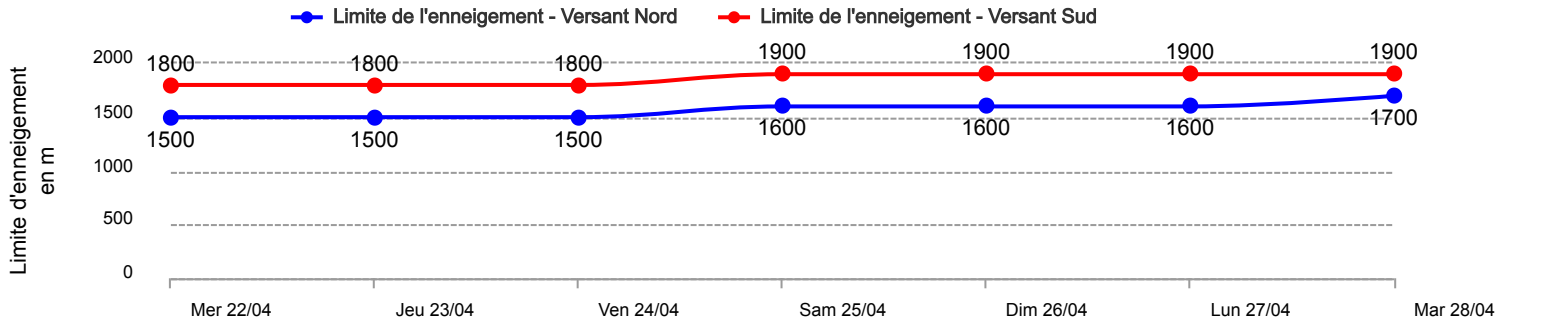

Pour consulter la vigilance en cours, veuillez vous rendre sur le site https://vigilance.meteofrance.fr/fr

Météo-France - 73 avenue de Paris, 94165 Saint-Mandé cedex - Contact : contact@meteo.fr

Bulletin neige & avalanches par téléphone au **0 892 68 10 20** Service 0,35 € / min + prix appel

Rédigé par Météo-France avec la contribution des observateurs du réseau nivo-météorologiques. Partenariat : ANMSM (Maires de Stations de Montagne), DSF (Domaines Skiables de France), ADSP (Directeurs de Pistes et de la Sécurité des Stations de Sports d'Hiver) et autres acteurs de la montagne.