Bulletin d'estimation du risque d'avalanche
(valable en dehors des pistes balisées et ouvertes)

MASSIF : Champsaur

Rédigé le mardi 28 avril 2026 à 16h

Estimation des risques pour le : MERCREDI 29 AVRIL

MANTEAU NEIGEUX PRINTANIER. UN PEU D'ACTIVITÉ NATURELLE EN NEIGE HUMIDE

2

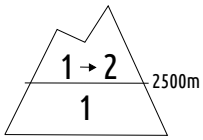

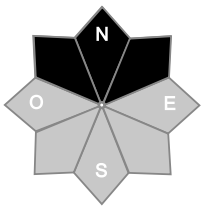

Au-dessus de 2500m indice de risque faible évoluant en limité, plus bas indice faible.

Départs spontanés : en neige humide. Rares, mais possiblement volumineux en ubacs d'altitude.

Déclenchements provoqués : en neige humide sous les skis

Indices de risque : 5 très fort - 4 fort - 3 marqué - 2 limité - 1 faible -- En noir : les pentes les plus dangereuses

Stabilité du manteau neigeux

Situation avalancheuse typique : neige humide

Départs spontanés : après un regel nocturne correct, l'activité en neige humide reprend en cours de journée sous l'effet du soleil et de la douceur. Avalanches en neige humide restant rares mais pouvant être volumineuses en cas de départ linéaire. Taille moyenne, grande non exclue, dans les pentes nord-ouest / nord / nord-est au-dessus de 2500 m environ, pouvant emporter la totalité du manteau neigeux. Plus bas, et dans les pentes sud jusqu'à haute altitude, le manteau neigeux est désormais dense et bien stabilisé.

Déclenchements provoqués : un skieur coupant une pente raide tardivement peut initier un départ de neige humide sous les skis de taille limitée. Dans les ubacs au dessus de 2900/3000 m, éventuellement des structures de plaques superficielles dans la neige fraîche tombée sous les averses de mardi.

Qualité de la neige

Enneigement désormais déficitaire, notamment en adrets.
Hauteurs de neige observées : 46 cm à la nivôse d'Orcières à 2300 m.

Limite d'enneigement skiable : très localement vers 1900 m en fond de vallée en cœur de massif, 2300/2400 m en adrets.

État de la neige de surface : manteau neigeux printanier, voire de névé en toute orientation sous 2500 m environ et en adrets d'altitude. Bon regel nocturne, puis reprise de l'humidification en journée. Quelques cm de fraîche sont possibles tombés sous une averse de neige de mardi sur les glaciers ou en combes nord de haute altitude, au delà de 2800/3000 m.

Aperçu météo pour le mercredi 29 avril

	nuit	matin	après-midi	soir

Temps sec et doux. 12° à 2000 m et 5° à 3000 m.

Pluie-Neige				
Iso 0 °C	2 900 m	3 000 m	3 100 m	3 100 m
Vent 2000 m	← 10 km/h	↑ 10 km/h	↗ 15 km/h	← 10 km/h
Vent 3000 m	→ 10 km/h	↑ 10 km/h	↗ 15 km/h	→ 10 km/h

Épaisseur de neige hors-piste

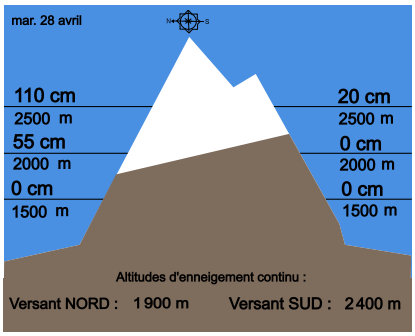

Précipitations à 1800 m

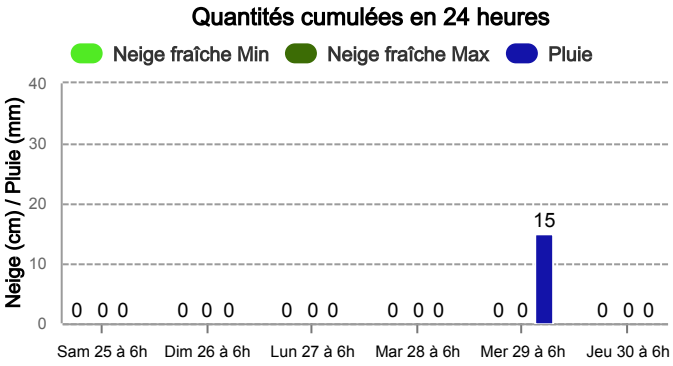

Tendance du jeudi 30 avril

2

Indice de risque limité

Pas d'évolution de la situation nivologique. Risque limité en neige humide ne concernant que les versants nord de haute altitude. Côté météo, risque d'averses l'après-midi.

Pour consulter la vigilance en cours, veuillez vous rendre sur le site https://vigilance.meteofrance.fr/fr

Météo-France - 73 avenue de Paris, 94165 Saint-Mandé cedex - Contact : contact@meteo.fr

Rédigé par Météo-France avec la contribution des observateurs du réseau nivo-météorologiques. Partenariat : ANMSM (Maires de Stations de Montagne), DSF (Domaines Skiables de France), ADSP (Directeurs de Pistes et de la Sécurité des Stations de Sports d'Hiver) et autres acteurs de la montagne.

Bulletin neige & avalanches par téléphone au
0 892 68 10 20 Service 0,35 € / min + prix appel

RÉPUBLIQUE FRANÇAISE
Liberté Égalité Fraternité

METEO FRANCE
À VOS CÔTÉS, DANS UN CLIMAT QUI CHANGE

Bulletin d'estimation du risque d'avalanche

(valable en dehors des pistes balisées et ouvertes)

MASSIF : Champsaur

Rédigé le mardi 28 avril 2026 à 16h

Conditions nivo-météo des 7 derniers jours

	mer. 22/04				jeu. 23/04				ven. 24/04				sam. 25/04				dim. 26/04				lun. 27/04				mar. 28/04			
	03h	09h	15h	21h	03h	09h	15h	21h	03h	09h	15h	21h	03h	09h	15h	21h	03h	09h	15h	21h	03h	09h	15h	21h	03h	09h	15h	21h
Météo																												
Vent (km/h)	20	25	25	15	20	15	15	15	15	10	10	10	10	10	15	10	10	10	10	10	10	10	15	15	15	20	30	15
à 3000m																												
Vent (km/h)	15	15	25	10	5	10	15	10	10	5	15	10	5	5	20	5	5	5	15	10	5	10	15	10	10	15	25	10
à 2000m																												

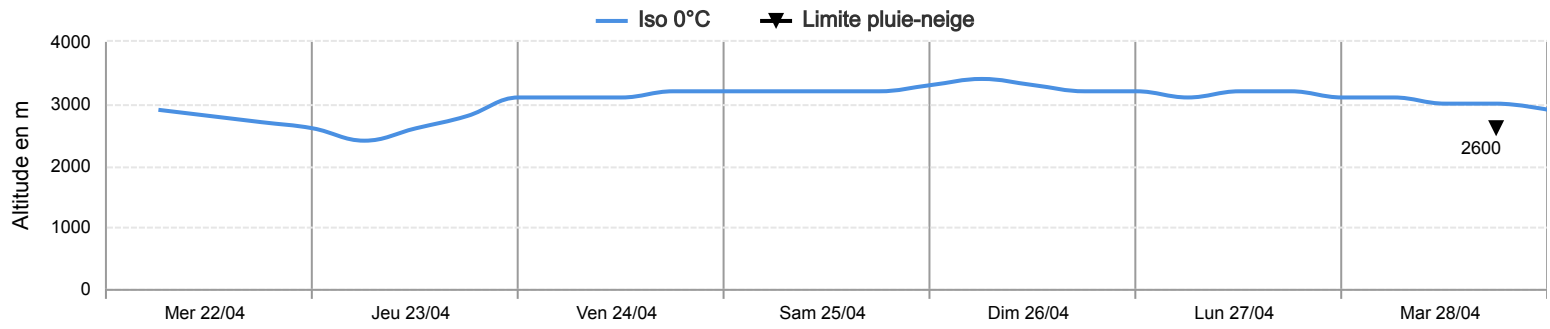

Neige fraîche à 06h

mer. 22/04	jeu. 23/04	ven. 24/04	sam. 25/04	dim. 26/04	lun. 27/04	mar. 28/04
0 cm	0 cm	0 cm	0 cm	0 cm	0 cm	

Risque d'avalanche	mer. 22/04	jeu. 23/04	ven. 24/04	sam. 25/04	dim. 26/04	lun. 27/04	mar. 28/04
	1	2	2	2	2	2	2

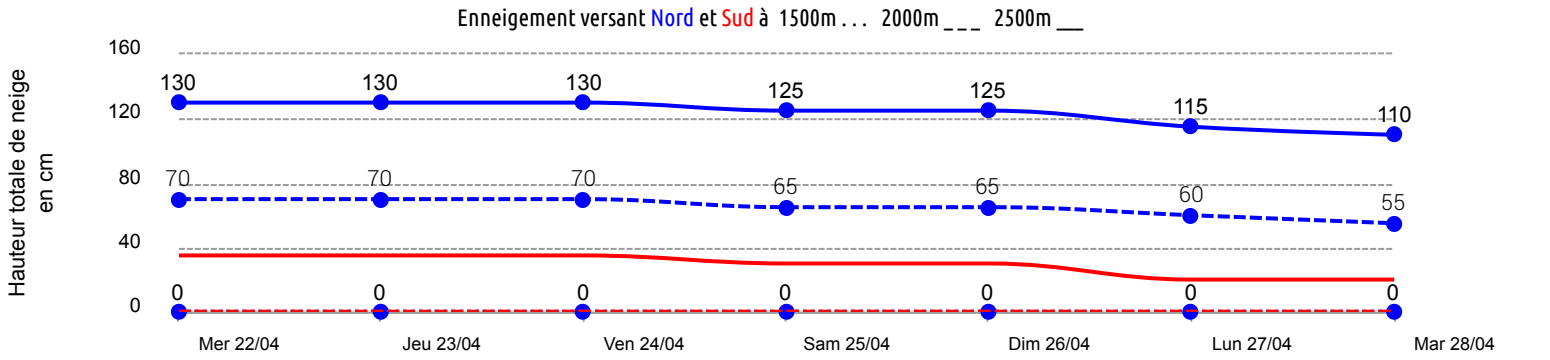

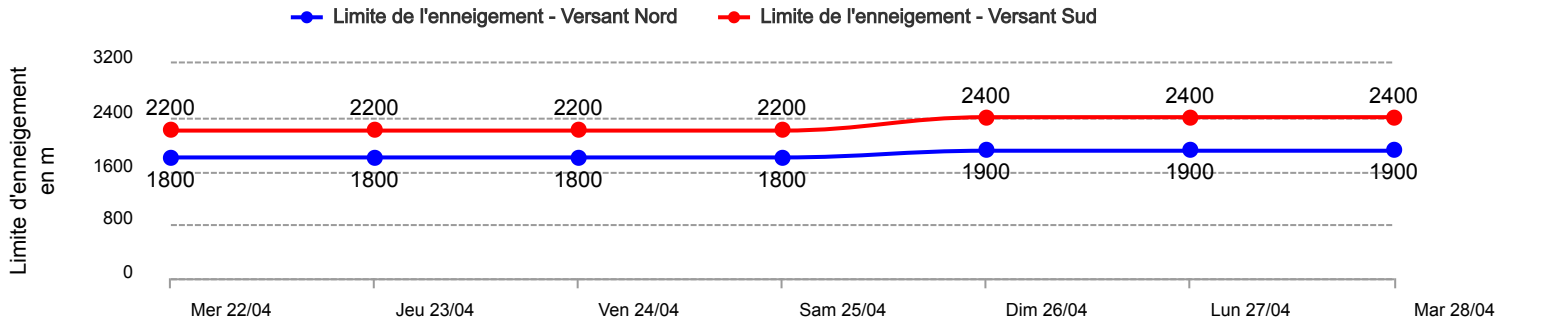

Pour consulter la vigilance en cours, veuillez vous rendre sur le site https://vigilance.meteofrance.fr/fr

Météo-France - 73 avenue de Paris, 94165 Saint-Mandé cedex - Contact : contact@meteo.fr

Rédigé par Météo-France avec la contribution des observateurs du réseau nivo-météorologiques. Partenariat : ANMSM (Maires de Stations de Montagne), DSF (Domaines Skiables de France), ADSP (Directeurs de Pistes et de la Sécurité des Stations de Sports d'Hiver) et autres acteurs de la montagne.

Bulletin neige & avalanches par téléphone au

0 892 68 10 20 Service 0,35 € / min + prix appel