Bulletin d'estimation du risque d'avalanche
(valable en dehors des pistes balisées et ouvertes)

MASSIF : Chartreuse

Rédigé le mardi 28 avril 2026 à 16h

Estimation des risques pour le : MERCREDI 29 AVRIL

MANTEAU NEIGEUX DE FIN DE SAISON, STABLE

1

1

N O E S

Indice de risque faible.

Départs spontanés : Peu probables.

Déclenchements provoqués : Peu probables.

Indices de risque : 5 très fort - 4 fort - 3 marqué - 2 limité - 1 faible -- En noir : les pentes les plus dangereuses

Stabilité du manteau neigeux

Situation avalancheuse typique : pas de situation prédominante

De moins en moins de neige sur le massif où l'on se rapproche de la fin de saison.
Départs spontanés : Peu probables, ou très rare coulée humide en pente bien raide sous la pluie.
Déclenchements provoqués : Peu probables, ou de manière très rare sous les skis en neige humide.

Qualité de la neige

Qualification de l'enneigement : L'enneigement s'est fortement réduit depuis début avril et devient déficitaire pour la saison. Il ne reste souvent que des névés, ou quelques pentes skiables en Nord d'altitude.
Limites skiables : Vers 1700m en Nord bien abrité. Les pentes Sud ne sont parfois plus du tout enneigées.

Qualité de la neige mercredi : Pas de regel nocturne. Manteau neigeux entièrement humide suite à la pluie de mardi.

Aperçu météo pour le mercredi 29 avril

Temps encore assez nuageux en matinée. L'après-midi reprise de la convection, avec un risque d'averses de courtes durées mais temporairement soutenues, parfois orageuses.

	nuit	matin	après-midi	soir
Pluie-Neige	2 600 m		2 500 m	
Iso 0 °C	2 900 m	2 900 m	3 000 m	3 000 m
Vent 1500 m	15 km/h	15 km/h	20 km/h	10 km/h
Vent 2000 m	30 km/h	10 km/h	10 km/h	5 km/h

Épaisseur de neige hors-piste

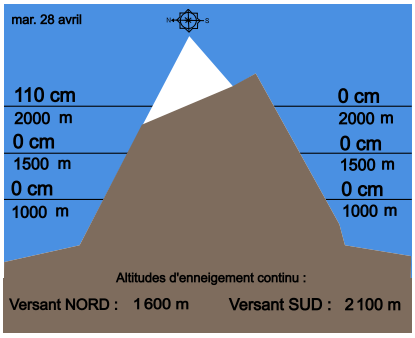

Précipitations à 1800 m

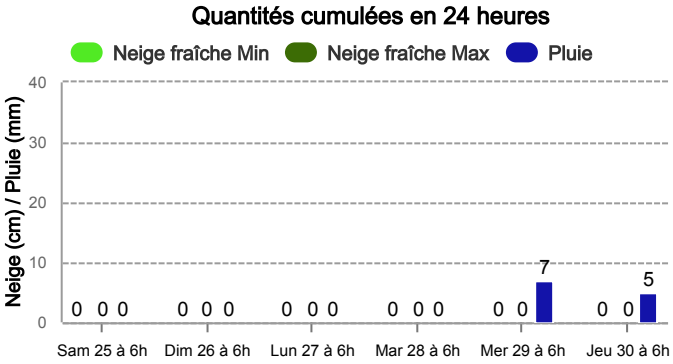

Tendance du jeudi 30 avril

1

Indice de risque faible

Jeudi on profitera de quelques éclaircies en matinées, puis de nouvelles averses orageuses se développeront l'après-midi. Le risque n'évolue pas, avec un manteau irrégulier, dense et stable.

Pour consulter la vigilance en cours, veuillez vous rendre sur le site https://vigilance.meteofrance.fr/fr

Météo-France - 73 avenue de Paris, 94165 Saint-Mandé cedex - Contact : contact@meteo.fr

Rédigé par Météo-France avec la contribution des observateurs du réseau nivo-météorologiques. Partenariat : ANMSM (Maires de Stations de Montagne), DSF (Domaines Skiables de France), ADSP (Directeurs de Pistes et de la Sécurité des Stations de Sports d'Hiver) et autres acteurs de la montagne.

Bulletin neige & avalanches par téléphone au 0 892 68 10 20 Service 0,35 € / min + prix appel

RÉPUBLIQUE FRANÇAISE
Liberté Égalité Fraternité

METEO FRANCE
À VOS CÔTÉS, DANS UN CLIMAT QUI CHANGE

Bulletin d'estimation du risque d'avalanche
(valable en dehors des pistes balisées et ouvertes)
MASSIF : Chartreuse

Rédigé le mardi 28 avril 2026 à 16h

Conditions nivo-météo des 7 derniers jours

	mer. 22/04				jeu. 23/04				ven. 24/04				sam. 25/04				dim. 26/04				lun. 27/04				mar. 28/04			
	03h	09h	15h	21h	03h	09h	15h	21h	03h	09h	15h	21h	03h	09h	15h	21h	03h	09h	15h	21h	03h	09h	15h	21h	03h	09h	15h	21h
Météo																												
Vent (km/h)	10	15	10	5	5	15	10	15	10	5	5	10	15	15	20	10	15	20	15	10	10	10	15	10	10	20	30	35
à 2000m																												
Vent (km/h)	10	15	20	10	10	15	15	10	10	10	15	10	10	15	20	10	10	15	10	5	5	5	10	5	10	15	20	15
à 1500m																												

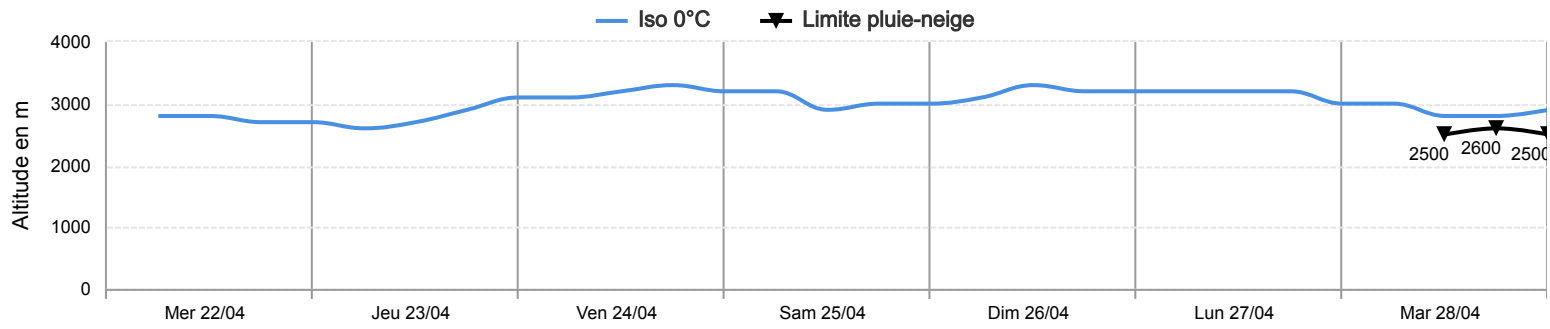

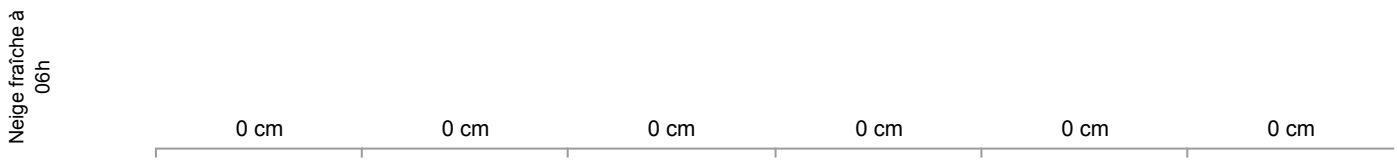

Risque d'avalanche	mer. 22/04	jeu. 23/04	ven. 24/04	sam. 25/04	dim. 26/04	lun. 27/04	mar. 28/04
	1	1	1	1	1	1	1

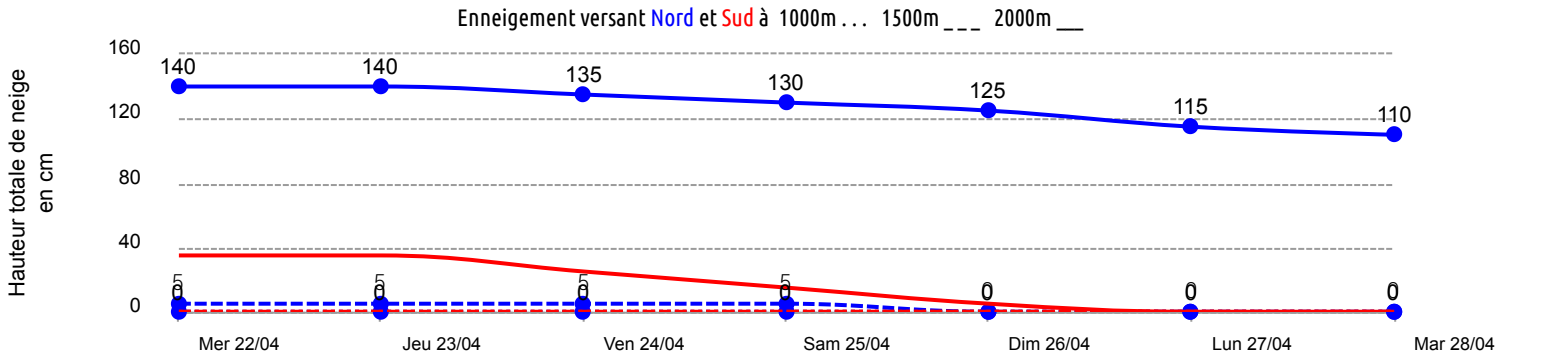

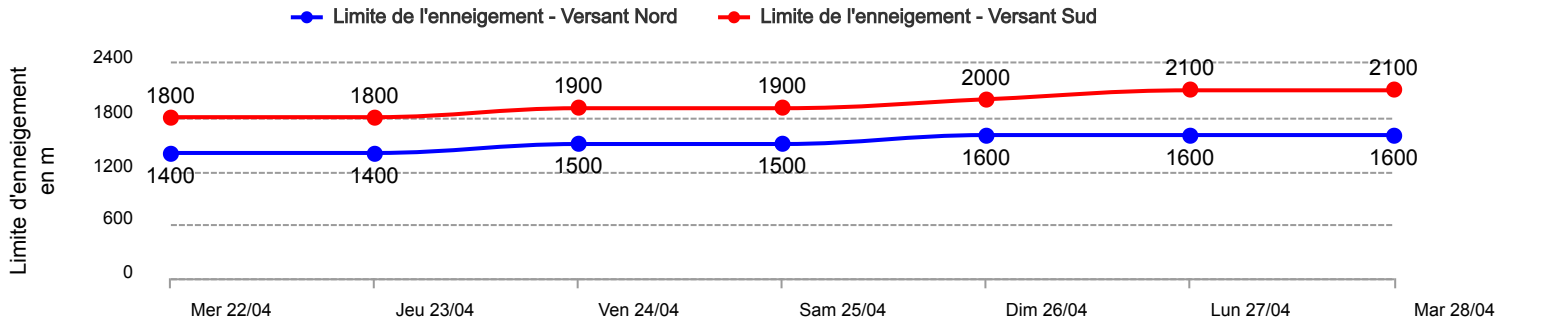

Pour consulter la vigilance en cours, veuillez vous rendre sur le site https://vigilance.meteofrance.fr/fr

Météo-France - 73 avenue de Paris, 94165 Saint-Mandé cedex - Contact : contact@meteo.fr

Bulletin neige & avalanches par téléphone au **0 892 68 10 20** Service 0,35 € / min + prix appel

Rédigé par Météo-France avec la contribution des observateurs du réseau nivo-météorologiques. Partenariat : ANMSM (Maires de Stations de Montagne), DSF (Domaines Skiables de France), ADSP (Directeurs de Pistes et de la Sécurité des Stations de Sports d'Hiver) et autres acteurs de la montagne.