RÉPUBLIQUE FRANÇAISE
*Liberté Égalité Fraternité*

METEO FRANCE
À VOS CÔTÉS, DANS UN CLIMAT QUI CHANGE

# Bulletin d'estimation du risque d'avalanche
## (valable en dehors des pistes balisées et ouvertes)
# MASSIF : Embrunais Parpaillon

Rédigé le mardi 28 avril 2026 à 16h

## Estimation des risques pour le : MERCREDI 29 AVRIL

**MANTEAU NEIGEUX PRINTANIER - DENSE ET STABLE**

2

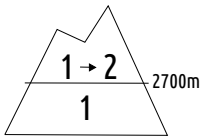


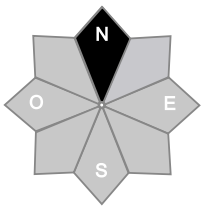


Au-dessus de 2700m indice de risque faible évoluant en limité, plus bas indice faible.

**Départs spontanés :** peu probables

**Déclenchements provoqués :** en neige humide sous les skis

Indices de risque : 5 très fort - 4 fort - 3 marqué - 2 limité - 1 faible -- En noir : les pentes les plus dangereuses

## Stabilité du manteau neigeux

**Situation avalancheuse typique :** neige humide

**Départs spontanés** : peu probables au petit matin après un regel nocturne correct, puis petite activité en neige humide en journée sous l'effet du soleil et de la douceur. Avalanches généralement superficielles de taille 1. Une rare taille 2 reste possible dans les pentes nord au dessus de 2500/2700 m.

**Déclenchements provoqués** : un skieur coupant une pente raide tardivement peut initier un départ de neige humide sous les skis. Taille limitée et seulement en ubacs raides vers les plus hauts sommets.

## Qualité de la neige

**Enneigement** déficitaire pour la période, notamment en adrets.
Hauteurs de neige observées vers 2500 m : 48 cm à la nivôse du Parpaillon.

**Limite d'enneigement skiable** : au plus bas à 2000 m en ubacs bien protégés ou sur pistes forestières

**État de la neige de surface** : manteau neigeux printanier, voire de névé en toute orientation sous 2500 m environ et en adrets d'altitude. Regel nocturne, puis reprise de l'humidification en journée.

## Aperçu météo pour le mercredi 29 avril

| | nuit | matin | après-midi | soir |
|---|---|---|---|---|
| Temps sec et doux. 12° à 2000 m et 5° à 3000 m. | | | | |
| **Pluie-Neige** | | | | |
| **Iso 0 °C** | 2 900 m | 3 000 m | 3 000 m | 3 100 m |
| **Vent 2000 m** | ← 10 km/h | ↖ 15 km/h | ↗ 20 km/h | ↓ 10 km/h |
| **Vent 3000 m** | → 10 km/h | ↗ 10 km/h | ↗ 15 km/h | → 15 km/h |

## Épaisseur de neige hors-piste

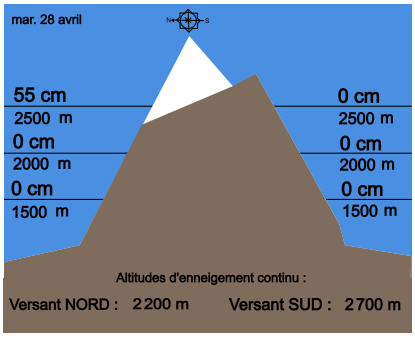


## Précipitations à 1800 m

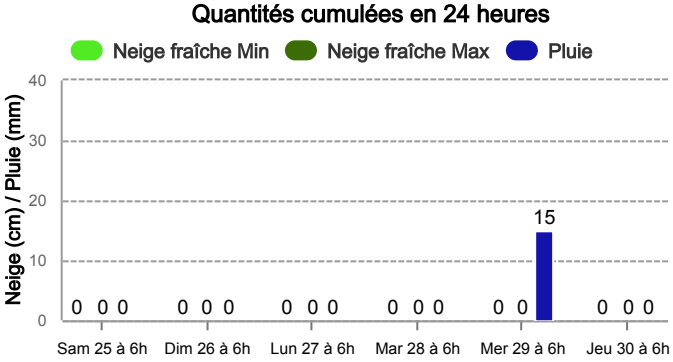


## Tendance du jeudi 30 avril

1

**Indice de risque faible**

Risque devenant faible en neige humide ne concernant que les versants nord de haute altitude. Côté météo, risque d'averses l'après-midi.

Pour consulter la vigilance en cours, veuillez vous rendre sur le site https://vigilance.meteofrance.fr/fr

Météo-France - 73 avenue de Paris, 94165 Saint-Mandé cedex - Contact : contact@meteo.fr

Rédigé par Météo-France avec la contribution des observateurs du réseau nivo-météorologiques. Partenariat : ANMSM (Maires de Stations de Montagne), DSF (Domaines Skiables de France), ADSP (Directeurs de Pistes et de la Sécurité des Stations de Sports d'Hiver) et autres acteurs de la montagne.

Bulletin neige & avalanches par téléphone au
0 892 68 10 20 Service 0,35 € / min + prix appel

RÉPUBLIQUE FRANÇAISE
*Liberté Égalité Fraternité*

METEO FRANCE
À VOS CÔTÉS, DANS UN CLIMAT QUI CHANGE

# Bulletin d'estimation du risque d'avalanche
## (valable en dehors des pistes balisées et ouvertes)
# MASSIF : Embrunais Parpaillon

Rédigé le mardi 28 avril 2026 à 16h

## Conditions nivo-météo des 7 derniers jours

| | mer. 22/04 | | | | jeu. 23/04 | | | | ven. 24/04 | | | | sam. 25/04 | | | | dim. 26/04 | | | | lun. 27/04 | | | | mar. 28/04 | | | |
|---|---|---|---|---|---|---|---|---|---|---|---|---|---|---|---|---|---|---|---|---|---|---|---|---|---|---|---|---|
| | 03h | 09h | 15h | 21h | 03h | 09h | 15h | 21h | 03h | 09h | 15h | 21h | 03h | 09h | 15h | 21h | 03h | 09h | 15h | 21h | 03h | 09h | 15h | 21h | 03h | 09h | 15h | 21h |
| Météo | | | | | | | | | | | | | | | | | | | | | | | | | | | | |
| Vent (km/h) | 40 | 40 | 25 | 15 | 20 | 20 | 15 | 25 | 20 | 10 | 5 | 5 | 10 | 15 | 10 | 10 | 10 | 5 | 15 | 5 | 10 | 10 | 15 | 15 | 15 | 20 | 30 | 15 |
| à 3000m | | | | | | | | | | | | | | | | | | | | | | | | | | | | |
| Vent (km/h) | 10 | 20 | 15 | 10 | 10 | 15 | 20 | 10 | 10 | 10 | 20 | 10 | 5 | 10 | 25 | 10 | 10 | 10 | 20 | 10 | 5 | 10 | 15 | 10 | 10 | 15 | 25 | 10 |
| à 2000m | | | | | | | | | | | | | | | | | | | | | | | | | | | | |

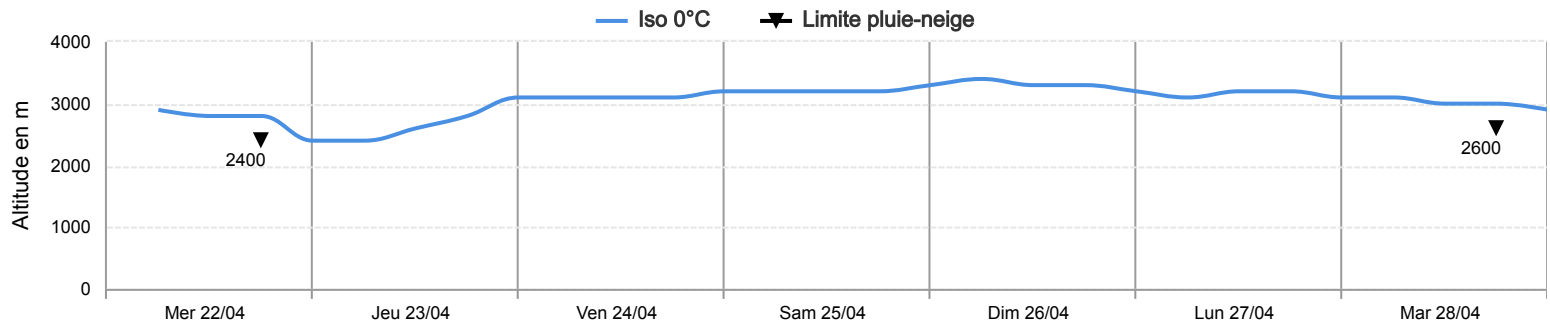


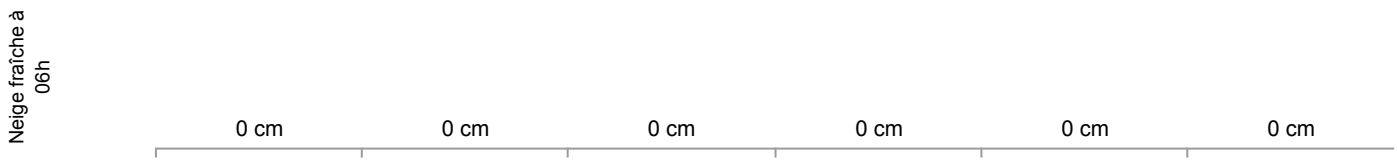


| Risque d'avalanche | mer. 22/04 | jeu. 23/04 | ven. 24/04 | sam. 25/04 | dim. 26/04 | lun. 27/04 | mar. 28/04 |
|---|---|---|---|---|---|---|---|
| | 1 | 2 | 2 | 2 | 2 | 2 | 2 |

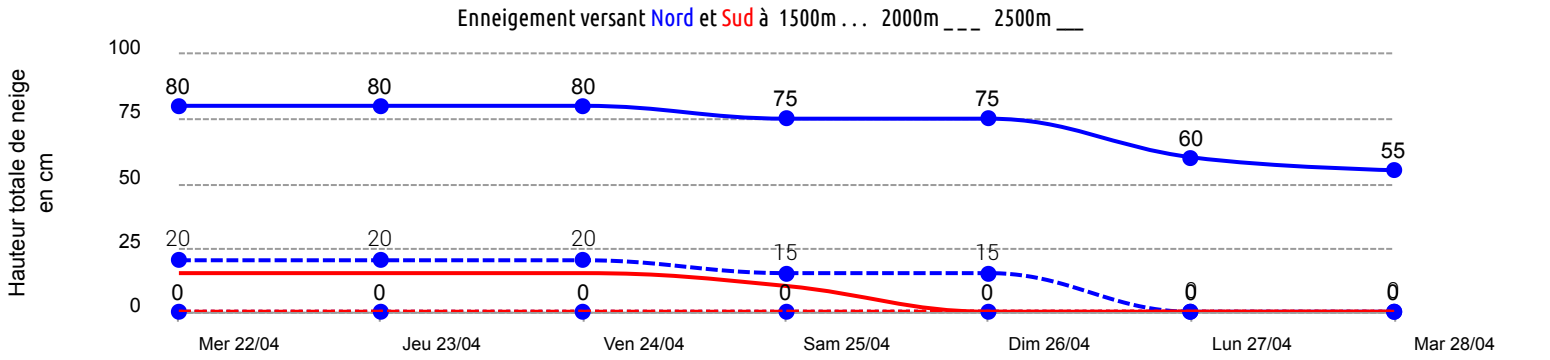


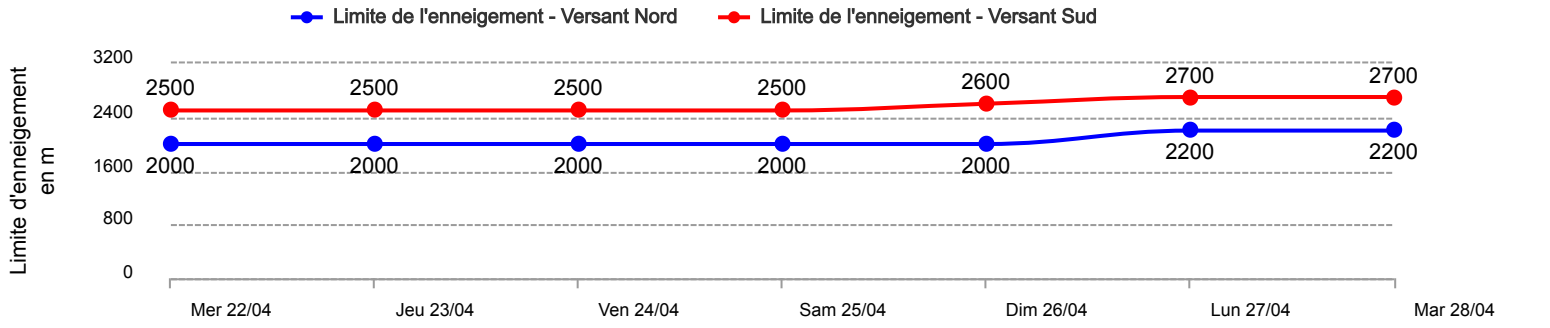


Pour consulter la vigilance en cours, veuillez vous rendre sur le site https://vigilance.meteofrance.fr/fr


Météo-France - 73 avenue de Paris, 94165 Saint-Mandé cedex - Contact : contact@meteo.fr


Bulletin neige & avalanches par téléphone au **0 892 68 10 20** Service 0,35 € / min + prix appel


Rédigé par Météo-France avec la contribution des observateurs du réseau nivo-météorologiques. Partenariat : ANMSM (Maires de Stations de Montagne), DSF (Domaines Skiables de France), ADSP (Directeurs de Pistes et de la Sécurité des Stations de Sports d'Hiver) et autres acteurs de la montagne.