RÉPUBLIQUE FRANÇAISE
*Liberté Égalité Fraternité*

METEO FRANCE
À VOS CÔTÉS, DANS UN CLIMAT QUI CHANGE

# Bulletin d'estimation du risque d'avalanche
## (valable en dehors des pistes balisées et ouvertes)

# MASSIF : Mercantour

Rédigé le mardi 28 avril 2026 à 16h

## Estimation des risques pour le : MERCREDI 29 AVRIL

**MANTEAU NEIGEUX PRINTANIER DE FIN DE SAISON BIEN STABLE**

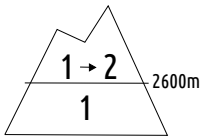


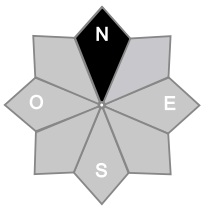


Au-dessus de 2600m indice de risque faible évoluant en limité, plus bas indice faible.

**Départs spontanés :** seulement en ubacs raides de haute altitude

**Déclenchements provoqués :** seulement en ubacs raides de haute altitude

Indices de risque : 5 très fort - 4 fort - 3 marqué - 2 limité - 1 faible -- En noir : les pentes les plus dangereuses

## Stabilité du manteau neigeux

**Situation avalancheuse typique :** neige humide

**Déclenchements provoqués :** le manteau neigeux est très faible pour une fin avril, et très stable. Les instabilités ne sont possibles que dans de rares pentes raides plein nord de haute altitude, au-dessus de 2600/2700 m, où le manteau neigeux n'est pas totalement humidifié jusqu'au sol. Un skieur évoluant en fin de journée peut alors initier un départ de neige humide sur toute l'épaisseur du manteau neigeux, générant une avalanche de taille moyenne (taille 2). Dans les autres orientations, le manteau neigeux est très stable et le danger négligeable.

**Départs spontanés :** très rares et seulement possibles en versants plein nord de haute altitude. Taille petite à moyenne (taille 1 à 2).

## Qualité de la neige

**Enneigement très faible** pour la période, après plus d'un mois sans précipitations notables et avec un isotherme 0 degré souvent à plus de 3000 m, l'enneigement est digne d'une mi mai. A la nivôse de Millefonts, on ne mesure plus que 64 cm de neige.

**Enneigement skiable** à partir de 2000/2100 m en ubacs, avec beaucoup de relief en surface en raison de l'intense fonte jusqu'à 2500/2600 m environ

**État de la neige en surface** : manteau neigeux sous forme de névé qui continue de fondre rapidement. Les pentes nord de haute altitude (> 2600 m) ne sont pas encore totalement transformées. Faible regel nocturne, puis reprise rapide de l'humidification et de la fonte en cours de journée dans toutes les expositions.

## Aperçu météo pour le mercredi 29 avril

| nuit | matin | après-midi | soir |
|---|---|---|---|

Plutôt ensoleillé le matin. Cumulus et quelques averses l'après-midi sur le relief.

| | | | | |
|---|---|---|---|---|
| **Pluie-Neige** | 2 800 m | | | |
| **Iso 0 °C** | 3 000 m | 2 900 m | 3 000 m | 3 100 m |
| **Vent 2000 m** | ↙ 10 km/h | ↙ 20 km/h | ↑ 20 km/h | ↓ 15 km/h |
| **Vent 3000 m** | ↑ 20 km/h | ← 15 km/h | ↑ 20 km/h | → 15 km/h |

## Épaisseur de neige hors-piste

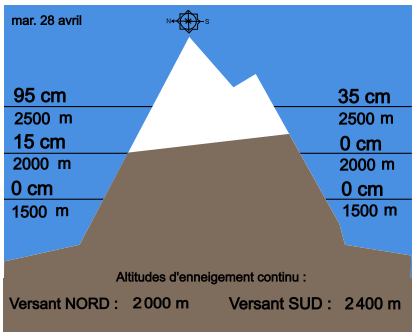


## Précipitations à 1800 m

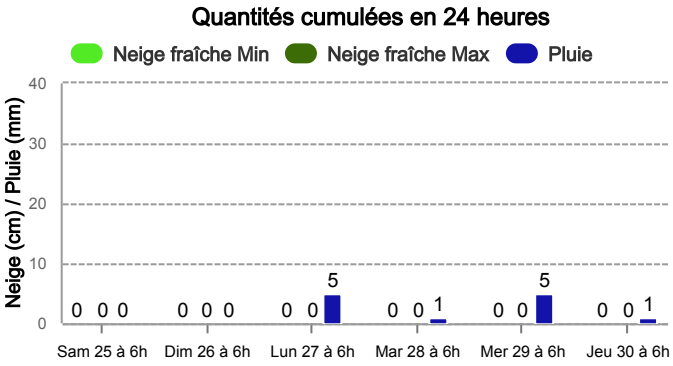


## Tendance du jeudi 30 avril

**Indice de risque faible**

Peu d'évolution ou tendance à la baisse. Manteau neigeux bien stabilié. Risque faible d'une avalanche de neige humide en pente nord de haute altitude.

Pour consulter la vigilance en cours, veuillez vous rendre sur le site https://vigilance.meteofrance.fr/fr

Météo-France - 73 avenue de Paris, 94165 Saint-Mandé cedex - Contact : contact@meteo.fr

Rédigé par Météo-France avec la contribution des observateurs du réseau nivo-météorologiques. Partenariat : ANMSM (Maires de Stations de Montagne), DSF (Domaines Skiables de France), ADSP (Directeurs de Pistes et de la Sécurité des Stations de Sports d'Hiver) et autres acteurs de la montagne.

Bulletin neige & avalanches par téléphone au
**0 892 68 10 20** Service 0,35 € / min + prix appel

RÉPUBLIQUE FRANÇAISE
*Liberté Égalité Fraternité*

METEO FRANCE
À VOS CÔTÉS, DANS UN CLIMAT QUI CHANGE

# Bulletin d'estimation du risque d'avalanche
## (valable en dehors des pistes balisées et ouvertes)

# MASSIF : Mercantour

Rédigé le mardi 28 avril 2026 à 16h

## Conditions nivo-météo des 7 derniers jours

| | mer. 22/04 | | | | jeu. 23/04 | | | | ven. 24/04 | | | | sam. 25/04 | | | | dim. 26/04 | | | | lun. 27/04 | | | | mar. 28/04 | | | |
|---|---|---|---|---|---|---|---|---|---|---|---|---|---|---|---|---|---|---|---|---|---|---|---|---|---|---|---|---|
| | 03h | 09h | 15h | 21h | 03h | 09h | 15h | 21h | 03h | 09h | 15h | 21h | 03h | 09h | 15h | 21h | 03h | 09h | 15h | 21h | 03h | 09h | 15h | 21h | 03h | 09h | 15h | 21h |
| Météo | | | | | | | | | | | | | | | | | | | | | | | | | | | | |
| Vent (km/h) | 35 | 35 | 35 | 15 | 15 | 20 | 30 | 20 | 20 | 15 | 20 | 15 | 15 | 20 | 20 | 15 | 15 | 10 | 15 | 10 | 10 | 15 | 20 | 15 | 15 | 25 | 25 | 15 |
| à 3000m | | | | | | | | | | | | | | | | | | | | | | | | | | | | |
| Vent (km/h) | 15 | 25 | 20 | 20 | 20 | 20 | 30 | 15 | 10 | 10 | 15 | 10 | 10 | 10 | 20 | 10 | 10 | 10 | 15 | 10 | 10 | 15 | 20 | 10 | 5 | 15 | 25 | 5 |
| à 2000m | | | | | | | | | | | | | | | | | | | | | | | | | | | | |

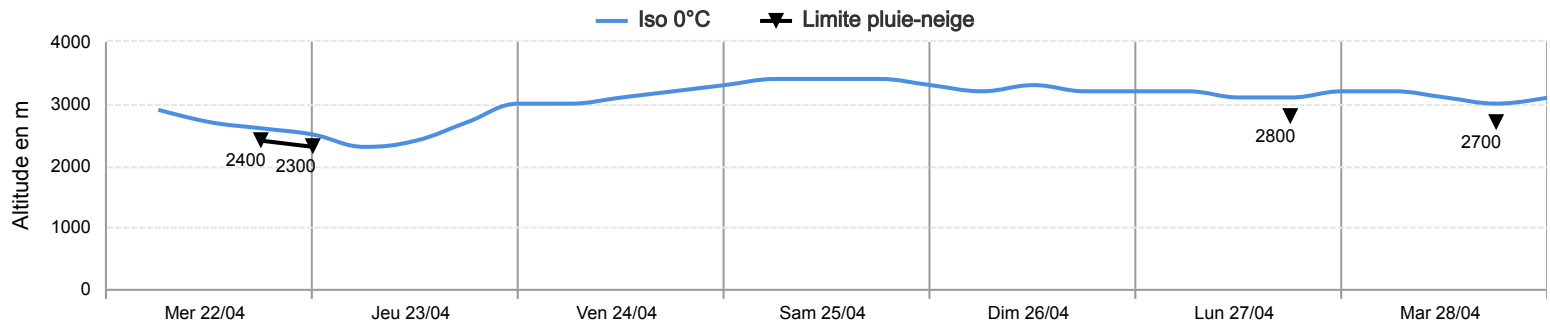


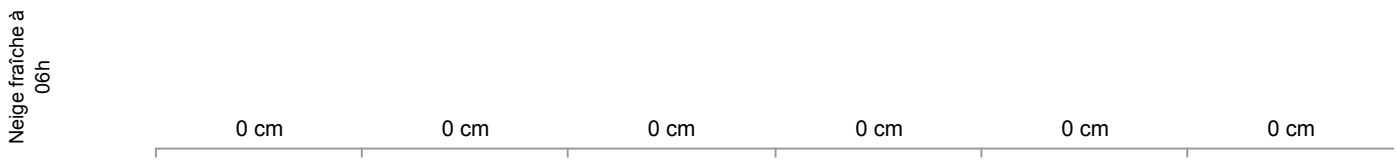


| Risque d'avalanche | mer. 22/04 | jeu. 23/04 | ven. 24/04 | sam. 25/04 | dim. 26/04 | lun. 27/04 | mar. 28/04 |
|---|---|---|---|---|---|---|---|
| | 2 | 2 | 2 | 2 | 2 | 2 | 2 |

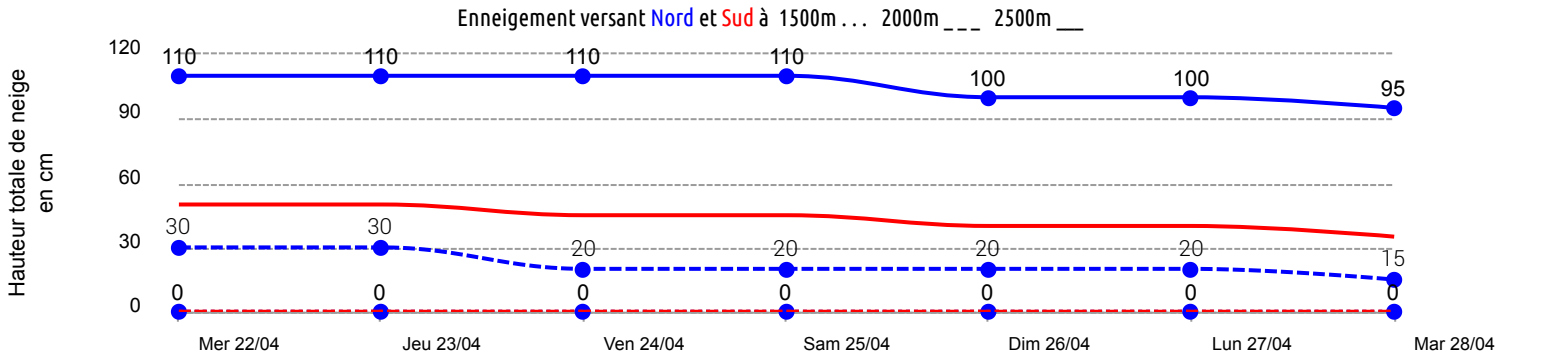


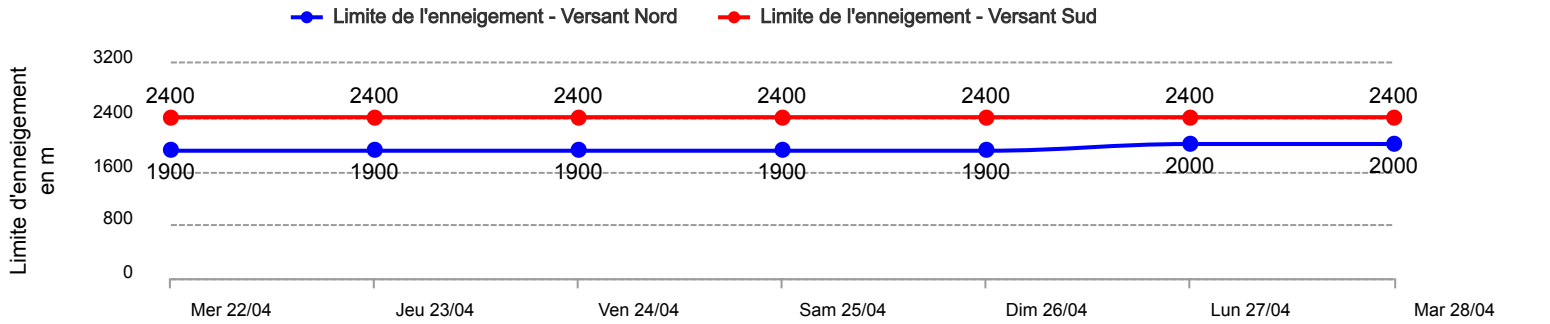


Pour consulter la vigilance en cours, veuillez vous rendre sur le site https://vigilance.meteofrance.fr/fr


Météo-France - 73 avenue de Paris, 94165 Saint-Mandé cedex - Contact : contact@meteo.fr



Rédigé par Météo-France avec la contribution des observateurs du réseau nivo-météorologiques. Partenariat : ANMSM (Maires de Stations de Montagne), DSF (Domaines Skiables de France), ADSP (Directeurs de Pistes et de la Sécurité des Stations de Sports d'Hiver) et autres acteurs de la montagne.



Bulletin neige & avalanches par téléphone au
0 892 68 10 20 Service 0,35 € / min + prix appel