Bulletin d'estimation du risque d'avalanche

(valable en dehors des pistes balisées et ouvertes)

MASSIF : Ubaye

Rédigé le mardi 28 avril 2026 à 16h

Estimation des risques pour le : MERCREDI 29 AVRIL

MANTEAU NEIGEUX PRINTANIER DE FIN DE SAISON BIEN STABLE

2

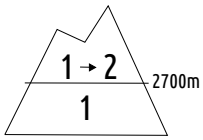

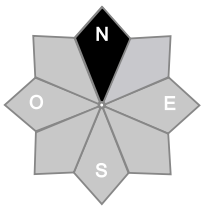

Au-dessus de 2700m indice de risque faible évoluant en limité, plus bas indice faible.

Départs spontanés : seulement en ubacs raides de haute altitude

Déclenchements provoqués : seulement en ubacs raides de haute altitude

Indices de risque : 5 très fort - 4 fort - 3 marqué - 2 limité - 1 faible -- En noir : les pentes les plus dangereuses

Stabilité du manteau neigeux

Situation avalancheuse typique : neige humide

Déclenchements provoqués : le manteau neigeux est très faible pour une fin avril, et très stable. Les instabilités ne sont possibles que dans de rares pentes raides plein nord de haute altitude, au-dessus de 2700/2800 m, où le manteau neigeux n'est pas totalement humidifié jusqu'au sol. Un skieur évoluant en fin de journée peut alors initier un départ de neige humide sur toute l'épaisseur du manteau neigeux, générant une avalanche de taille moyenne (taille 2). Dans les autres orientations, le manteau neigeux est très stable et le danger négligeable.

Départs spontanés : très rares et seulement possibles en versants plein nord de haute altitude. Taille petite à moyenne (taille 1 à 2).

Qualité de la neige

Enneigement exceptionnellement faible pour la période, après plus d'un mois sans précipitations notables et avec un isotherme 0 degré souvent à plus de 3000 m, l'enneigement est digne d'une fin mai, voire début juin. A la nivôse de Restefond, on ne mesure plus que 2 cm de neige. Seule la saison 2001/2002 avait connu une disparition de l'enneigement aussi précoce.

Enneigement skiable à partir de 2200/2300 m en ubacs, avec beaucoup de relief en surface en raison de l'intense fonte jusqu'à 2500/2600 m environ

État de la neige en surface : manteau neigeux sous forme de névé qui continue de fondre rapidement. Les pentes nord de haute altitude (> 2700 m) ne sont pas encore totalement transformées. Faible regel nocturne, puis reprise rapide de l'humidification et de la fonte en cours de journée dans toutes les expositions.

Aperçu météo pour le mercredi 29 avril

	nuit	matin	après-midi	soir

Plutôt ensoleillé le matin. Cumulus et quelques averses l'après-midi sur le relief.

Pluie-Neige	2 800 m			
Iso 0 °C	2 900 m	3 000 m	3 000 m	3 100 m
Vent 2000 m	↖ 10 km/h	↖ 15 km/h	↑ 20 km/h	↖ 10 km/h
Vent 3000 m	↗ 20 km/h	↖ 15 km/h	→ 20 km/h	→ 15 km/h

Épaisseur de neige hors-piste

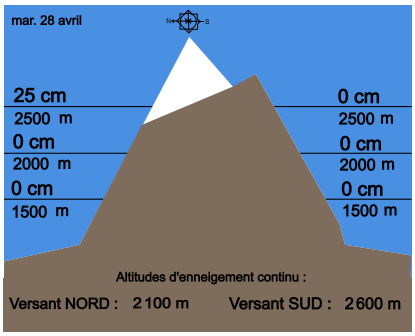

Précipitations à 1800 m

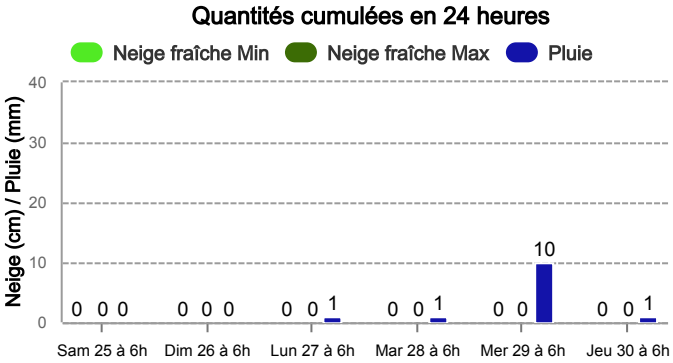

Tendance du jeudi 30 avril

1

Indice de risque faible

Peu d'évolution ou tendance à la baisse. Manteau neigeux bien stabilié. Risque faible d'une avalanche de neige humide en pente nord de haute altitude.

Pour consulter la vigilance en cours, veuillez vous rendre sur le site https://vigilance.meteofrance.fr/fr

Météo-France - 73 avenue de Paris, 94165 Saint-Mandé cedex - Contact : contact@meteo.fr

Rédigé par Météo-France avec la contribution des observateurs du réseau nivo-météorologiques. Partenariat : ANMSM (Maires de Stations de Montagne), DSF (Domaines Skiables de France), ADSP (Directeurs de Pistes et de la Sécurité des Stations de Sports d'Hiver) et autres acteurs de la montagne.

Bulletin neige & avalanches par téléphone au

0 892 68 10 20 Service 0,35 € / min + prix appel

RÉPUBLIQUE FRANÇAISE
Liberté Égalité Fraternité

METEO FRANCE
À VOS CÔTÉS, DANS UN CLIMAT QUI CHANGE

Bulletin d'estimation du risque d'avalanche

(valable en dehors des pistes balisées et ouvertes)

MASSIF : Ubaye

Rédigé le mardi 28 avril 2026 à 16h

Conditions nivo-météo des 7 derniers jours

	mer. 22/04				jeu. 23/04				ven. 24/04				sam. 25/04				dim. 26/04				lun. 27/04				mar. 28/04			
	03h	09h	15h	21h	03h	09h	15h	21h	03h	09h	15h	21h	03h	09h	15h	21h	03h	09h	15h	21h	03h	09h	15h	21h	03h	09h	15h	21h
Météo																												
Vent (km/h)	35	35	40	20	15	15	20	10	15	15	20	15	15	20	20	15	10	15	20	10	10	15	20	20	20	20	25	15
à 3000m																												
Vent (km/h)	15	25	30	15	10	10	15	10	10	10	20	5	5	10	25	5	5	10	20	10	5	10	20	15	5	15	25	10
à 2000m																												

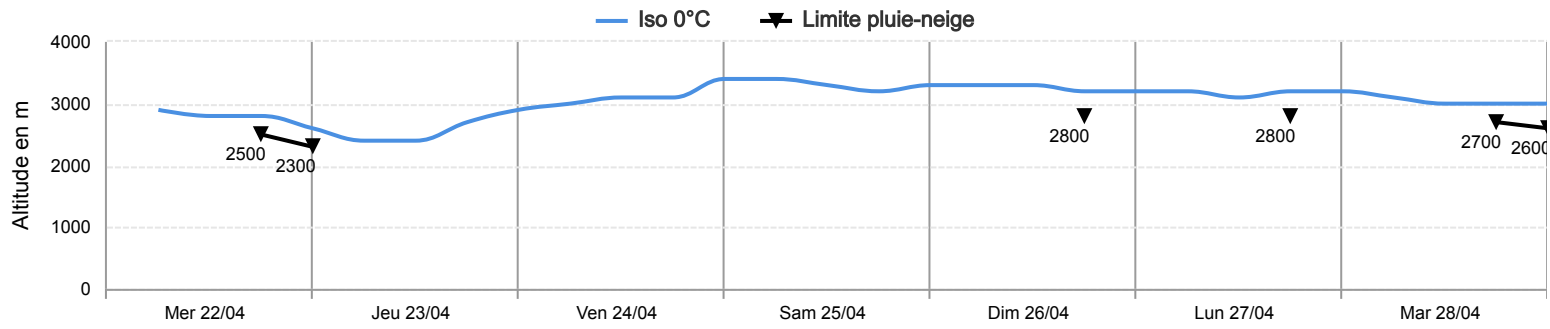

Neige fraîche à 06h

mer. 22/04	jeu. 23/04	ven. 24/04	sam. 25/04	dim. 26/04	lun. 27/04
0 cm	0 cm	0 cm	0 cm	0 cm	0 cm

Risque d'avalanche	mer. 22/04	jeu. 23/04	ven. 24/04	sam. 25/04	dim. 26/04	lun. 27/04	mar. 28/04
	2	2	2	2	2	2	2

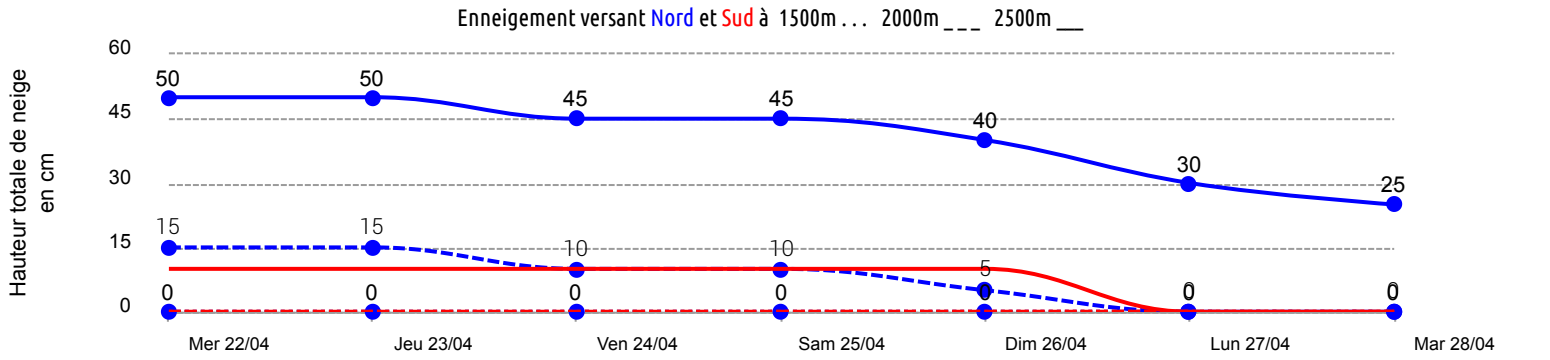

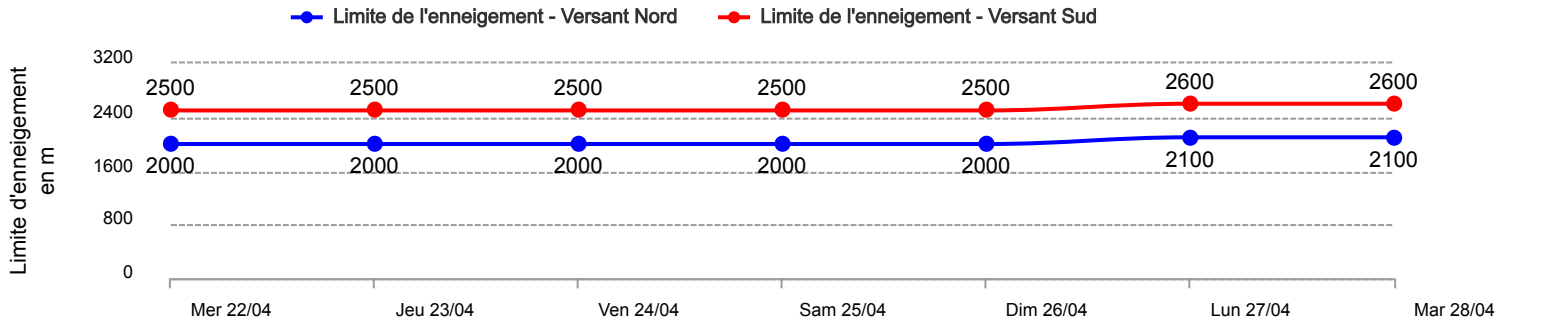

Pour consulter la vigilance en cours, veuillez vous rendre sur le site https://vigilance.meteofrance.fr/fr

Météo-France - 73 avenue de Paris, 94165 Saint-Mandé cedex - Contact : contact@meteo.fr

Rédigé par Météo-France avec la contribution des observateurs du réseau nivo-météorologiques. Partenariat : ANMSM (Maires de Stations de Montagne), DSF (Domaines Skiables de France), ADSP (Directeurs de Pistes et de la Sécurité des Stations de Sports d'Hiver) et autres acteurs de la montagne.

Bulletin neige & avalanches par téléphone au
0 892 68 10 20 Service 0,35 € / min + prix appel