Bulletin d'estimation du risque d'avalanche

(valable en dehors des pistes balisées et ouvertes)

MASSIF : Cerdagne Canigou

Rédigé le mardi 28 avril 2026 à 17h

Estimation des risques pour le : MERCREDI 29 AVRIL

POURSUITE DE L'HUMIDIFICATION EN PROFONDEUR

2

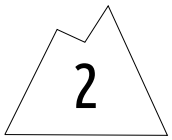

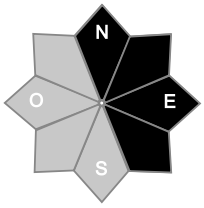

Indice de risque limité.

Départs spontanés : avalanches de fond en neige humide de taille moyenne voire gandes

Déclenchements provoqués : départs ponctuels en neige humide possibles au passage d'un skieur

Indices de risque : 5 très fort - 4 fort - 3 marqué - 2 limité - 1 faible -- En noir : les pentes les plus dangereuses

Stabilité du manteau neigeux

Situation avalancheuse typique : neige humide avalanches de fond

Départs spontanés :

- Des **avalanches de fond** emportant l'ensemble du manteau neigeux sont possibles en toutes orientations (fissures/reptations et avalanches de fond signalées ces derniers jours), plutôt au-delà de 2200/2300m. Elles seront de taille moyenne, voire grande dans les zones de plus fortes accumulations (pentes nord à sud-est) avec des cassures pouvant localement dépasser les 1 à 2m d'épaisseur. Selon la configuration locale ces avalanches peuvent finir leur parcours en dessous de la limite d'enneigement.
- Avec un manteau intégralement humidifié, regelant peu en surface, des départs ponctuels d'**avalanches de neige humide**, de taille petite à moyenne sont attendus dès le matin dans les pentes Est. Elles deviennent plus fréquentes au cours de la journée et se propagent aux versants Sud puis Ouest.

Déclenchements provoqués :

Un skieur coupant une pente raide déjà bien humidifiée pourra favoriser un départ ponctuel de taille petite à plus rarement moyenne. Ces coulées peuvent emporter les skis et provoquer la chute. Les pentes d'altitude orientées Est le matin puis Sud et enfin Ouest en fin de journée sont les plus exposées à ce risque.

Autres :

- des corniches encore imposantes sont susceptibles de céder spontanément et peuvent déclencher une avalanche dans leur chute
- les ponts de neige peuvent également céder au passage d'un randonneur

Qualité de la neige

Enneigement :

L'enneigement dans nos massifs reste bon pour la saison, encore nettement supérieur à celui des derniers hivers. La limite skiable est au mieux vers 1800/1900m en nord et 2000/2100m en sud. On trouve ensuite rapidement une épaisseur de neige conséquente qui dépasse encore souvent les 1 à 1,50 m à 2000m en nord, et 2 à 3 m à 2500m. Les cols et crêtes ouest à nord-ouest sont toutefois moins garnis en neige, les rochers affleurent de plus en plus en surface.

Qualité de la neige :

Au lever du jour, seules les pentes situées au-dessus de 2500m devraient connaitre un regel en surface. En journée la neige, de type névé dans les versants ensoleillés, légèrement ocre du fait des poussières sahariennes, devient très humide puis détrempée à toutes altitudes et orientations. À noter enfin la présence de rigoles de fonte en surface.

Aperçu météo pour le mercredi 29 avril

	nuit	matin	après-midi	soir
	Rares ondées dans l'après-midi			
Pluie-Neige			2 900 m	
Iso 0 °C	3 100 m	3 200 m	3 300 m	3 400 m
Vent 2000 m	30 km/h	35 km/h	40 km/h	25 km/h
Vent 3000 m	45 km/h	50 km/h	50 km/h	45 km/h

Épaisseur de neige hors-piste

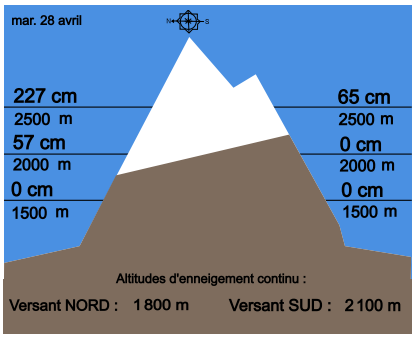

Précipitations à 1800 m

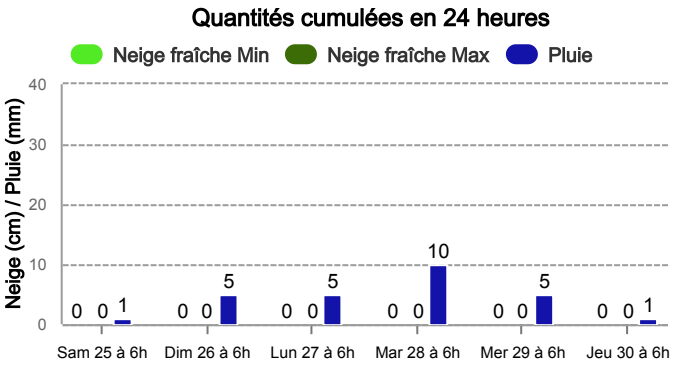

Tendance du jeudi 30 avril

2 **Indice de risque limité**

Maintien d'un risque limité

Pour consulter la vigilance en cours, veuillez vous rendre sur le site https://vigilance.meteofrance.fr/fr

Météo-France - 73 avenue de Paris, 94165 Saint-Mandé cedex - Contact : contact@meteo.fr

Bulletin neige & avalanches par téléphone au 0 892 68 10 20 Service 0,35 € / min + prix appel

Rédigé par Météo-France avec la contribution des observateurs du réseau nivo-météorologiques. Partenariat : ANMSM (Maires de Stations de Montagne), DSF (Domaines Skiables de France), ADSP (Directeurs de Pistes et de la Sécurité des Stations de Sports d'Hiver) et autres acteurs de la montagne.

RÉPUBLIQUE FRANÇAISE
Liberté Égalité Fraternité

METEO FRANCE
À VOS CÔTÉS, DANS UN CLIMAT QUI CHANGE

Bulletin d'estimation du risque d'avalanche
(valable en dehors des pistes balisées et ouvertes)
MASSIF : Cerdagne Canigou

Rédigé le mardi 28 avril 2026 à 17h

Conditions nivo-météo des 7 derniers jours

	mer. 22/04				jeu. 23/04				ven. 24/04				sam. 25/04				dim. 26/04				lun. 27/04				mar. 28/04			
	03h	09h	15h	21h	03h	09h	15h	21h	03h	09h	15h	21h	03h	09h	15h	21h	03h	09h	15h	21h	03h	09h	15h	21h	03h	09h	15h	21h
Météo																												
Vent (km/h)	40	30	35	15	20	20	25	10	20	15	20	20	25	20	20	15	10	10	20	10	10	10	25	15	20	20	35	25
à 3000m																												
Vent (km/h)	20	20	25	10	15	15	20	10	15	15	20	10	15	20	20	10	10	15	20	10	10	15	20	10	10	15	30	20
à 2000m																												

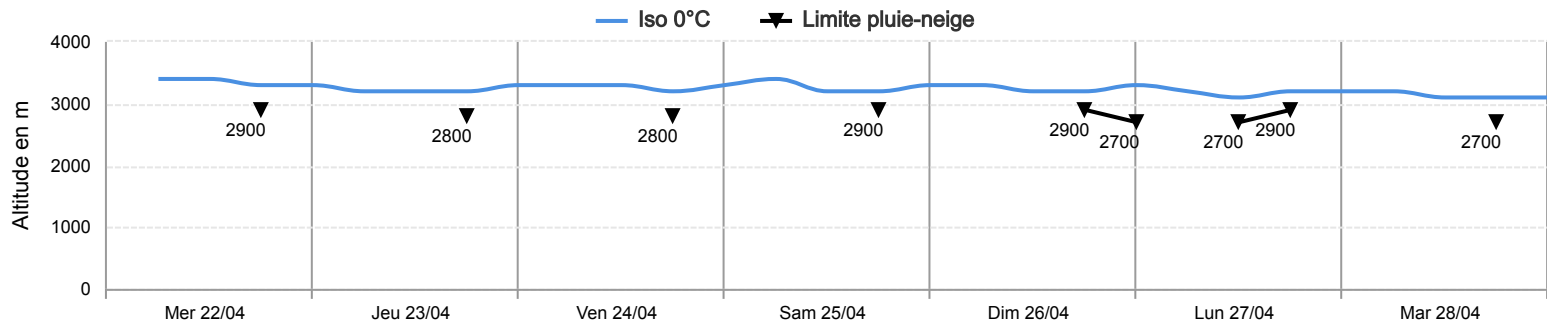

Neige fraîche à 06h

mer. 22/04	jeu. 23/04	ven. 24/04	sam. 25/04	dim. 26/04	lun. 27/04
0 cm	0 cm	0 cm	0 cm	0 cm	0 cm

Risque d'avalanche	mer. 22/04	jeu. 23/04	ven. 24/04	sam. 25/04	dim. 26/04	lun. 27/04	mar. 28/04
	3	2	2	2	2	2	2

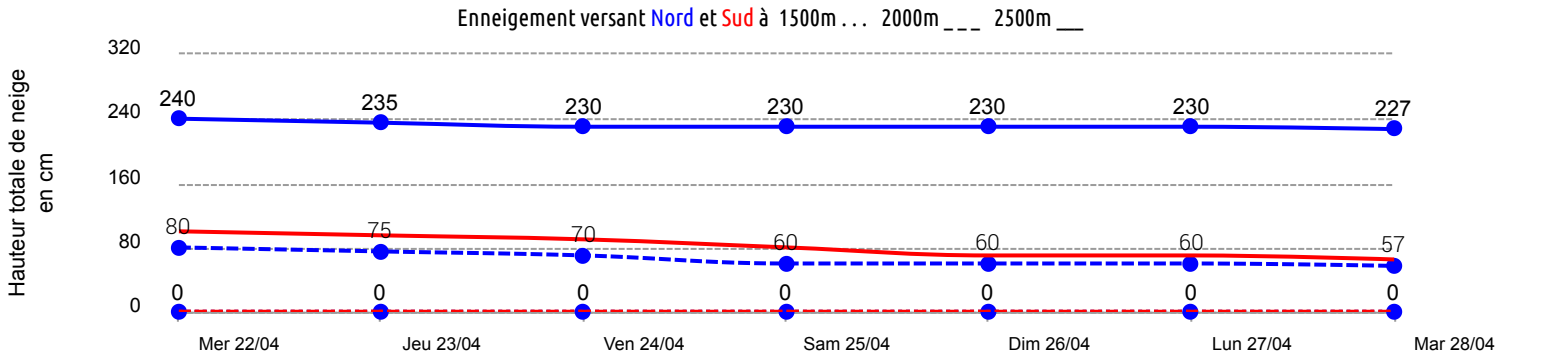

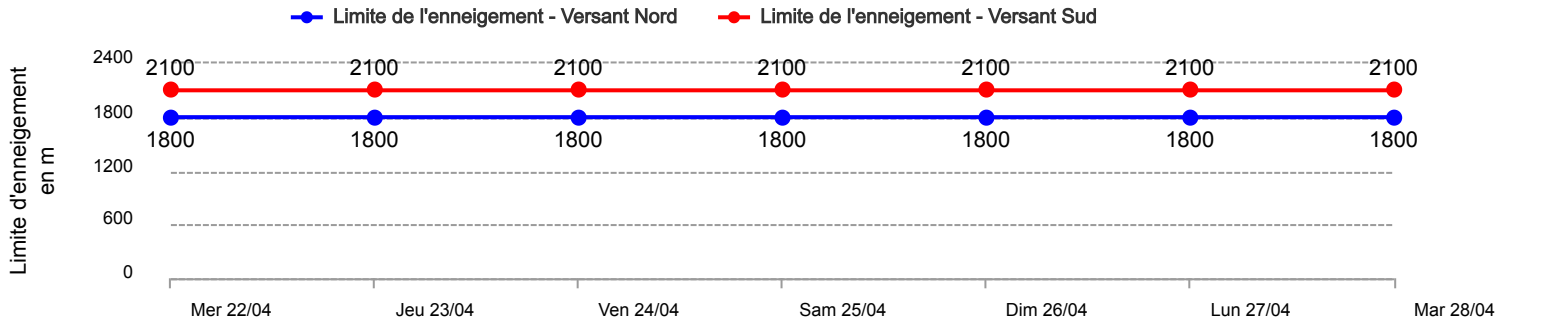

Pour consulter la vigilance en cours, veuillez vous rendre sur le site https://vigilance.meteofrance.fr/fr

Météo-France - 73 avenue de Paris, 94165 Saint-Mandé cedex - Contact : contact@meteo.fr

Bulletin neige & avalanches par téléphone au
0 892 68 10 20 Service 0,35 € / min + prix appel

Rédigé par Météo-France avec la contribution des observateurs du réseau nivo-météorologiques. Partenariat : ANMSM (Maires de Stations de Montagne), DSF (Domaines Skiables de France), ADSP (Directeurs de Pistes et de la Sécurité des Stations de Sports d'Hiver) et autres acteurs de la montagne.