RÉPUBLIQUE FRANÇAISE
Liberté Égalité Fraternité

METEO FRANCE
À VOS CÔTÉS, DANS UN CLIMAT QUI CHANGE

Bulletin d'estimation du risque d'avalanche
(valable en dehors des pistes balisées et ouvertes)
MASSIF : Luchonnais

Rédigé le mardi 28 avril 2026 à 17h

Estimation des risques pour le : MERCREDI 29 AVRIL

MANTEAU NEIGEUX TRÈS HUMIDE DÈS LE MATIN APRÈS UNE NUIT NUAGEUSE, VENTÉE DE SUD

2

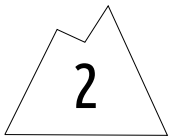

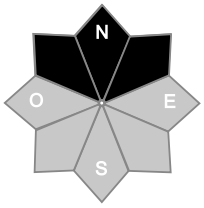

Indice de risque limité.

Départs spontanés : en neige humide, avalanches de fond moyennes à rarement grandes.

Déclenchements provoqués : en neige humide seulement.

Indices de risque : 5 très fort - 4 fort - 3 marqué - 2 limité - 1 faible -- En noir : les pentes les plus dangereuses

Stabilité du manteau neigeux

Situation avalancheuse typique : neige humide avalanches de fond

Départs spontanés :
Activité attendue rapidement en matinée, sous forme de départs ponctuels de neige humide au fil de l'ensoleillement, en général de taille petite à moyenne. De rares grandes avalanches sont possibles par départ d'une avalanche de fond, en général depuis une fissure déjà ouverte. Leur chronologie de départ est moins liée à l'ensoleillement, les zones de départs se situent en général en secteurs nord-est à nord-ouest, au-dessus de 2200m.

Déclenchements provoqués : en neige humide seulement.
Le passage d'un skieur ou d'un randonneur dans la neige très humide peut favoriser un départ ponctuel en général de petite taille, parfois moyenne, et ce dès le matin avec une neige probablement molle dès le lever du jour.

Autres :
- **corniches et ponts de neige** encore en place **fragiles et peu résistants**, pouvant **céder** dès le matin **spontanément** ou sous le **poids d'une seule personne, même s'ils semblent épais**
- les **chemins de randonnée déjà déneigés** mais **situés sous les secteurs raides d'altitude encore chargés** peuvent être **atteints pas une avalanche de fond de taille moyenne à parfois grande** dans l'après-midi.

Qualité de la neige

Enneigement : encore correct pour la saison au-dessus de 2200m, plutôt déficitaire plus bas, débutant encore vers 1800m en nord et au-dessus de 2100m en sud. Les limites de cet enneigement remontent progressivement dans la douceur ambiante.
État de la neige :
Neige humide assez portante le matin, se ramollissant encore au fil de la journée, avec des enfoncements à pied dépassant 40 cm.

Aperçu météo pour le mercredi 29 avril

	nuit	matin	après-midi	soir
	Souvent nuageux, quelques averses en matinée, plus sec l'après-midi, avant un probable passage orageux en soirée			
Pluie-Neige				
Iso 0 °C	3 100 m	3 200 m	3 200 m	3 300 m
Vent 2000 m	↑ 35 km/h	↑ 35 km/h	↑ 35 km/h	↑ 30 km/h
Vent 3000 m	↑ 30 km/h	↗ 40 km/h	↗ 45 km/h	↑ 45 km/h

Épaisseur de neige hors-piste

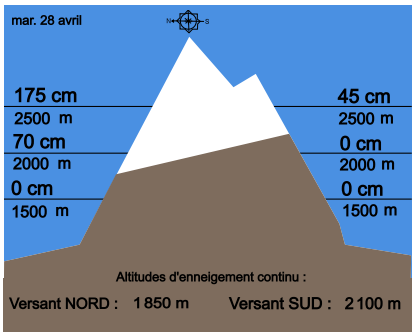

Précipitations à 1800 m

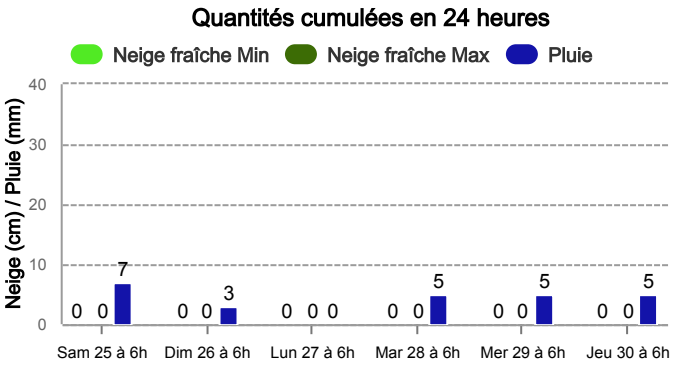

Tendance du jeudi 30 avril

2

Indice de risque limité

Peu d'évolution, regel toujours incertain

Pour consulter la vigilance en cours, veuillez vous rendre sur le site https://vigilance.meteofrance.fr/fr

Météo-France - 73 avenue de Paris, 94165 Saint-Mandé cedex - Contact : contact@meteo.fr

Rédigé par Météo-France avec la contribution des observateurs du réseau nivo-météorologiques. Partenariat : ANMSM (Maires de Stations de Montagne), DSF (Domaines Skiables de France), ADSP (Directeurs de Pistes et de la Sécurité des Stations de Sports d'Hiver) et autres acteurs de la montagne.

Bulletin neige & avalanches par téléphone au
0 892 68 10 20 Service 0,35 € / min + prix appel

RÉPUBLIQUE FRANÇAISE
Liberté Égalité Fraternité

METEO FRANCE
À VOS CÔTÉS, DANS UN CLIMAT QUI CHANGE

Bulletin d'estimation du risque d'avalanche
(valable en dehors des pistes balisées et ouvertes)

MASSIF : Luchonnais

Rédigé le mardi 28 avril 2026 à 17h

Conditions nivo-météo des 7 derniers jours

	mer. 22/04				jeu. 23/04				ven. 24/04				sam. 25/04				dim. 26/04				lun. 27/04				mar. 28/04			
	03h	09h	15h	21h	03h	09h	15h	21h	03h	09h	15h	21h	03h	09h	15h	21h	03h	09h	15h	21h	03h	09h	15h	21h	03h	09h	15h	21h
Météo																												
Vent (km/h)	35	40	25	30	35	20	30	45	30	25	20	15	20	25	15	25	25	20	20	20	20	20	20	15	25	20	30	30
à 3000m																												
Vent (km/h)	35	25	20	10	15	15	20	25	20	10	15	10	5	10	10	10	5	10	10	5	5	5	5	10	10	10	20	20
à 2000m																												

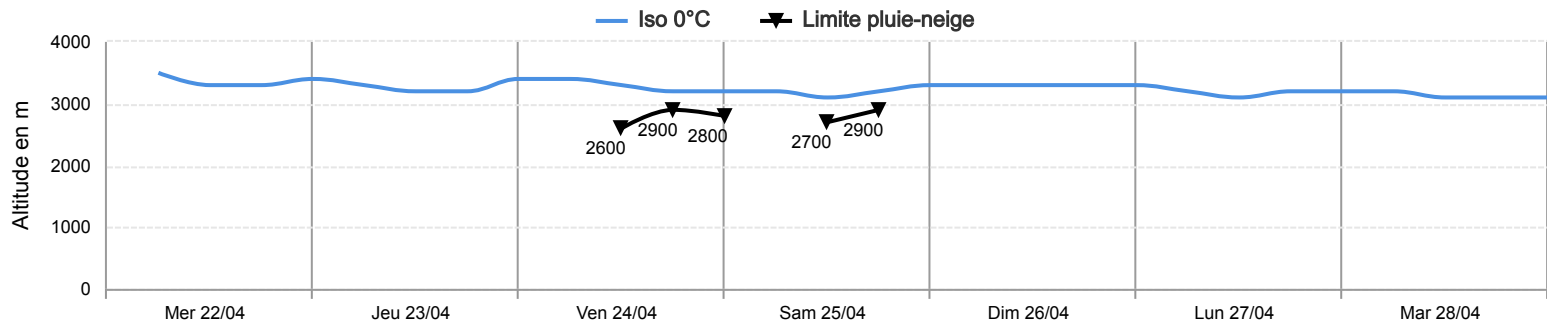

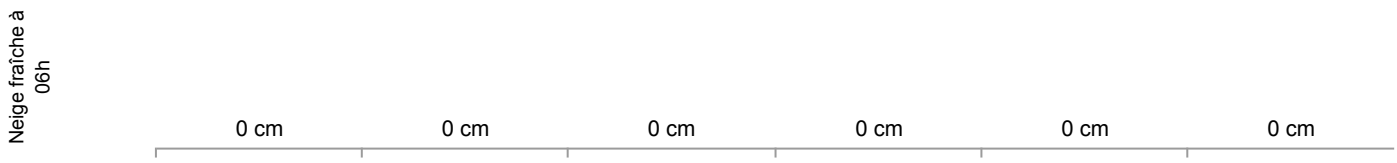

Risque d'avalanche	mer. 22/04	jeu. 23/04	ven. 24/04	sam. 25/04	dim. 26/04	lun. 27/04	mar. 28/04
	3	3	3	3	3	2	2

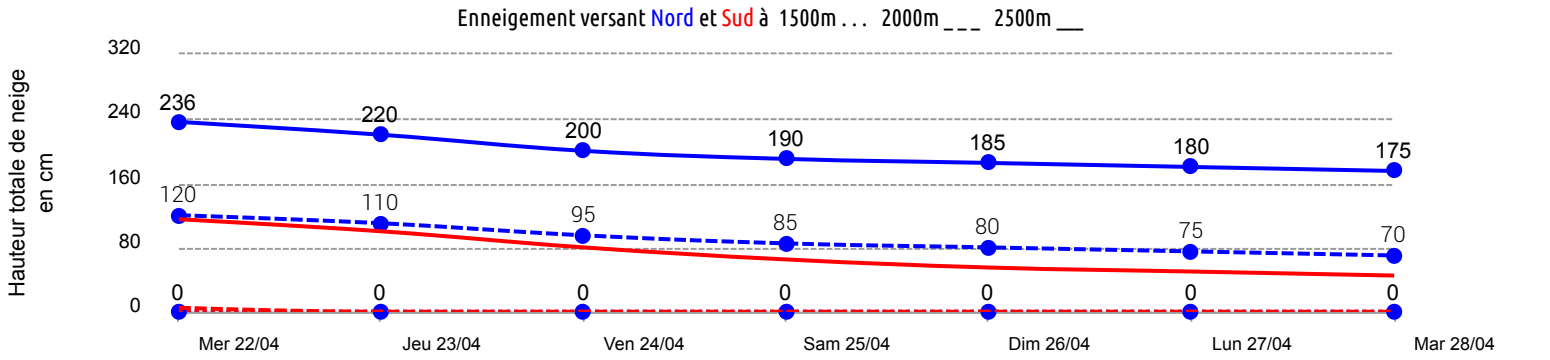

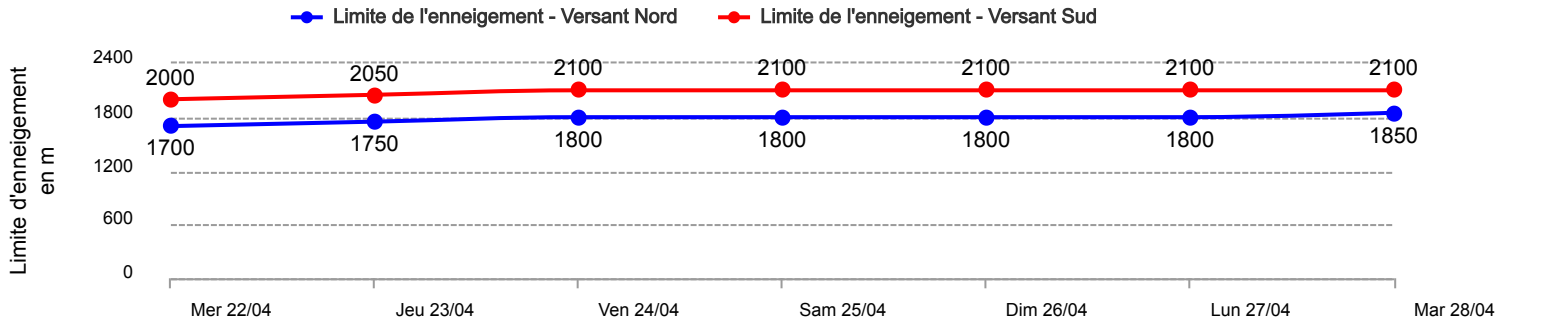

Pour consulter la vigilance en cours, veuillez vous rendre sur le site https://vigilance.meteofrance.fr/fr

Météo-France - 73 avenue de Paris, 94165 Saint-Mandé cedex - Contact : contact@meteo.fr

Rédigé par Météo-France avec la contribution des observateurs du réseau nivo-météorologiques. Partenariat : ANMSM (Maires de Stations de Montagne), DSF (Domaines Skiables de France), ADSP (Directeurs de Pistes et de la Sécurité des Stations de Sports d'Hiver) et autres acteurs de la montagne.

Bulletin neige & avalanches par téléphone au
0 892 68 10 20 Service 0,35 € / min + prix appel