GOBIERNO DE ESPAÑA
VICEPRESIDENCIA TERCERA DEL GOBIERNO
MINISTERIO PARA LA TRANSICIÓN ECOLÓGICA Y EL RETO DEMOGRÁFICO

Boletín de información nivológica y de peligro de aludes

Pirineo Navarro y Aragonés

aemet Agencia Estatal de Meteorología

miércoles, 29 de abril de 2026

Pronóstico hasta las 24 horas del jueves, día 30 de abril

(Válido fuera de pistas de esquí balizadas y abiertas)

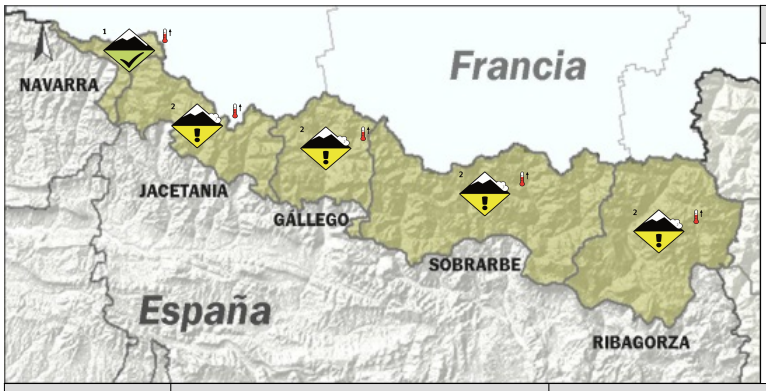

Problemas de aludes

Nieve húmeda

Deslizamientos basales

Macizo	Peligro	Problemas de aludes, cota, orientación, tamaño	Innivación observada (m)
Navarra	1 Débil	Nieve húmeda: N O E S, 1	2026-04-29 N S Cota más baja caras N
		Deslizamientos basales: N O E S, 1	
Jacetania	2 Limitado	Nieve húmeda: N O E S, 2	2026-04-29 N S Cota más baja caras N
		Deslizamientos basales: N O E S, 2	
Gállego	2 Limitado	Nieve húmeda: N O E S, 2	2026-04-29 N S Cota más baja caras N
		Deslizamientos basales: N O E S, 2	

Boletín de información nivológica y de peligro de aludes

Pirineo Navarro y Aragonés

Sobrarbe	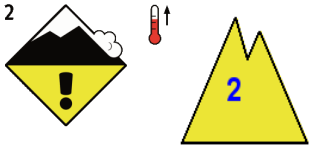 **Limitado**	**Nieve húmeda**  **Deslizamientos basales** 	2026-04-29 Cota más baja caras N
Ribagorza	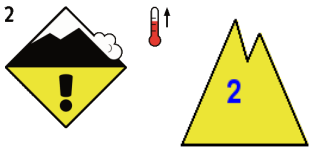 **Limitado**	**Nieve húmeda** **Deslizamientos basales** 	2026-04-29 Cota más baja caras N

Estado del manto y observaciones recientes

Prosiguen los procesos de merma y humidificación del manto nivoso a consecuencia de la insolación, las temperaturas elevadas y las precipitaciones, las cuales se van produciendo prácticamente a diario. Durante la jornada de ayer y las primeras horas de hoy, estas han afectado a la mayor parte de los macizos, aunque de manera más anecdótica en los orientales.

El manto se halla básicamente restringido a cotas altas y presenta una clara asimetría norte-sur, con las solanas muy peladas y las umbrías con cierta continuidad a partir de 2200 metros, aunque cada vez muestran mayores afloramientos rocosos. En algunos enclaves de estas, todavía se reportan valores en torno a 60 cm en cota 2100.

La nieve está muy humidificada, con predominio del grano redondo y el rehielo nocturno está siendo muy poco efectivo.

Evolución del manto y peligro de aludes para el jueves, día 30

Problema de nieve húmeda. Problema de deslizamientos basales.

Para mañana se espera un rehielo particularmente limitado debido a la presencia de nubosidad baja y a la probabilidad de precipitaciones de madrugada.

Ya desde primeras horas se podrán producir algunos aludes de nieve húmeda en laderas lo suficientemente inclinadas. El peligro será mayor en zonas de apertura de claros o de precipitaciones y conforme avance el día. Estos aludes podrán ser naturales o accidentales y de tamaño pequeño o mediano.

También se podrá producir algún deslizamiento basal, preferentemente en laderas herbosas o

AEMET. Se autoriza la reproducción de su contenido citando la fuente.

de roca lisa con la suficiente inclinación, generalmente de tamaño mediano.

Predicción meteorológica para el jueves, día 30

Pirineo navarro:
Predominio de nuboso o muy nuboso, con visibilidad localmente reducida. Lluvias y chubascos ocasionales, más probables de madrugada, que podrán ir acompañados de tormenta. Temperaturas con pocos cambios. Viento fuerte de componente sur de madrugada, disminuyendo a flojo o moderado.

Pirineo aragonés:
Predominio de nuboso o muy nuboso, con visibilidad localmente reducida. Lluvias y chubascos dispersos, posiblemente tormentosos, probables a lo largo de todo el día, que podrán ser de nieve por encima de 2500-2600 metros. Temperaturas mínimas con pocos cambios. Máximas en ligero o moderado ascenso. Viento flojo o moderado, con predominio de la componente sur.

Datos en la atmósfera libre:

Altitud de la isoterma de 0 ºC: 3100 m
Altitud de la isoterma de -10 ºC: 4700 m

Viento a 1500 m: S 10 km/h
Viento a 3000 m: SW 40 km/h

Evolución para el viernes día 1

Nivel de peligro con pocos cambios.

(Información elaborada a partir de los datos recibidos de los refugios de Linza, Lizara, Respomuso, Panticosa, Bachimaña, Góriz, Pineta, Angel Orús y Belagua y de la estación de esquí de Panticosa (lagos))

Escala europea de peligro de aludes

Débil | Limitado | Notable | Fuerte | Muy Fuerte

Problemas de aludes

Nieve reciente | Placas de viento | Capas débiles persistentes | Nieve húmeda | Deslizamientos basales | Sin problema evidente

Nota1: Se recuerda que, siempre que haya nieve, la ausencia total de peligro no existe. Hay que tener presente que en circunstancias desfavorables, con aludes de tamaño 1 (alud pequeño o colada) y tamaño 2 (alud mediano), se pueden sufrir severos daños personales.

Nota2: Los BPA se elaboran en base a información meteorológica así como al estado del manto nivoso a través de sondeos puntuales. Se advierte a los usuarios de la variabilidad de esta información al extrapolarla a zonas extensas de montaña. Por ello, AEMET no se hace responsable de su uso para la toma de decisiones que conciernen a la seguridad personal, ni de los riesgos físicos o materiales de ellas derivadas.

AEMET. Se autoriza la reproducción de su contenido citando la fuente.