Donnerstag 30.04.2026

Veröffentlicht am 29.04.2026 um 17:00

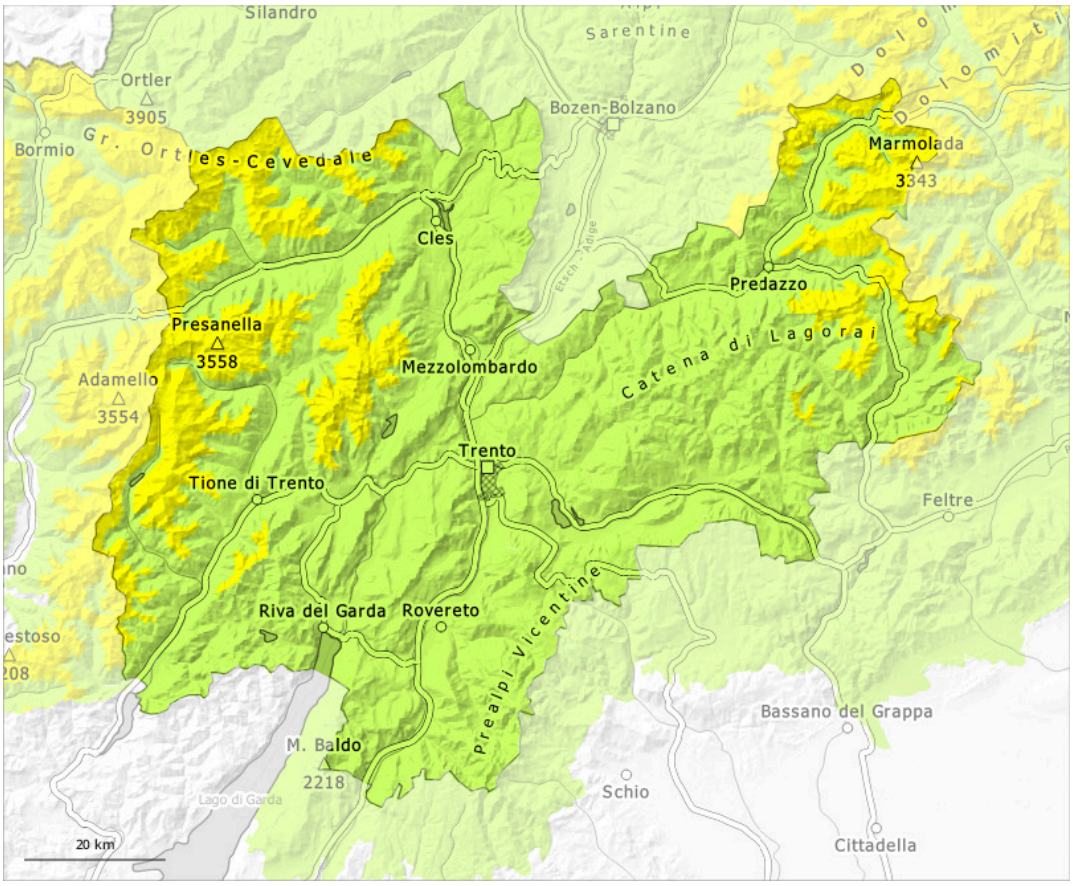

1	2	3	4	5
gering	mäßig	erheblich	groß	sehr groß

Gefahrenstufe 2 - Mäßig

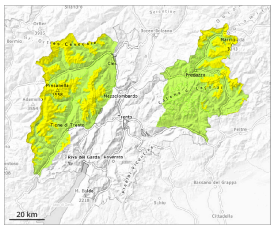

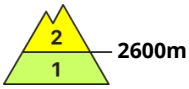

Tendenz: Lawinengefahr bleibt gleich
am Freitag, den 01.05.2026

Nassschnee

2600m

Nassschnee beachten.

Mit Neuschnee und Wind entstanden in den letzten Tagen in hohen Lagen und im Hochgebirge Triebschneeansammlungen.
Mit der Erwärmung steigt die Lawinengefahr allmählich an. Die feuchten Lawinen können an sehr steilen Hängen spontan abgehen und vereinzelt mittlere Größe erreichen.
Einzelne Gefahrenstellen liegen an sehr steilen Schattenhängen oberhalb von rund 2600 m. Lawinen können mit meist großer Belastung ausgelöst werden und mittlere Größe erreichen.

Schneedecke

Gefahrenmuster gm.10: frühjahrssituation

Unterhalb von rund 2500 m liegt wenig Schnee. Die frühlingshaften Wetterbedingungen führen zu einer raschen Anfeuchtung der Schneedecke. Die Schneeoberfläche gefriert nur knapp und weicht rasch auf. Steile West-, Nord- und Osthänge oberhalb von rund 2500 m: Im unteren Teil der Altschneedecke sind kantig aufgebaute Schwachschichten vorhanden.

Tendenz

Die Lawinengefahr bleibt bestehen.

Gefahrenstufe 1 - Gering

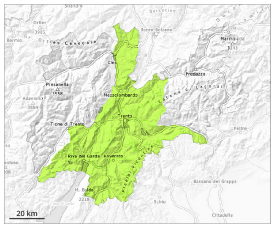

1

Tendenz: Lawinengefahr bleibt gleich
am Freitag, den 01.05.2026

Geringe Lawinengefahr.

Die Gefahr von feuchten und nassen Lawinen besteht schon am Morgen. Aus noch nicht entladenen Einzugsgebieten sind einzelne nasse Lawinen möglich, aber meist nur kleine.
Vorsicht an extrem steilen Schattenhängen.

Schneedecke

Gefahrenmuster gm.10: frühjahrssituation

Oberhalb von rund 2000 m liegt erst wenig Schnee. Dies in Rinnen und Mulden an Schattenhängen. Die nächtliche Abstrahlung ist verbreitet kaum vorhanden. Die Schneeoberfläche weicht rasch auf.

Tendenz

Geringe Lawinengefahr.