ICGC Institut Cartogràfic i Geològic de Catalunya

Servei Meteorològic de Catalunya meteo.cat

Boletín de peligro de aludes para el Pirineo de Catalunya
Del 29/04/2026 al 30/04/2026

(Válido fuera pistas de esquí y zonas no controladas)

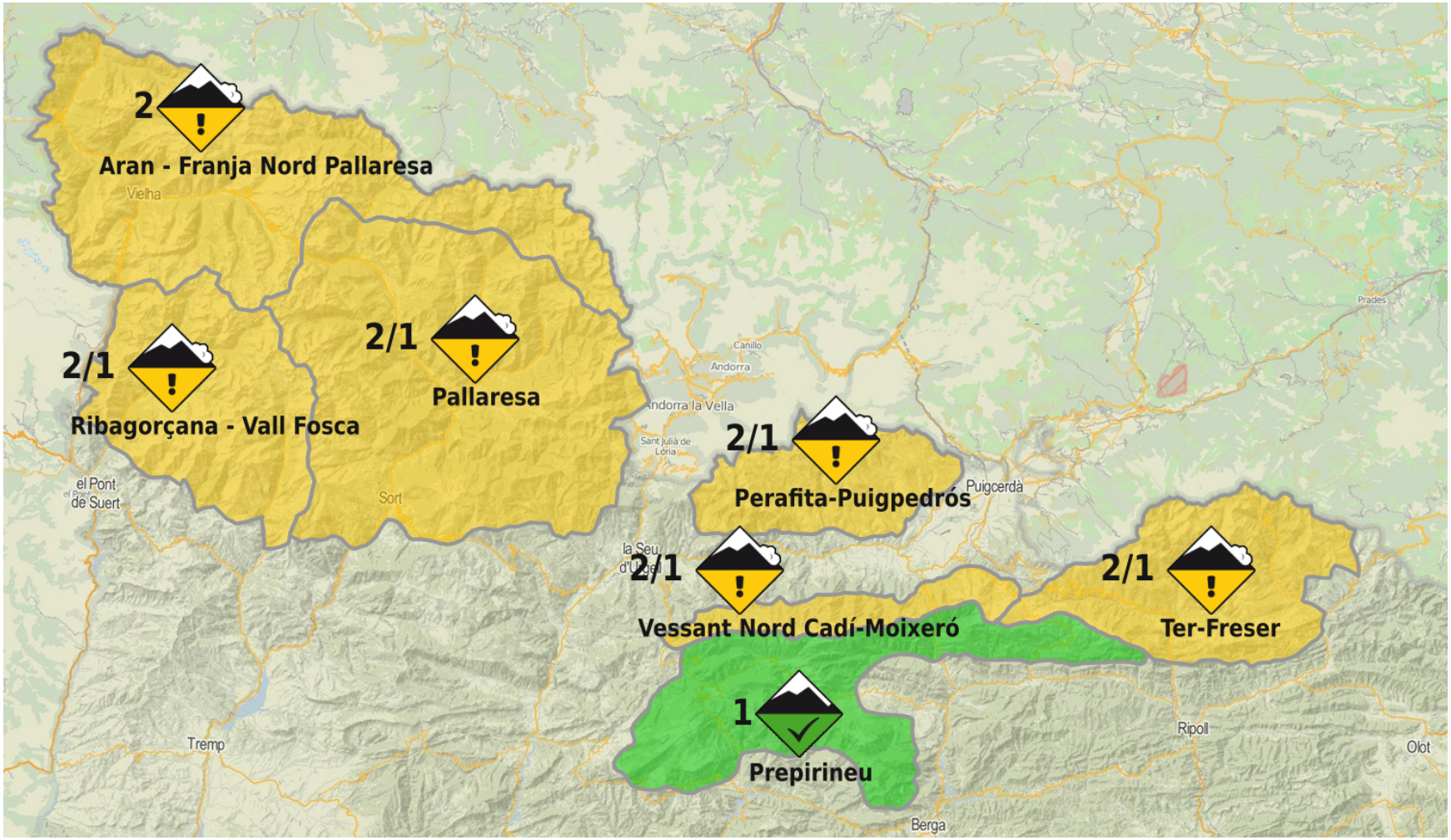

5 MUY FUERTE	4 FUERTE	3 NOTABLE	2 LIMITADO	1 DÉBIL

ICGC Institut Cartogràfic i Geològic de Catalunya

Servei Meteorològic de Catalunya

Boletín de peligro de aludes Aran - Franja Nord Pallaresa Del 29/04/2026 al 30/04/2026

(Válido fuera pistas de esquí y zonas no controladas)

LIMITADO (2)

Situación primaria

Deslizamientos basales **Distribución** **Tamaño** **Origen** **Tendencia**

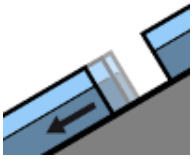

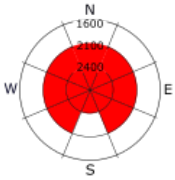

Situación secundaria

Nieve húmeda **Distribución** **Tamaño** **Origen** **Tendencia**

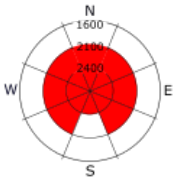

Estado del manto nivoso

Se espera un aumento de la humedad y nubosidad, tanto diurna como nocturna, a partir del miércoles. Con estas condiciones y la continuidad de las altas temperaturas, no se espera rehielo matinal para los próximos días. El manto se presenta muy húmedo en su conjunto y aún podrá humedecerse más con las lluvias previstas.

Continúa la probabilidad de deslizamientos basales, por encima de unos 2.000 m y en cualquier orientación y momento del día, en vertientes propicias sobre superficie lisa herbosa o rocosa, que podrán alcanzar hasta tamaño 2, medio. Hay que evitar los puntos donde se observen grietas en el manto.

También son probables aludes de nieve húmeda, de tamaño pequeño o medio, especialmente en laderas de fuerte inclinación, que pueden desencadenarse a cualquier hora del día, sobre todo de forma accidental, y más probables a partir de mediodía o en momentos de chubasco de forma natural.

Distribución del manto nivoso

Hay nieve en el suelo con cierta continuidad y esquiable por encima de unos 2.100 m en umbrías y es más discontinua en solanas, a partir de 2.200 m. Los espesores a unos 2.300 m rondan los 100-130 cm, con sobreacumulaciones que todavía superan los 150 cm. Los valores son los normales para la época.

Tendencia para las próximas 48-72h

Las condiciones de estabilidad del manto no experimentarán demasiados cambios. Evolución del peligro: ESTACIONARIO.

El próximo boletín será emitido el día 2026-04-30

5 MUY FUERTE	4 FUERTE	3 NOTABLE	2 LIMITADO	1 DÉBIL

EAWS EUROPEAN AVALANCHE WARNING SERVICES

ICGC Institut Cartogràfic i Geològic de Catalunya

Servei Meteorològic de Catalunya

Boletín de peligro de aludes Ribagorçana - Vall Fosca Del 29/04/2026 al 30/04/2026

(Válido fuera pistas de esquí y zonas no controladas)

LIMITADO (2) por encima de 2.200 m, DÉBIL (1) por debajo

Situación primaria

Nieve húmeda

Distribución

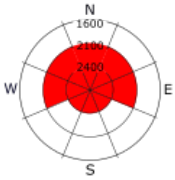

Tamaño

Origen

Tendencia

Situación secundaria

Deslizamientos basales

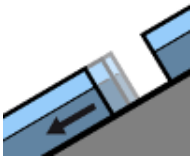

Distribución

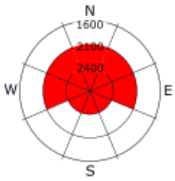

Tamaño

Origen

Tendencia

Estado del manto nivoso

En las próximas jornadas no se espera rehielo matinal con el aumento de la nubosidad y la humedad, y la continuidad de temperaturas elevadas. El manto se muestra húmedo en todo su grosor, ablandado superficialmente y presencia interna de algunas costras y capas todavía endurecidas.

Es posible actividad de aludes, tanto de nieve húmeda como de deslizamientos basales, a cualquier hora del día pero más probable a partir de mediodía en que los chubascos serán más probables y extensos, por encima de unos 2.200 m, en cualquier orientación. Los deslizamientos podrán desencadenarse sobre superficies lisas herbosas o rocosas, y alcanzar tamaño medio. Hay que evitar los puntos donde se observen grietas en el manto.

La caída de bolas y los aludes de nieve húmeda podrán afectar sobre todo vertientes de fuerte inclinación y serán por lo general de tamaño pequeño o medio.

Distribución del manto nivoso

Hay nieve por encima de unos 2.000 m en N, de forma más continua por encima de unos 2.100 m, y por encima de 2.300-2.400 m en S, a veces discontinua hasta las cumbres, y más continua en cubetas. Los grosores son irregulares pero están alrededor de 50-60 cm de media a unos 2.500 m.

Tendencia para las próximas 48-72h

Las condiciones de estabilidad del manto no experimentarán demasiados cambios. Evolución del peligro: ESTACIONARIO.

El próximo boletín será emitido el día 2026-04-30

5 MUY FUERTE	4 FUERTE	3 NOTABLE	2 LIMITADO	1 DÉBIL

EAWS EUROPEAN AVALANCHE WARNING SERVICES

ICGC Institut Cartogràfic i Geològic de Catalunya

Servei Meteorològic de Catalunya

Boletín de peligro de aludes Pallaresa
Del 29/04/2026 al 30/04/2026

(Válido fuera pistas de esquí y zonas no controladas)

LIMITADO (2) por encima de 2.200 m, DÉBIL (1) por debajo

Situación primaria

Nieve húmeda

Distribución

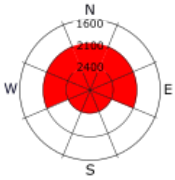

Tamaño

Origen

Tendencia

Situación secundaria

Deslizamientos basales

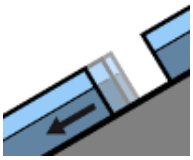

Distribución

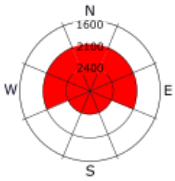

Tamaño

Origen

Tendencia

Estado del manto nivoso

En las próximas jornadas no se espera rehielo matinal con el aumento de la nubosidad y la humedad, y la continuidad de temperaturas elevadas. El manto se muestra húmedo en todo su grosor, ablandado superficialmente y presencia interna de algunas costras y capas todavía endurecidas.

Es posible actividad de aludes, tanto de nieve húmeda como de deslizamientos basales, a cualquier hora del día, pero más probable a partir de mediodía en que los chubascos serán más probables y extensos, por encima de unos 2.200 m, en cualquier orientación. Los deslizamientos podrán desencadenarse sobre superficies lisas herbosas o rocosas, y alcanzar tamaño medio. Hay que evitar los puntos donde se observen grietas en el manto.

La caída de bolas y los aludes de nieve húmeda podrán afectar sobre todo vertientes de fuerte inclinación y serán por lo general de tamaño pequeño o medio.

Distribución del manto nivoso

Hay nieve por encima de unos 2.000 m en N, de forma más continua por encima de unos 2.100 m, y por encima de 2.300-2.400 m en S, a veces discontinua hasta las cumbres, y más continua en cubetas. El manto se presenta a menudo discontinuo y con espesores irregulares y variables, retrocediendo progresivamente en espesor y extensión.

Tendencia para las próximas 48-72h

Las condiciones de estabilidad del manto no experimentarán demasiados cambios. Evolución del peligro: ESTACIONARIO.

El próximo boletín será emitido el día 2026-04-30

5 MUY FUERTE	4 FUERTE	3 NOTABLE	2 LIMITADO	1 DÉBIL

EAWS EUROPEAN AVALANCHE WARNING SERVICES

ICGC Institut Cartogràfic i Geològic de Catalunya

meteo.cat Servei Meteorològic de Catalunya

Boletín de peligro de aludes Perafita-Puigpedrós Del 29/04/2026 al 30/04/2026

(Válido fuera pistas de esquí y zonas no controladas)

LIMITADO (2) por encima de 2.300 m, DÉBIL (1) por debajo

Situación primaria

Nieve húmeda

Distribución

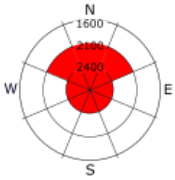

Tamaño

Origen

Tendencia

Situación secundaria

Deslizamientos basales

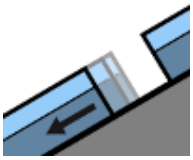

Distribución

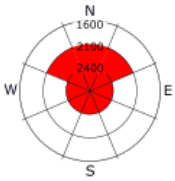

Tamaño

Origen

Tendencia

Estado del manto nivoso

El manto permanece húmedo e incluso podría aumentar su densidad con el incremento del humedecimiento que se espera para el jueves debido al aumento de la nubosidad, la humedad y las lluvias previstas. No se espera rehielo la madrugada del jueves. Con estas condiciones, es probable la actividad de aludes de nieve húmeda y deslizamientos basales, por encima de unos 2.300 m, en cualquier orientación y hora del día, pero más probables en momentos de chaparrón. Los deslizamientos podrán desencadenarse sobre laderas herbosas, o rocosas de superficie lisa, y alcanzar tamaño mediano. En caso de aparición de grietas en el manto es recomendable evitar estos puntos. Los aludes de nieve húmeda podrán afectar sobre todo vertientes de fuerte inclinación y puntos bajo resaltes rocosos o árboles. Los aludes serán por lo general de tamaño pequeño, y localmente alcanzar hasta tamaño 2, mediano.

Distribución del manto nivoso

Hay nieve esquiable en umbrías por encima de unos 2.200 m en orientaciones N y presencia de nieve en S por encima de unos 2.300 m de forma discontinua. El manto se presenta a menudo discontinuo, sobre todo en S, y con espesores irregulares, retrocediendo progresivamente en espesor y extensión.

Tendencia para las próximas 48-72h

Las condiciones de estabilidad del manto no experimentarán demasiados cambios. Evolución del peligro: ESTACIONARIO.

El próximo boletín será emitido el día 2026-04-30

5 MUY FUERTE	4 FUERTE	3 NOTABLE	2 LIMITADO	1 DÉBIL

EAWS EUROPEAN AVALANCHE WARNING SERVICES

ICGC Institut Cartogràfic i Geològic de Catalunya

Servei Meteorològic de Catalunya

Boletín de peligro de aludes Vessant Nord Cadí-Moixeró Del 29/04/2026 al 30/04/2026

(Válido fuera pistas de esquí y zonas no controladas)

LIMITADO (2) por encima de 2.200 m, DÉBIL (1) por debajo

Situación primaria

Nieve húmeda

Distribución

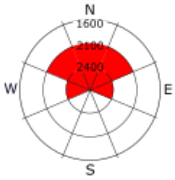

Tamaño

Origen

Tendencia

Estado del manto nivoso

El aumento de la nubosidad, humedad y lluvias previstas podrán humedecer aún más un manto que ya se encuentra húmedo en su totalidad. En los próximos días no se espera rehielo nocturno. Con estas condiciones, serán posibles aludes naturales de nieve húmeda en cualquier orientación, más probables en momentos de chaparrón pero sin descartarse en cualquier otro momento del día. Los aludes podrán desencadenarse sobre todo en las canales y laderas de fuerte pendiente y bajo resaltes rocosos o árboles. Serán por lo general aludes de pequeño tamaño, y localmente podrán alcanzar hasta tamaño 2, mediano. Las canales, donde el manto nivoso tiene más grosor, pueden convertirse en los sectores más peligrosos, así como el terreno trampa donde un alud pequeño podría llegar a enterrarnos.

Distribución del manto nivoso

Hay nieve por encima de unos 2.000 m en N y de unos 2.200 m en Sur, de forma muy escasa y discontinua. Los espesores rodean, a umbrías, los 80-100 cm a unos 2.300 m. Estos valores están por encima de los normales para la época.

Tendencia para las próximas 48-72h

Las condiciones de estabilidad del manto no experimentarán demasiados cambios. Evolución del peligro: ESTACIONARIO.

El próximo boletín será emitido el día 2026-04-30

5 MUY FUERTE	4 FUERTE	3 NOTABLE	2 LIMITADO	1 DÉBIL

EAWS EUROPEAN AVALANCHE WARNING SERVICES

ICGC Institut Cartogràfic i Geològic de Catalunya

Servei Meteorològic de Catalunya

Boletín de peligro de aludes Prepirineu
Del 29/04/2026 al 30/04/2026

(Válido fuera pistas de esquí y zonas no controladas)

DÉBIL (1)

Situación primaria

Nieve húmeda

Distribución

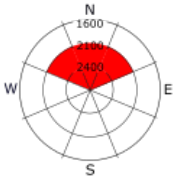

Tamaño

Origen

Tendencia

Estado del manto nivoso

El manto nivoso se ha ido reduciendo mucho en las últimas semanas, tanto en extensión como en grosor, y va quedando restringido a las cotas más altas del sector ya canales y pequeñas cuencas. En los próximos días, con el aumento de la nubosidad y humedad no se espera rehielo matinal. El manto se presenta húmedo en su totalidad y la actividad de aludes se restringe a aludes de nieve húmeda. Con las condiciones de humedecimiento del manto previstas desde primera hora del día y sin rehielo matinal los aludes pueden producirse a cualquier hora del día pero más probables a partir de mediodía en momentos de chaparrón, afectando cualquier orientación, sobre todo en vertientes de fuerte inclinación y bajo resaltes rocosos o árboles. Los aludes serán por lo general en forma de purgas o de pequeño tamaño.

Distribución del manto nivoso

En orientación S el manto es discontinuo y escaso hasta las cimas, en N hay presencia de nieve por encima de unos 2.100 m. El manto se presenta a menudo discontinuo y con espesores irregulares, retrocediendo progresivamente en espesor y extensión.

Tendencia para las próximas 48-72h

Las condiciones de estabilidad del manto no experimentarán demasiados cambios. Evolución del peligro: ESTACIONARIO.

El próximo boletín será emitido el día 2026-04-30

5 MUY FUERTE	4 FUERTE	3 NOTABLE	2 LIMITADO	1 DÉBIL

EAWS EUROPEAN AVALANCHE WARNING SERVICES

ICGC Institut Cartogràfic i Geològic de Catalunya

Servei Meteorològic de Catalunya

Boletín de peligro de aludes Ter-Freser
Del 29/04/2026 al 30/04/2026

(Válido fuera pistas de esquí y zonas no controladas)

LIMITADO (2) por encima de 2.300 m, DÉBIL (1) por debajo

Situación primaria

Deslizamientos basales

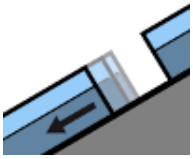

Distribución

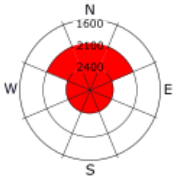

Tamaño

Origen

Tendencia

Situación secundaria

Nieve húmeda

Distribución

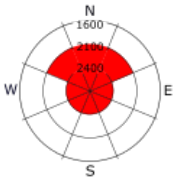

Tamaño

Origen

Tendencia

Estado del manto nivoso

El manto permanece húmedo e incluso podría aumentar su densidad con el incremento del humedecimiento que se espera para el jueves debido al aumento de la nubosidad, la humedad y las lluvias previstas. No se espera rehielo la madrugada del jueves. Con estas condiciones, es probable la actividad de aludes de nieve húmeda y deslizamientos basales, por encima de unos 2.300 m, en cualquier orientación y hora del día, pero más probables en momentos de chaparrón. Los deslizamientos podrán desencadenarse sobre laderas herbosas, o rocosas de superficie lisa, y alcanzar tamaño medio. En caso de aparición de grietas en el manto es recomendable evitar estos puntos. Los aludes de nieve húmeda podrán afectar sobre todo vertientes de fuerte inclinación y puntos bajo resaltes rocosos o árboles. Los aludes serán por lo general de tamaño pequeño, y localmente alcanzar hasta tamaño 2, mediano.

Distribución del manto nivoso

Hay nieve por encima de unos 2.000 m en N y de unos 2.200 m en S, de forma discontinua. El manto se presenta a menudo discontinuo y con espesores irregulares, retrocediendo progresivamente en espesor y extensión.

Tendencia para las próximas 48-72h

Las condiciones de estabilidad del manto no experimentarán demasiados cambios. Evolución del peligro: ESTACIONARIO.

El próximo boletín será emitido el día 2026-04-30

5 MUY FUERTE	4 FUERTE	3 NOTABLE	2 LIMITADO	1 DÉBIL

EAWS EUROPEAN AVALANCHE WARNING SERVICES