MINISTERO DELLA DIFESA

meteomont Servizio Nazionale di previsione neve e valanghe

EAWS EUROPEAN AVALANCHE WARNING SERVICES

CARABINIERI

In collaborazione con: arpav

# DOLOMITI MERIDIONALI

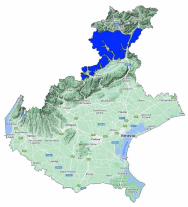

Bollettino Valanghe N. 421/2026 del 29/04/2026 ore 14.00
Validità 48 ore prossima emissione 30/04/2026

**A cura del Servizio METEOMONT dell'ARMA dei CARABINIERI**
**In collaborazione con Servizio Meteorologico dell'Aeronautica militare**

## SITUAZIONE alle 14:00 del 29/04/2026

**SITUAZIONE TIPO: strato debole persistente basale.**




**SITUAZIONE TIPO: pioggia su neve.**

| Quota neve (mslm) | Nord | Sud |
|---|---|---|
| | 2000 - 2300 | 2400 - 2800 |

| Altezza Neve (cm) | Neve al suolo | Neve Fresca | Quota (mslm) |
|---|---|---|---|
| | 89 | 0 | 2580 |
| | 015 | 000 | 2047 |

**VALANGHE OSSERVATE: Nessuna valanga.**

## PREVISIONI 30/04/2026

## GRADO DI PERICOLO: MODERATO 2

## SITUAZIONE TIPO: situazione primaverile.

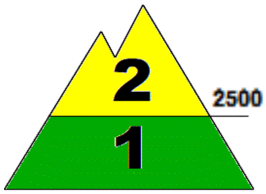


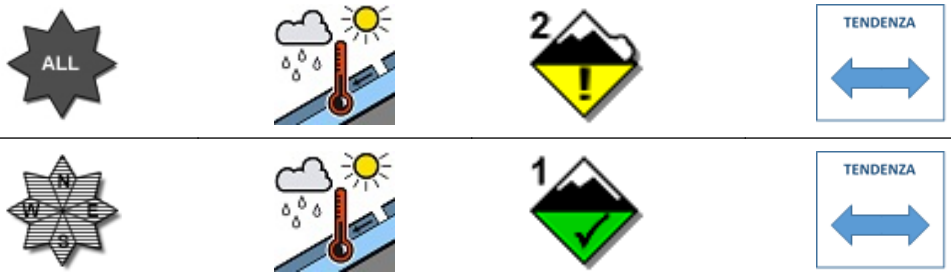


## SITUAZIONE TIPO: situazione primaverile.

**MANTO NEVOSO: La stabilità del manto nevoso è scarsa su alcuni punti (aree) per tutte le esposizioni al di sopra di 2500 mslm, possibili valanghe di dimensioni medie.**
**La stabilità del manto nevoso è discreta su pochi punti (aree) per isolati pendii al di sotto di 2500 mslm, possibili valanghe di dimensioni piccole.**

## AVVERTENZE

Il rialzo termico diurno richiede un'attenta valutazione temporale dell'escursione che eviti l'attraversamento di pendii ripidi nelle ore più calde della giornata.

## SCALA EUROPEA DEL GRADO DI PERICOLO VALANGHE

5 - MOLTO FORTE | 4 - FORTE | 3 - MARCATO | 2 - MODERATO | 1 - DEBOLE | NO NEVE | NO INFO

## LEGENDA PROBLEMA

NEVE FRESCA | LASTRONI DA VENTO | STRATI DEBOLI PERSISTENTI | NEVE BAGNATA | SLITTAMENTO | CORNICI | NESSUN PROBLEMA VALANGHIVO EVIDENTE | NO_INFO

**Bollettino realizzato su scala sinottica-regionale (standard EAWS). La sua valutazione non può escludere in alcun modo la necessità di una seria e capace valutazione locale del pericolo (singolo pendio) che può essere anche sensibilmente diverso. Le previsioni meteorologiche sono relative all'orario UTC (per l'Italia +1 in inverno e +2 in estate).**

MINISTERO DELLA DIFESA

meteomont
Servizio Nazionale di previsione neve e valanghe

EAWS EUROPEAN AVALANCHE WARNING SERVICES

CARABINIERI

In collaborazione con: arpav

# DOLOMITI MERIDIONALI

## PREVISIONE METEO

| Quota | | 30/04/2026 h6:00 | 30/04/2026 h12:00 | 30/04/2026 h18:00 |
|---|---|---|---|---|
| 1000 | Venti | 00 Calma | 02 Nodi da Sud | 02 Nodi da S-Ovest |
| | Temperature | +04 °C | +06 °C | +05 °C |
| | Temp.percepita | 4 °C | 6 °C | 5 °C |
| 2000 | Venti | 02 nodi da N-Ovest | 02 Nodi da Nord | 03 Nodi da N-Est |
| | Temperature | +00 °C | -01 °C | +01 °C |
| | Temp.percepita | 0 °C | -1 °C | -1 °C |
| 3000 | Venti | 07 Nodi da Nord | 05 Nodi da N-Est | 10 Nodi da Nord |
| | Temperature | -04 °C | -03 °C | -03 °C |
| | Temp.percepita | -9 °C | -7 °C | -9 °C |
| Zero termico | | 1800-2000 m. | 1700-1900 m. | 2100-2300 m. |
| Fenomeno | | — | — | — |
| Stato del cielo | | | | |

## LEGENDA FENOMENI

— Assenza Fenomeni · Nebbia · Foschia · Pioggia debole · Pioggia moderata · Pioggia forte · Temporali

Nevicata debole · Nevicata moderata · Nevicata forte

## STATO DEL CIELO

Sereno · Poco nuvoloso · Nuvoloso · Molto nuvoloso · Coperto

## Parametri meteonivometrici registrati presso i campi di rilevamento il 29/04/2026.

| Località | Comune | Quota (m.s.l.m.) | Altezza neve (cm) | Neve caduta nelle 24 ore (cm) | Temp. Min (°C) | Temp. Max (°C) | Condizioni del tempo |
|---|---|---|---|---|---|---|---|
| PASSO VALLES * | Falcade (BL) | 2047 | 15 | 0 | N.P. | N.P. | Pioggia debole intermittente |

(*) Rilievi fuori campo

**L'INFORMAZIONE E' PREVENZIONE - LEGGI L'ATTUALE GRADO DI PERICOLO VALANGHE!**

**IL CAPO DEL CENTRO NAZIONALE METEOMONT**
**(Ten. Col. RFI Emanuela Gini)**
**FIRMA AUTOGRAFA OMESSA AI SENSI**
**DELL'ART.3 DEL D.LGS N.39/1993**