# Bulletin d'estimation du risque d'avalanche
(valable en dehors des pistes balisées et ouvertes)

# MASSIF : Oisans

Rédigé le mercredi 29 avril 2026 à 15h

## Estimation des risques pour le : JEUDI 30 AVRIL

**RARES AVALANCHES HUMIDE EN FACES NORD, PARFOIS VOLUMINEUSE SOUS 2800M ENVIRON ?**

2

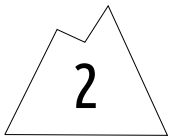


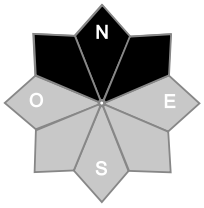


Rares, humidifiées..

Indices de risque : 5 très fort - 4 fort - 3 marqué - 2 limité - 1 faible -- En noir : les pentes les plus dangereuses

Indice de risque limité.

**Départs spontanés :** En altitude quelques coulées de surface de neige récente. En faces Nord, rare avalanche plus volumineuse, parfois au terrain (sous 2700/2900m environ) ?

**Déclenchements provoqués :** RAS ou coulées humides superficielles sous les skis en pente raide.

## Stabilité du manteau neigeux

**Situation avalancheuse typique :** neige humide

Mercredi soir, des averses locales donnent quelques cm de neige au-dessus de 2700m. Guère de regel jeudi matin sous cette altitude...
Jeudi l'humidification gagne localement en faces Nord, risque d'avalanche de fond non exclu plus bas que 2700/2900m environ ?

**Départs spontanés :** Avec un saupoudrage possible sur les hauts de l'Oisans, possibles coulées/escargots de surface.
Jeudi suite à un regel faible ou absent, l'humidification s'accentue et pourrait déstabiliser certaines faces Nord raides : On n'exclut pas une nouvelle coulée ou avalanche plus volumineuse, parfois au terrain...
Dans de rares cas, sous 2800m, une cassure large/linéaire est possible (présence de vieille sous couche plus fragile)
En faces plus ensoleillées, neige plus dense, de névé, stable.
**Déclenchements provoqués :** Peu probables, ou vers les sommets un risque de coulée superficielle sous les skis ?

## Qualité de la neige

**Qualification de l'enneigement :** La fonte s'est récemment accélérée. L'enneigement devient déficitaire sur le massif, avec un aspect presque de fin de saison. Les hauts sommets et glaciers sont anormalement "secs"..

**Limites skiables :** Vers 1800/2000m en Nord à 2300/2600m en versants ensoleillés.

**Qualité de la neige jeudi :** Quasiment pas de regel nocturne, sous 2500/2700m notamment.
Un peu de neige récente possible vers les hauts sommets, froide seulement en Nord raide au dessus de 3000/3200m.
Neige salie/colorée avec pas mal de reliefs.
Neige très humide en journée, glisse médiocre à faible...

## Aperçu météo pour le jeudi 30 avril

| | nuit | matin | après-midi | soir |
|---|---|---|---|---|
| | | | | |

Ambiance assez douce, fréquemment nuageuse. Quelques averses l'après-midi, parfois soutenues, orageuses ? Limite de la neige vers 2700m.

| | | | | |
|---|---|---|---|---|
| **Pluie-Neige** | 2 700 m | | | |
| **Iso 0 °C** | 3 000 m | 3 000 m | 3 000 m | 3 000 m |
| **Vent 2500 m** | ↑ 5 km/h | ↖ 10 km/h | → 15 km/h | ← 5 km/h |
| **Vent 3500 m** | ↙ 5 km/h | ↻ 10 km/h | ↗ 15 km/h | ← 10 km/h |

## Épaisseur de neige hors-piste

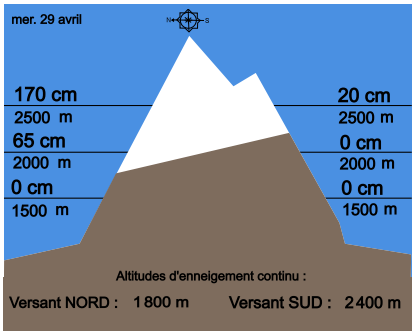


## Précipitations à 1800 m

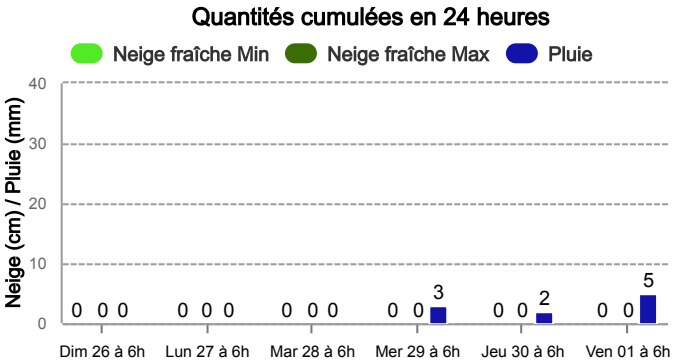


## Tendance du vendredi 01 mai

2

**Indice de risque limité**

Pas d'évolution vendredi, risque d'avalanche stationnaire ou en légère baisse. La fonte se poursuit, saupoudrage local vers les hauts sommets...

Pour consulter la vigilance en cours, veuillez vous rendre sur le site https://vigilance.meteofrance.fr/fr

Météo-France - 73 avenue de Paris, 94165 Saint-Mandé cedex - Contact : contact@meteo.fr

Rédigé par Météo-France avec la contribution des observateurs du réseau nivo-météorologiques. Partenariat : ANMSM (Maires de Stations de Montagne), DSF (Domaines Skiables de France), ADSP (Directeurs de Pistes et de la Sécurité des Stations de Sports d'Hiver) et autres acteurs de la montagne.

Bulletin neige & avalanches par téléphone au
0 892 68 10 20 Service 0,35 € / min + prix appel

RÉPUBLIQUE FRANÇAISE
*Liberté Égalité Fraternité*

METEO FRANCE
À VOS CÔTÉS, DANS UN CLIMAT QUI CHANGE

# Bulletin d'estimation du risque d'avalanche
## (valable en dehors des pistes balisées et ouvertes)

# MASSIF : Oisans

Rédigé le mercredi 29 avril 2026 à 15h

## Conditions nivo-météo des 7 derniers jours

| | jeu. 23/04 | | | | ven. 24/04 | | | | sam. 25/04 | | | | dim. 26/04 | | | | lun. 27/04 | | | | mar. 28/04 | | | | mer. 29/04 | | | |
|---|---|---|---|---|---|---|---|---|---|---|---|---|---|---|---|---|---|---|---|---|---|---|---|---|---|---|---|---|
| | 03h | 09h | 15h | 21h | 03h | 09h | 15h | 21h | 03h | 09h | 15h | 21h | 03h | 09h | 15h | 21h | 03h | 09h | 15h | 21h | 03h | 09h | 15h | 21h | 03h | 09h | 15h | 21h |
| Météo | | | | | | | | | | | | | | | | | | | | | | | | | | | | |
| Vent (km/h) | 15 | 20 | 15 | 10 | 10 | 5 | 10 | 10 | 10 | 15 | 15 | 15 | 15 | 10 | 10 | 10 | 5 | 5 | 15 | 10 | 15 | 20 | 25 | 20 | 15 | 10 | 15 | 10 |
| à 3500m | | | | | | | | | | | | | | | | | | | | | | | | | | | | |
| Vent (km/h) | 10 | 10 | 10 | 10 | 5 | 5 | 10 | 5 | 5 | 10 | 10 | 10 | 10 | 5 | 5 | 5 | 5 | 5 | 10 | 5 | 5 | 15 | 20 | 15 | 10 | 10 | 15 | 5 |
| à 2500m | | | | | | | | | | | | | | | | | | | | | | | | | | | | |

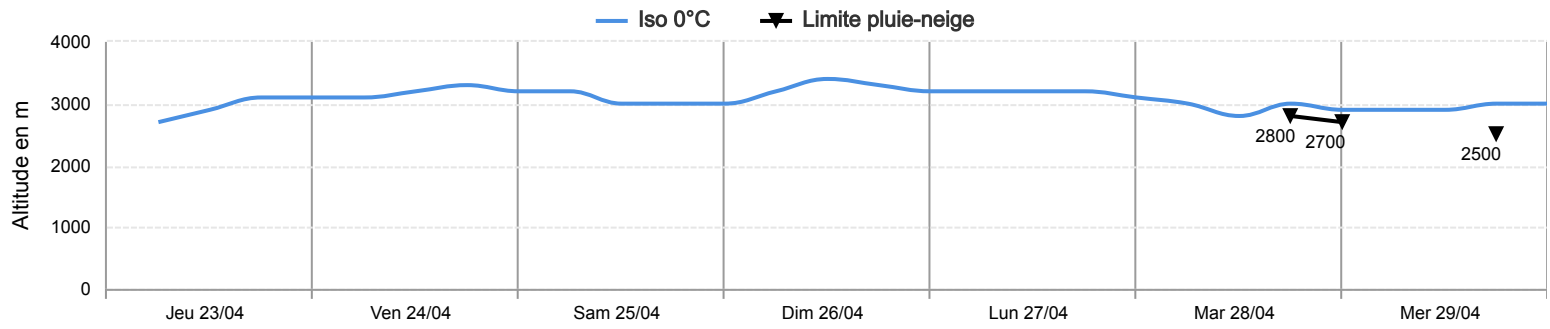


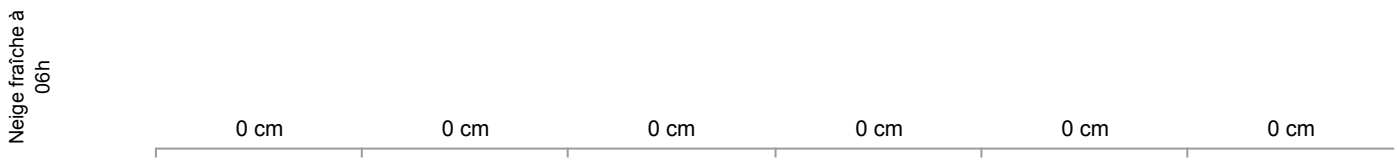


| Risque d'avalanche | jeu. 23/04 | ven. 24/04 | sam. 25/04 | dim. 26/04 | lun. 27/04 | mar. 28/04 | mer. 29/04 |
|---|---|---|---|---|---|---|---|
| | 2 | 2 | 2 | 2 | 2 | 2 | 2 |

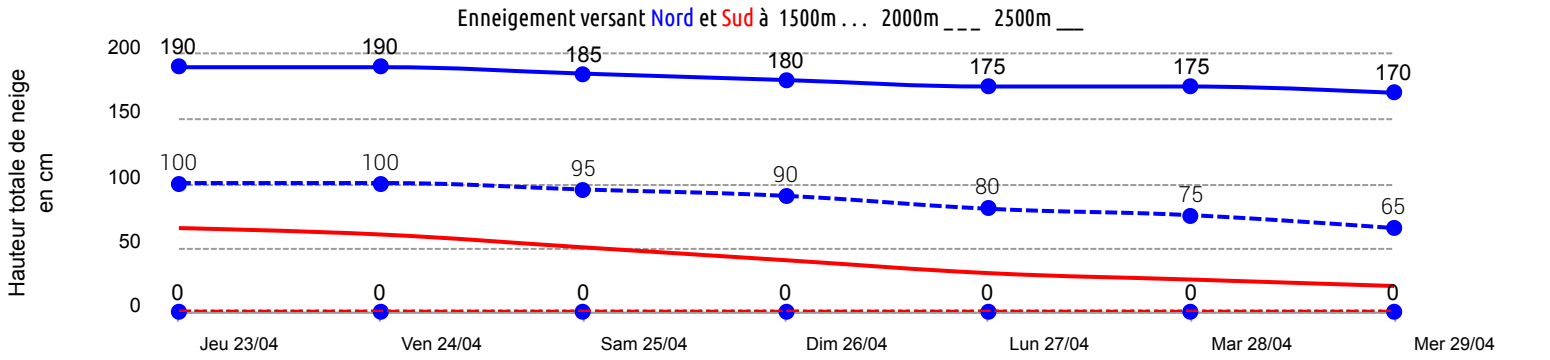


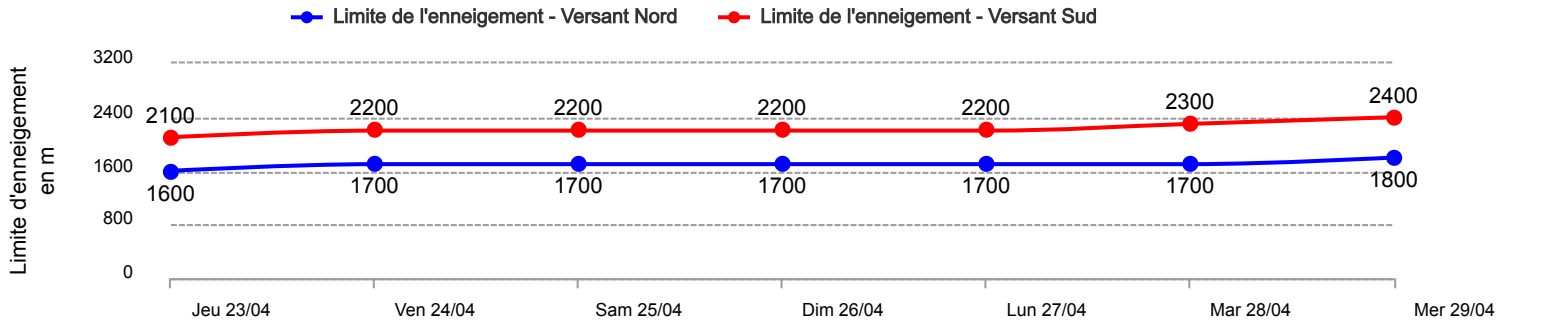


Pour consulter la vigilance en cours, veuillez vous rendre sur le site https://vigilance.meteofrance.fr/fr


Météo-France - 73 avenue de Paris, 94165 Saint-Mandé cedex - Contact : contact@meteo.fr


Bulletin neige & avalanches par téléphone au
0 892 68 10 20 Service 0,35 € / min + prix appel


Rédigé par Météo-France avec la contribution des observateurs du réseau nivo-météorologiques. Partenariat : ANMSM (Maires de Stations de Montagne), DSF (Domaines Skiables de France), ADSP (Directeurs de Pistes et de la Sécurité des Stations de Sports d'Hiver) et autres acteurs de la montagne.