Bulletin d'estimation du risque d'avalanche
(valable en dehors des pistes balisées et ouvertes)

MASSIF : Vercors

Rédigé le mercredi 29 avril 2026 à 15h

Estimation des risques pour le : JEUDI 30 AVRIL

NEIGE DE NEVE, STABLES..

1

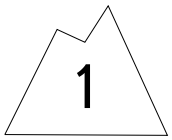

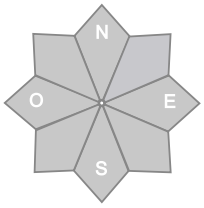

Névés...

Indice de risque faible.

Départs spontanés : Peu probables. Grands névés humides denses, stables

Déclenchements provoqués : Peu probables.

Indices de risque : 5 très fort - 4 fort - 3 marqué - 2 limité - 1 faible -- En noir : les pentes les plus dangereuses

Stabilité du manteau neigeux

Situation avalancheuse typique : pas de situation prédominante

De moins en moins de neige sur le massif, la fin de saison approche.
Départs spontanés : Peu probables, ou rare coulée humide l'après-midi, le soir ?.
Déclenchements provoqués : Peu probables.

Qualité de la neige

Qualification de l'enneigement : L'enneigement s'est fortement réduit depuis début avril et devient franchement déficitaire pour la saison. Il ne reste que de grand névés vers les sommets, surtout en Nord d'altitude dès 1700/1800m environ...
Qualité de la neige jeudi : Pas de regel nocturne a priori. Neige humide dense avec des reliefs, des surfaces salies.

Aperçu météo pour le jeudi 30 avril

	nuit	matin	après-midi	soir

Ambiance douce, assez nuageuse. Quelques averses l'après-midi, parfois soutenues, orageuses ?

Pluie-Neige	2 700 m			
Iso 0 °C	3 000 m	3 000 m	3 000 m	3 000 m
Vent 1500 m	↓ 10 km/h	↗ 15 km/h	→ 20 km/h	↑ 10 km/h
Vent 2000 m	→ 15 km/h	→ 20 km/h	→ 25 km/h	↗ 10 km/h

Épaisseur de neige hors-piste

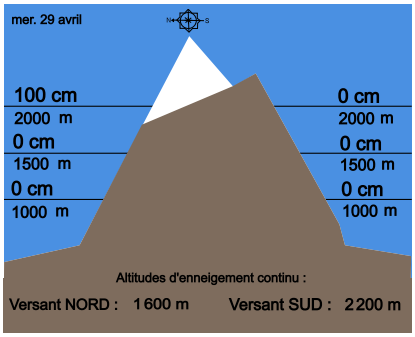

Précipitations à 1800 m

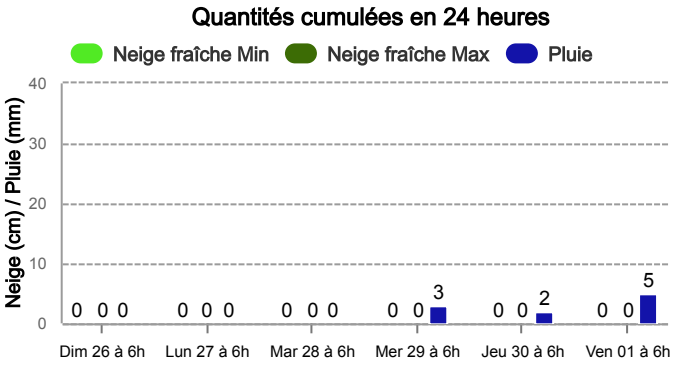

Tendance du vendredi 01 mai

1

Indice de risque faible

Pas d'évolution vendredi, la fonte se poursuit...

Pour consulter la vigilance en cours, veuillez vous rendre sur le site https://vigilance.meteofrance.fr/fr

Météo-France - 73 avenue de Paris, 94165 Saint-Mandé cedex - Contact : contact@meteo.fr

Rédigé par Météo-France avec la contribution des observateurs du réseau nivo-météorologiques. Partenariat : ANMSM (Maires de Stations de Montagne), DSF (Domaines Skiables de France), ADSP (Directeurs de Pistes et de la Sécurité des Stations de Sports d'Hiver) et autres acteurs de la montagne.

Bulletin neige & avalanches par téléphone au
0 892 68 10 20 Service 0,35 € / min + prix appel

Bulletin d'estimation du risque d'avalanche

(valable en dehors des pistes balisées et ouvertes)

MASSIF : Vercors

Rédigé le mercredi 29 avril 2026 à 15h

Conditions nivo-météo des 7 derniers jours

	jeu. 23/04				ven. 24/04				sam. 25/04				dim. 26/04				lun. 27/04				mar. 28/04				mer. 29/04			
	03h	09h	15h	21h	03h	09h	15h	21h	03h	09h	15h	21h	03h	09h	15h	21h	03h	09h	15h	21h	03h	09h	15h	21h	03h	09h	15h	21h
Météo																												
Vent (km/h)	20	20	20	10	15	20	20	10	15	25	30	25	25	30	25	15	15	20	20	10	15	25	25	15	20	25	25	10
à 2000m																												
Vent (km/h)	10	15	20	10	10	10	20	10	10	20	25	20	20	25	20	10	10	15	15	5	10	20	20	15	15	20	20	10
à 1500m																												

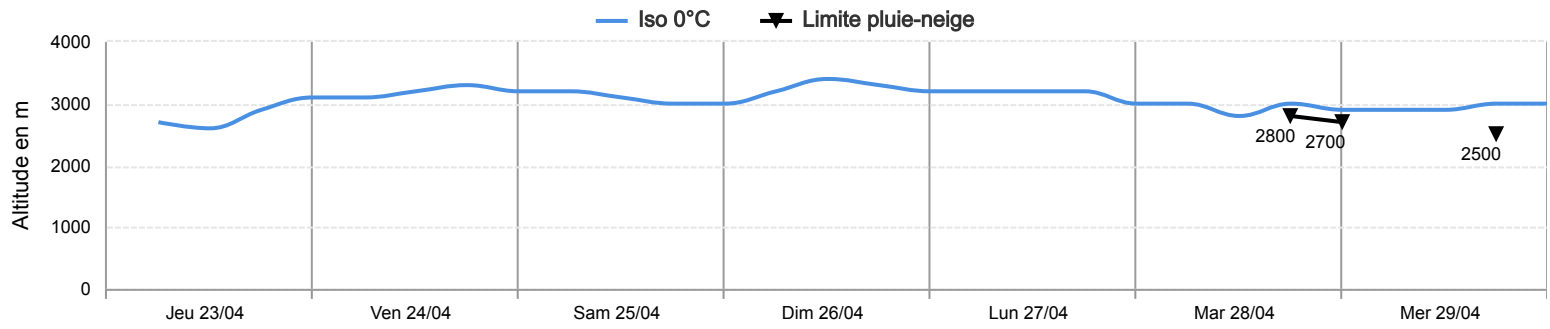

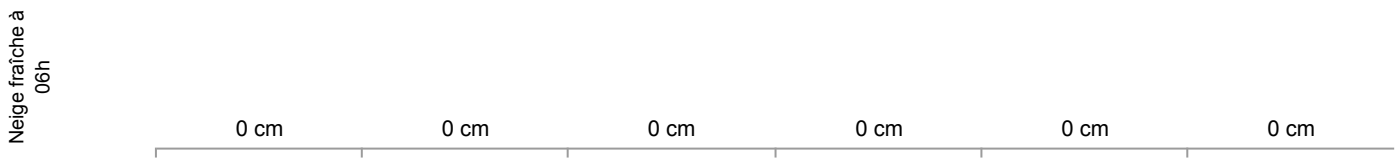

Risque d'avalanche	jeu. 23/04	ven. 24/04	sam. 25/04	dim. 26/04	lun. 27/04	mar. 28/04	mer. 29/04
	1	1	1	1	1	1	1

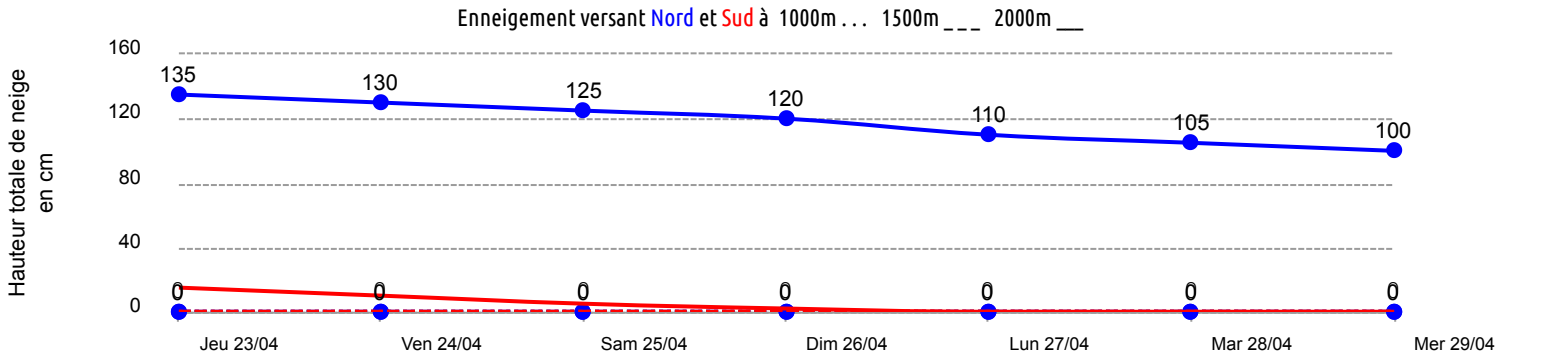

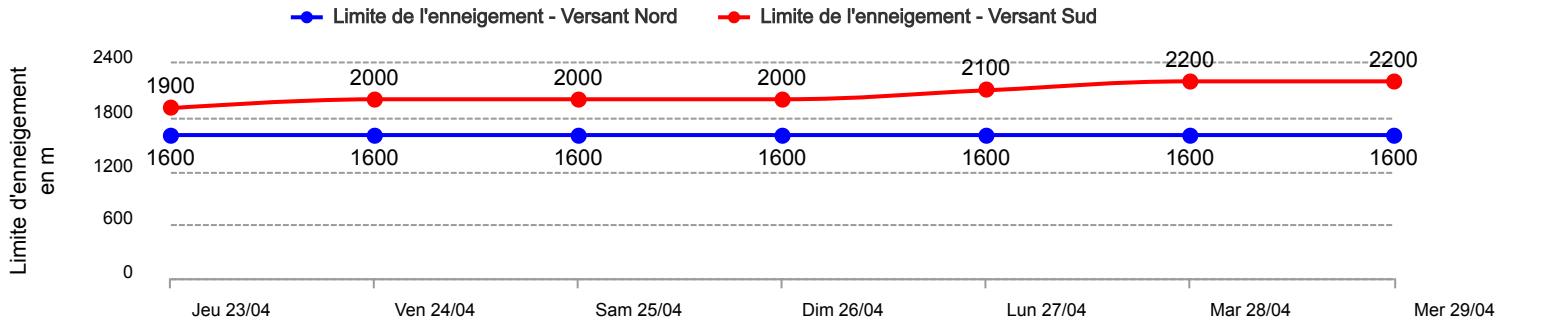

Pour consulter la vigilance en cours, veuillez vous rendre sur le site https://vigilance.meteofrance.fr/fr

Météo-France - 73 avenue de Paris, 94165 Saint-Mandé cedex - Contact : contact@meteo.fr

Bulletin neige & avalanches par téléphone au

0 892 68 10 20 Service 0,35 € / min + prix appel

Rédigé par Météo-France avec la contribution des observateurs du réseau nivo-météorologiques. Partenariat : ANMSM (Maires de Stations de Montagne), DSF (Domaines Skiables de France), ADSP (Directeurs de Pistes et de la Sécurité des Stations de Sports d'Hiver) et autres acteurs de la montagne.