Bulletin d'estimation du risque d'avalanche

(valable en dehors des pistes balisées et ouvertes)

MASSIF : Aspe Ossau

Rédigé le mercredi 29 avril 2026 à 16h

Estimation des risques pour le : JEUDI 30 AVRIL

MANTEAU NEIGEUX TRÈS HUMIDE DÈS LE MATIN APRÈS UNE NUIT NUAGEUSE, VENTÉE DE SUD

2

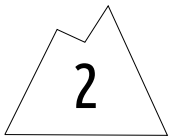

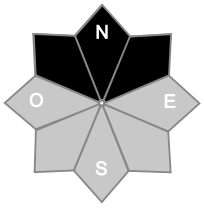

Indice de risque limité.

Départs spontanés : En neige humide, avalanches de fond moyennes à rarement grandes.

Déclenchements provoqués : En neige humide seulement.

Indices de risque : 5 très fort - 4 fort - 3 marqué - 2 limité - 1 faible -- En noir : les pentes les plus dangereuses

Stabilité du manteau neigeux

Situation avalancheuse typique : neige humide avalanches de fond

Départs spontanés :
Activité attendue rapidement en matinée, sous forme de départs ponctuels de neige humide au gré des éclaircies, en général de taille petite à moyenne. De rares grandes avalanches sont possibles par départ d'une avalanche de fond, en général depuis une fissure déjà ouverte. Leur chronologie de départ est moins liée à l'ensoleillement, les zones de départs se situent en général en secteurs nord-est à nord-ouest où sont les plus grosses épaisseurs de neige, au-dessus de 2200/2300 m.

Déclenchements provoqués : en neige humide seulement.
Le passage d'un skieur ou d'un randonneur dans la neige très humide peut favoriser un départ ponctuel en général de petite taille, parfois moyenne, et ce dès le matin avec une neige probablement molle dès le lever du jour.

Autres :
- **corniches et ponts de neige** encore en place **fragiles et peu résistants**, pouvant **céder** dès le matin **spontanément** ou sous le **poids d'une seule personne, même s'ils semblent épais.**
- les **chemins de randonnée déjà déneigés situés sous les secteurs raides d'altitude encore chargés** peuvent être **atteints pas une avalanche de fond de taille moyenne à parfois grande** dans l'après-midi.

Qualité de la neige

Enneigement : Encore correct pour la saison au-dessus de 2200 m, plutôt déficitaire plus bas, débutant encore vers 1850 m en nord et au-dessus de 2200 m en sud. Les limites de cet enneigement remontent progressivement dans la douceur ambiante.
État de la neige :
Neige humide souvent assez portante le matin, se ramollissant encore au fil de la journée, avec des enfoncements à pied dépassant 40 cm.

Aperçu météo pour le jeudi 30 avril

	nuit	matin	après-midi	soir
	Nuages en moyenne montagne en matinée, très nuageux à brouillards en fin d'après-midi, risque d'averses voire d'orages en cours après-midi, en piémont			
Pluie-Neige	2700 m	2700 m	2700 m	2700 m
Iso 0 °C	3200 m	3000 m	3000 m	3000 m
Vent 1500 m	↑ 35 km/h	↑ 25 km/h	↓ 25 km/h	↖ 20 km/h
Vent 3000 m	↑ 50 km/h	↑ 50 km/h	↗ 50 km/h	↑ 50 km/h

Épaisseur de neige hors-piste

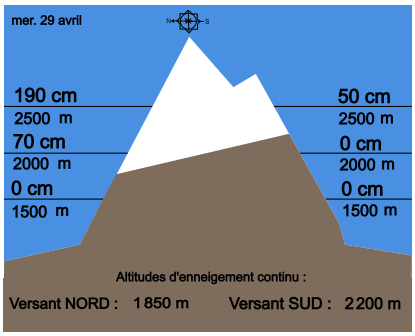

Précipitations à 1800 m

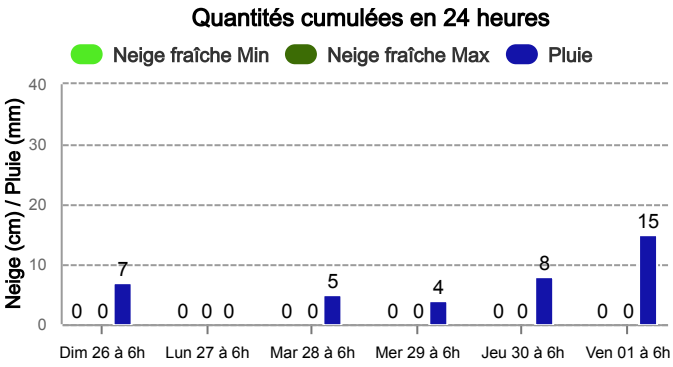

Tendance du vendredi 01 mai

2

Indice de risque limité

Neige humide

Pour consulter la vigilance en cours, veuillez vous rendre sur le site https://vigilance.meteofrance.fr/fr

Météo-France - 73 avenue de Paris, 94165 Saint-Mandé cedex - Contact : contact@meteo.fr

Bulletin neige & avalanches par téléphone au **0 892 68 10 20** Service 0,35 € / min + prix appel

Rédigé par Météo-France avec la contribution des observateurs du réseau nivo-météorologiques. Partenariat : ANMSM (Maires de Stations de Montagne), DSF (Domaines Skiables de France), ADSP (Directeurs de Pistes et de la Sécurité des Stations de Sports d'Hiver) et autres acteurs de la montagne.

RÉPUBLIQUE FRANÇAISE
Liberté Égalité Fraternité

METEO FRANCE
À VOS CÔTÉS, DANS UN CLIMAT QUI CHANGE

Bulletin d'estimation du risque d'avalanche

(valable en dehors des pistes balisées et ouvertes)

MASSIF : Aspe Ossau

Rédigé le mercredi 29 avril 2026 à 16h

Conditions nivo-météo des 7 derniers jours

	jeu. 23/04				ven. 24/04				sam. 25/04				dim. 26/04				lun. 27/04				mar. 28/04				mer. 29/04			
	03h	09h	15h	21h	03h	09h	15h	21h	03h	09h	15h	21h	03h	09h	15h	21h	03h	09h	15h	21h	03h	09h	15h	21h	03h	09h	15h	21h
Météo																												
Vent (km/h)	30	30	35	35	40	35	20	15	20	25	15	25	25	20	20	20	20	20	20	25	20	15	25	30	55	65	55	50
à 3000m	↑	↑	↑	↑	↑	↑	↗	↑	↗	↗	↘	→	↘	↗	↗	↗	→	↗	↗	↗	↑	↑	↑	↑	↑	↑	↑	↑
Vent (km/h)	15	15	20	20	25	15	10	10	10	15	5	10	5	15	10	10	10	5	2	5	10	10	20	15	35	40	35	35
à 1500m	↑	↑	↑	↖	↗	↗	↓	↑	↑	→	↻	↻	↻	↓	↓	↑	↑	↻	↻	↑	↖	↑	↑	↑	↖	↑	↑	↑

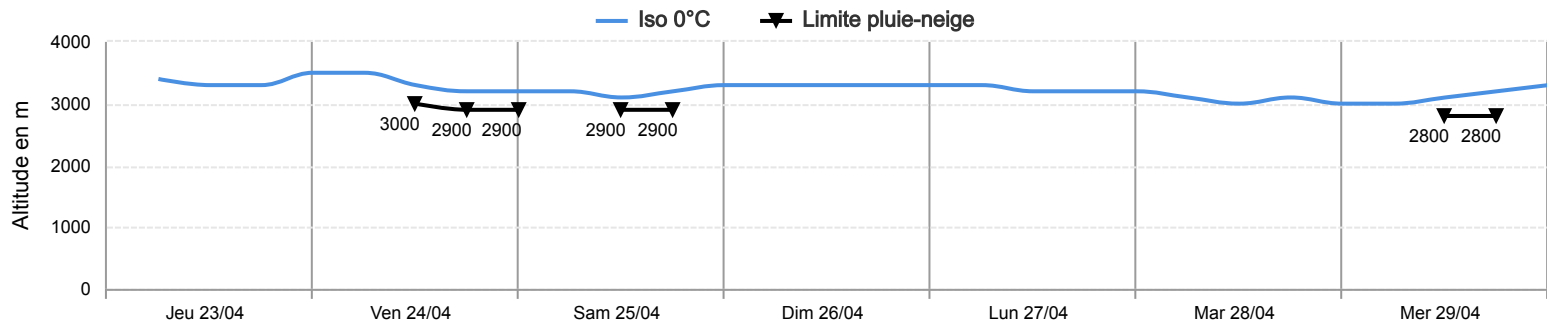

Neige fraîche à 06h

0 cm	0 cm	0 cm	0 cm	0 cm	0 cm

Risque d'avalanche	jeu. 23/04	ven. 24/04	sam. 25/04	dim. 26/04	lun. 27/04	mar. 28/04	mer. 29/04
	3	3	3	2	2	2	2

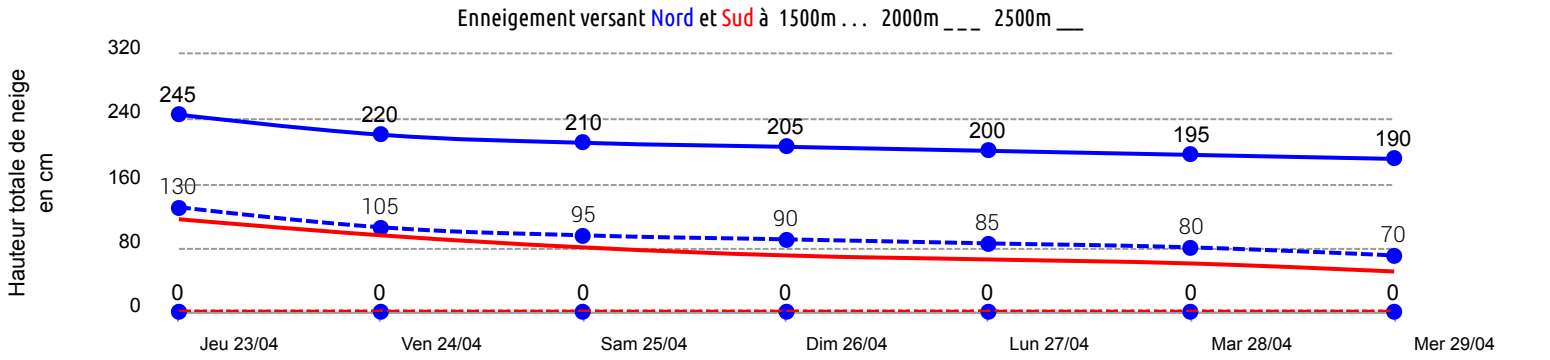

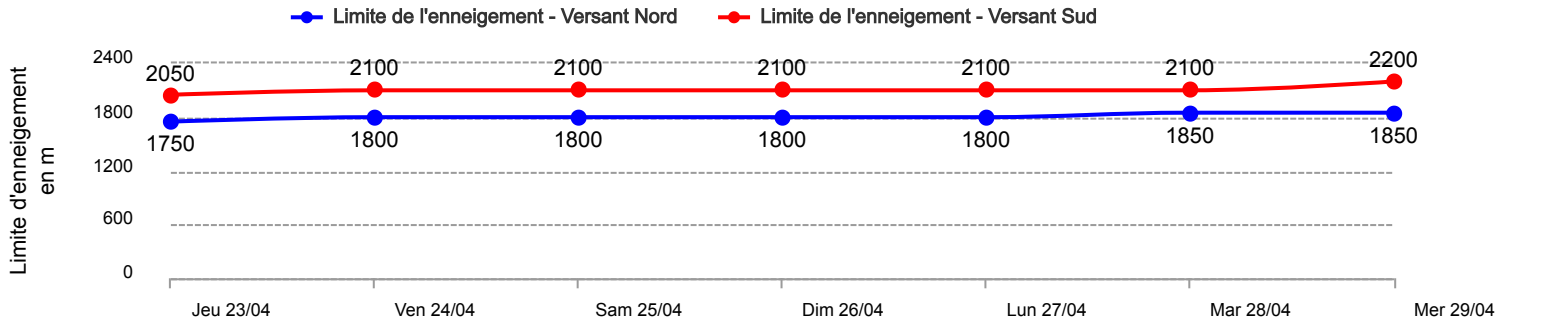

Pour consulter la vigilance en cours, veuillez vous rendre sur le site https://vigilance.meteofrance.fr/fr

Météo-France - 73 avenue de Paris, 94165 Saint-Mandé cedex - Contact : contact@meteo.fr

Rédigé par Météo-France avec la contribution des observateurs du réseau nivo-météorologiques. Partenariat : ANMSM (Maires de Stations de Montagne), DSF (Domaines Skiables de France), ADSP (Directeurs de Pistes et de la Sécurité des Stations de Sports d'Hiver) et autres acteurs de la montagne.

Bulletin neige & avalanches par téléphone au
0 892 68 10 20
Service 0,35 € / min + prix appel