Bulletin d'estimation du risque d'avalanche
(valable en dehors des pistes balisées et ouvertes)

MASSIF : Bauges

Rédigé le mercredi 29 avril 2026 à 16h

Estimation des risques pour le : JEUDI 30 AVRIL

ENCORE DES NÉVÉS D'ALTITUDES.

1

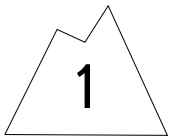

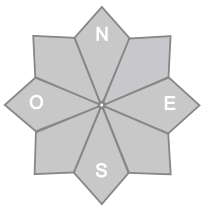

Indice de risque faible.

Départs spontanés : peu probable

Déclenchements provoqués : peu probable

Indices de risque : 5 très fort - 4 fort - 3 marqué - 2 limité - 1 faible -- En noir : les pentes les plus dangereuses

Stabilité du manteau neigeux

Situation avalancheuse typique : avalanches de fond

Départs spontanés :
* au-dessus de 1700 m : rares et petites coulées de neige humide, au fil du réchauffement diurne. Taille 1 (petite).
* au-dessus de 1700 m : rares plaques de fond dans les zones herbeuses ou les dalles rocheuses, à toute heure du jour ou de la nuit. Taille 2 (moyenne).

Déclenchements provoqués :
* peu probable. On peut éventuellement pousser un peu de neige humide aux heures les plus chaudes.

Qualité de la neige

Enneigement :
Pour la saison, l'enneigement est déficitaire à très déficitaire.
Encore un peu de neige au-dessus de 1700 m en nord. Les versants sud sont secs.

Qualité de la neige jeudi
Au-dessus de 1700 m en nord : neige de névé. Bon regel nocturne.
Ailleurs, il n'y a plus de neige.

Aperçu météo pour le jeudi 30 avril

	nuit	matin	après-midi	soir

Plutôt beau le matin puis rares averses sur le relief dans l'après-midi. Températures à 1500 m : de 5 à 16 °C.

Pluie-Neige	2 500 m			
Iso 0 °C	3 000 m	3 000 m	3 000 m	3 000 m
Vent 1500 m	5 km/h	15 km/h	15 km/h	5 km/h
Vent 2000 m	15 km/h	20 km/h	20 km/h	10 km/h

Épaisseur de neige hors-piste

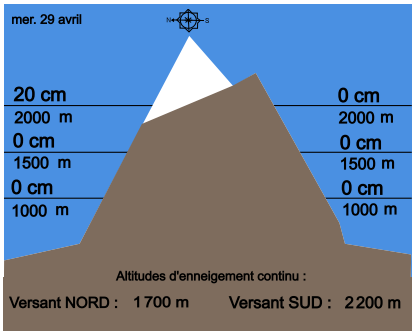

Précipitations à 1800 m

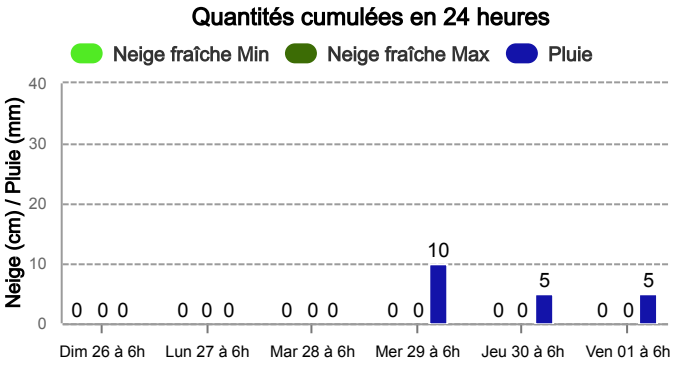

Tendance du vendredi 01 mai

1

Indice de risque faible

Peu d'évolution. Beau temps ensoleillé.

Pour consulter la vigilance en cours, veuillez vous rendre sur le site https://vigilance.meteofrance.fr/fr

Météo-France - 73 avenue de Paris, 94165 Saint-Mandé cedex - Contact : contact@meteo.fr

Rédigé par Météo-France avec la contribution des observateurs du réseau nivo-météorologiques. Partenariat : ANMSM (Maires de Stations de Montagne), DSF (Domaines Skiables de France), ADSP (Directeurs de Pistes et de la Sécurité des Stations de Sports d'Hiver) et autres acteurs de la montagne.

Bulletin neige & avalanches par téléphone au
0 892 68 10 20 Service 0,35 € / min + prix appel

Bulletin d'estimation du risque d'avalanche

(valable en dehors des pistes balisées et ouvertes)

MASSIF : Bauges

Rédigé le mercredi 29 avril 2026 à 16h

Conditions nivo-météo des 7 derniers jours

	jeu. 23/04				ven. 24/04				sam. 25/04				dim. 26/04				lun. 27/04				mar. 28/04				mer. 29/04			
	03h	09h	15h	21h	03h	09h	15h	21h	03h	09h	15h	21h	03h	09h	15h	21h	03h	09h	15h	21h	03h	09h	15h	21h	03h	09h	15h	21h
Météo																												
Vent (km/h)	10	10	10	10	10	10	10	10	15	10	20	25	10	15	15	10	10	5	10	15	15	15	25	15	20	5	5	10
à 2000m																												
Vent (km/h)	5	5	5	5	5	5	5	5	5	5	15	15	5	10	10	10	5	5	10	10	10	10	15	10	10	10	10	5
à 1500m																												

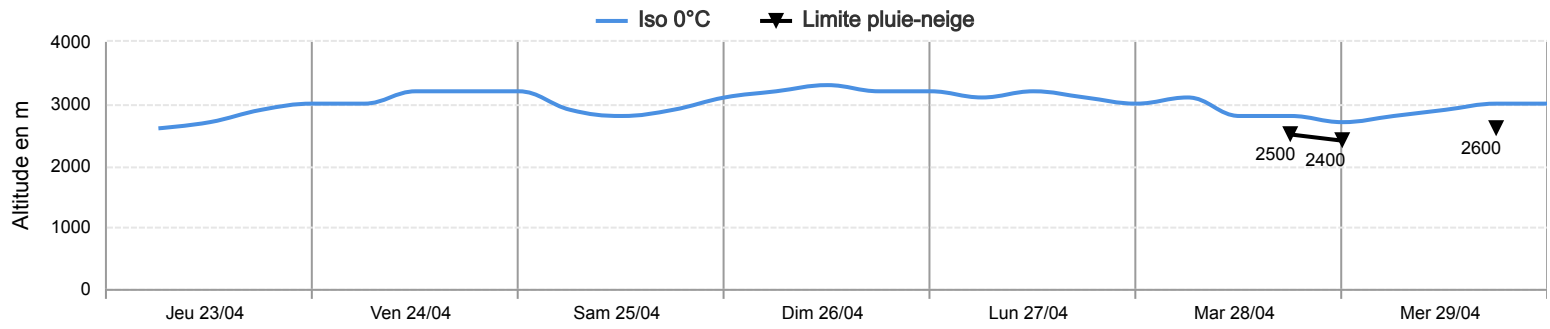

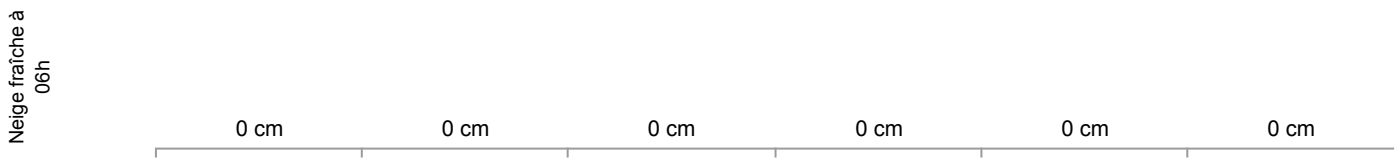

Risque d'avalanche	jeu. 23/04	ven. 24/04	sam. 25/04	dim. 26/04	lun. 27/04	mar. 28/04	mer. 29/04
	1	1	1	1	1	1	1

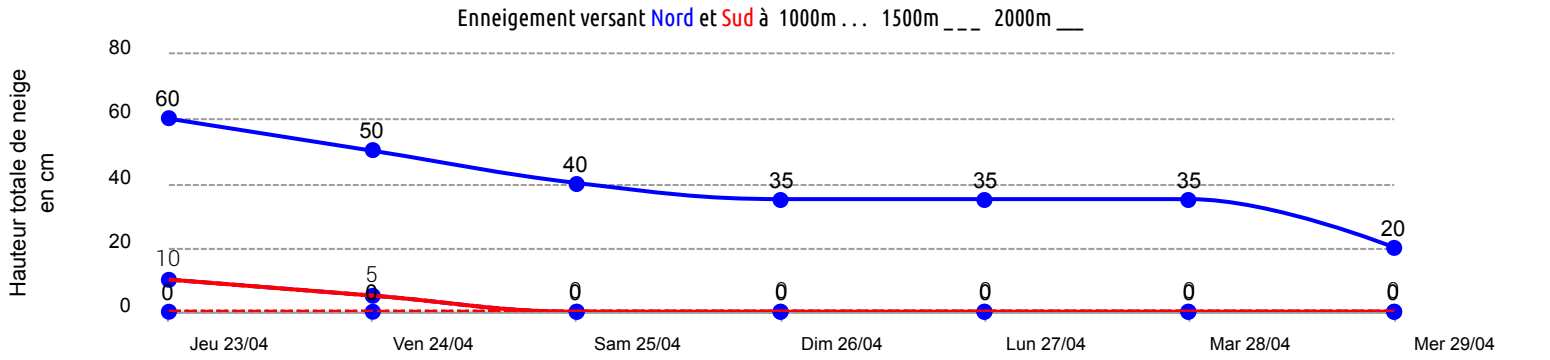

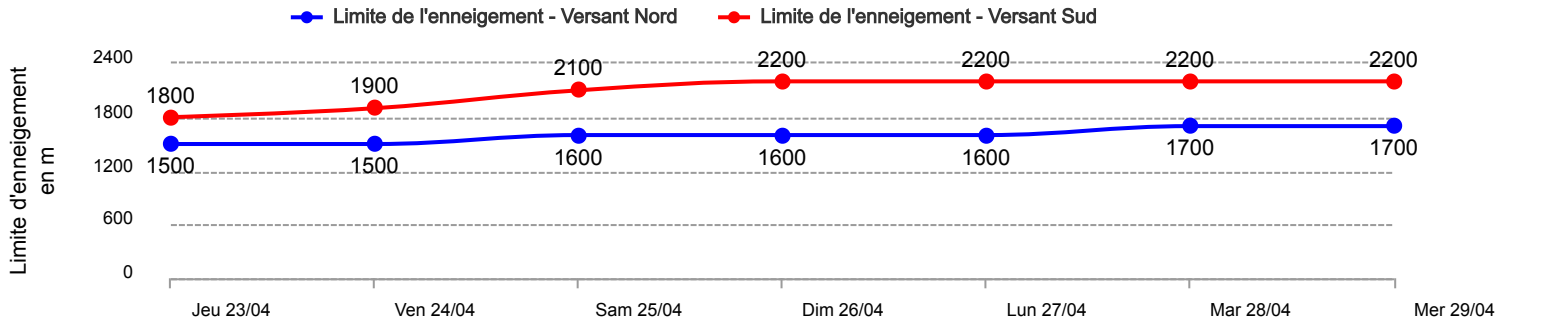

Pour consulter la vigilance en cours, veuillez vous rendre sur le site https://vigilance.meteofrance.fr/fr

Météo-France - 73 avenue de Paris, 94165 Saint-Mandé cedex - Contact : contact@meteo.fr

Bulletin neige & avalanches par téléphone au

0 892 68 10 20 Service 0,35 € / min + prix appel

Rédigé par Météo-France avec la contribution des observateurs du réseau nivo-météorologiques. Partenariat : ANMSM (Maires de Stations de Montagne), DSF (Domaines Skiables de France), ADSP (Directeurs de Pistes et de la Sécurité des Stations de Sports d'Hiver) et autres acteurs de la montagne.