Bulletin d'estimation du risque d'avalanche
(valable en dehors des pistes balisées et ouvertes)

MASSIF : Chablais

Rédigé le mercredi 29 avril 2026 à 16h

Estimation des risques pour le : JEUDI 30 AVRIL

MANTEAU NEIGEUX STABLE

2

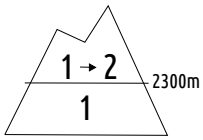

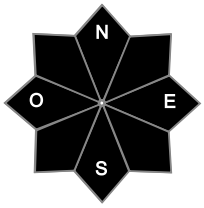

Au-dessus de 2300m indice de risque faible évoluant en limité, plus bas indice faible.

Départs spontanés : Plaques de fond

Déclenchements provoqués : De la neige humide peut couler sous les skis.

Indices de risque : 5 très fort - 4 fort - 3 marqué - 2 limité - 1 faible -- En noir : les pentes les plus dangereuses

Stabilité du manteau neigeux

Situation avalancheuse typique : neige humide — avalanches de fond

Départs spontanés :
* Quelques plaques de fond dans les pentes raides et lisses (pentes herbeuses, dalles rocheuses). Possibles à toute heure du jour et de la nuit. Taille 2 (moyenne).
* **Avalanches de neige humide** au fil de la course du soleil. Taille 1 (petite) rarement 2 (moyenne)

Facteur aggravant, **au-dessus de 2400 m en versants E/N/O : un départ en cascade en plaque n'est pas exclu**. Cassure de 50/80 cm possibles. Taille 2 (moyenne).

Déclenchements provoqués :
* Déclenchements ponctuels de neige humide sous les pieds ou les skis. Facilement déclenchables. Causé par les précipitations pluvieuses puis par le réchauffement diurne. Taille 1 (petite).

Qualité de la neige

Enneigement :
Pour la saison, l'enneigement est déficitaire à toutes altitudes.
On peut chausser les skis au-dessus de 2000/2300 m en sud et 1700/1900 m en nord.

Qualité de la neige jeudi :
* En dessous de 2400 m, manteau neigeux humide en profondeur, voire neige de névé, avec un bon regel nocturne.
* Au-dessus de 2400 m : manteau neigeux printanier, qui s'humidifie en surface au fil des heures. Bon regel nocturne.

Aperçu météo pour le jeudi 30 avril

Plutôt beau le matin puis rares averses sur le relief dans l'après-midi. Températures à 2000 m : de 5 à 11°C.

	nuit	matin	après-midi	soir
Pluie-Neige	2 500 m			
Iso 0 °C	3 000 m	3 000 m	3 000 m	3 000 m
Vent 2000 m	5 km/h	5 km/h	10 km/h	5 km/h
Vent 2500 m	15 km/h	15 km/h	15 km/h	10 km/h

Épaisseur de neige hors-piste

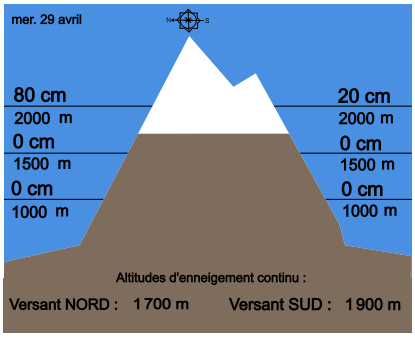

Précipitations à 1800 m

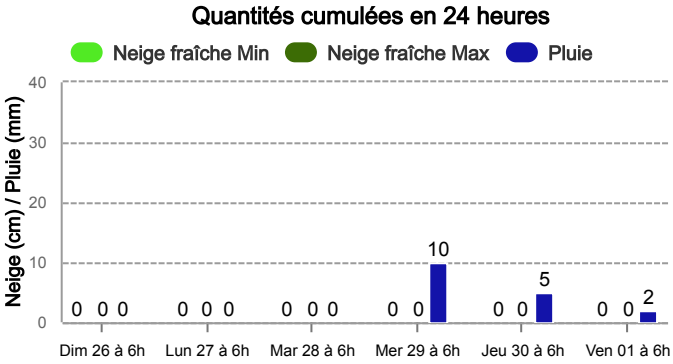

Tendance du vendredi 01 mai

2

Indice de risque limité

Peu d'évolution. Beau temps ensoleillé.

Pour consulter la vigilance en cours, veuillez vous rendre sur le site https://vigilance.meteofrance.fr/fr

Météo-France - 73 avenue de Paris, 94165 Saint-Mandé cedex - Contact : contact@meteo.fr

Rédigé par Météo-France avec la contribution des observateurs du réseau nivo-météorologiques. Partenariat : ANMSM (Maires de Stations de Montagne), DSF (Domaines Skiables de France), ADSP (Directeurs de Pistes et de la Sécurité des Stations de Sports d'Hiver) et autres acteurs de la montagne.

Bulletin neige & avalanches par téléphone au 0 892 68 10 20 Service 0,35 € / min + prix appel

Bulletin d'estimation du risque d'avalanche

(valable en dehors des pistes balisées et ouvertes)

MASSIF : Chablais

Rédigé le mercredi 29 avril 2026 à 16h

Conditions nivo-météo des 7 derniers jours

	jeu. 23/04				ven. 24/04				sam. 25/04				dim. 26/04				lun. 27/04				mar. 28/04				mer. 29/04			
	03h	09h	15h	21h	03h	09h	15h	21h	03h	09h	15h	21h	03h	09h	15h	21h	03h	09h	15h	21h	03h	09h	15h	21h	03h	09h	15h	21h
Météo																												
Vent (km/h)	10	20	20	20	10	5	10	10	10	20	15	5	5	10	5	10	20	5	20	20	20	15	15	25	30	10	10	10
à 2500m																												
Vent (km/h)	5	15	10	10	5	5	5	5	10	15	15	5	5	10	5	5	10	5	10	10	10	10	10	15	20	5	5	5
à 2000m																												

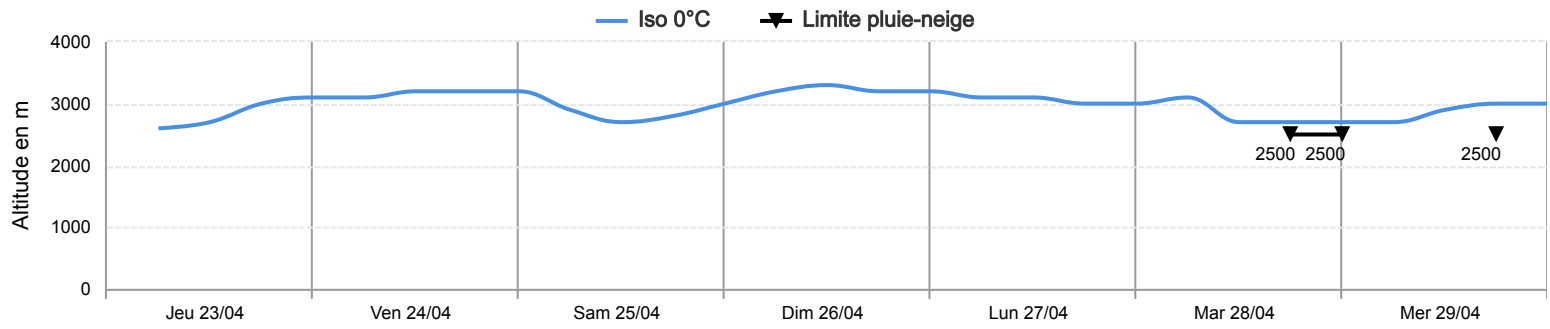

Neige fraîche à 06h

jeu. 23/04	ven. 24/04	sam. 25/04	dim. 26/04	lun. 27/04	mar. 28/04	mer. 29/04
0 cm	0 cm	0 cm	0 cm	0 cm	0 cm	

Risque d'avalanche	jeu. 23/04	ven. 24/04	sam. 25/04	dim. 26/04	lun. 27/04	mar. 28/04	mer. 29/04
	2	2	2	2	2	2	2

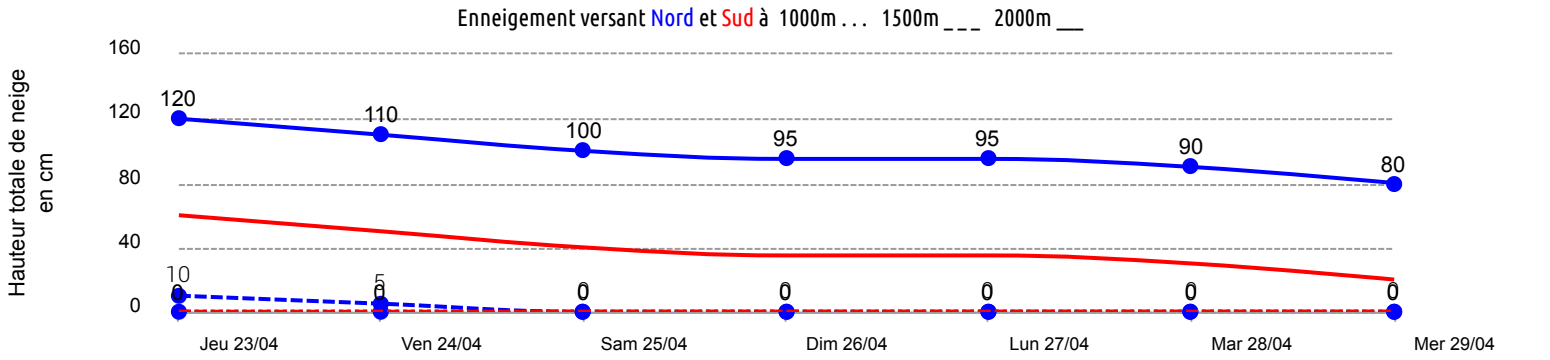

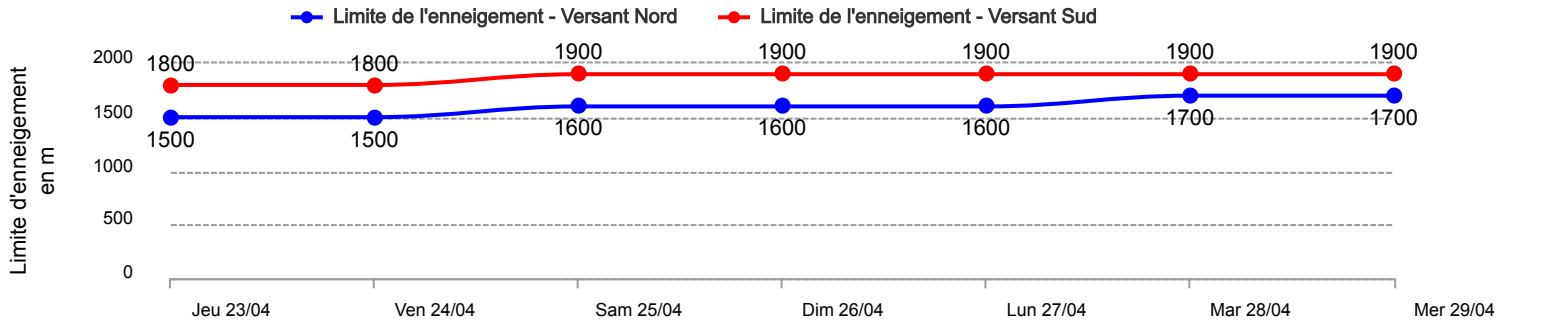

Pour consulter la vigilance en cours, veuillez vous rendre sur le site https://vigilance.meteofrance.fr/fr

Météo-France - 73 avenue de Paris, 94165 Saint-Mandé cedex - Contact : contact@meteo.fr

Bulletin neige & avalanches par téléphone au 0 892 68 10 20 Service 0,35 € / min + prix appel

Rédigé par Météo-France avec la contribution des observateurs du réseau nivo-météorologiques. Partenariat : ANMSM (Maires de Stations de Montagne), DSF (Domaines Skiables de France), ADSP (Directeurs de Pistes et de la Sécurité des Stations de Sports d'Hiver) et autres acteurs de la montagne.