Bulletin d'estimation du risque d'avalanche

(valable en dehors des pistes balisées et ouvertes)

MASSIF : Embrunais Parpaillon

Rédigé le mercredi 29 avril 2026 à 16h

Estimation des risques pour le : JEUDI 30 AVRIL

MANTEAU NEIGEUX PRINTANIER - DENSE ET STABLE

1

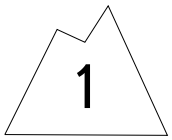

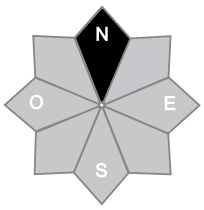

Indice de risque faible.

Départs spontanés : peu probables.

Déclenchements provoqués : rares en neige humide sous les skis.

Indices de risque : 5 très fort - 4 fort - 3 marqué - 2 limité - 1 faible -- En noir : les pentes les plus dangereuses

Stabilité du manteau neigeux

Situation avalancheuse typique : neige humide

Départs spontanés : peu probables compte-tenu du faible enneigement. Rare activité superficielle en neige humide au soleil en journée. Une rare avalanche moyenne (taille 2) par départ linéaire reste possible dans les pentes nord-ouest à nord-est au dessus de 2500/2700 m.

Déclenchements provoqués : un skieur coupant tardivement une pente raide peut initier un départ de neige humide sous les skis, de petite taille et seulement en ubacs raides de haute altitude.

Dans l'après-midi, les précipitations sous averse ou orage, neigeuses au dessus de 2600 m environ, ne devraient pas sensiblement modifier la stabilité du manteau neigeux.

Qualité de la neige

Enneigement déficitaire pour la période, notamment en adrets.
Hauteurs de neige observées vers 2500 m : 44 cm à la nivôse du Parpaillon.

Limite d'enneigement skiable : au plus bas à 2000 m en ubacs bien protégés ou sur pistes forestières.

État de la neige de surface : manteau neigeux printanier, voire de névé en toute orientation sous 2500 m environ et en adrets de haute altitude. Regel nocturne, puis reprise de l'humidification en journée.

Aperçu météo pour le jeudi 30 avril

	nuit	matin	après-midi	soir
	Nuages et soleil, puis averses orageuses l'après-midi.			
Pluie-Neige	2 600 m			
Iso 0 °C	3 100 m	3 000 m	3 000 m	3 000 m
Vent 2000 m	← 10 km/h	↙ 15 km/h	↗ 25 km/h	↙ 10 km/h
Vent 3000 m	→ 5 km/h	↘ 10 km/h	↙ 10 km/h	← 10 km/h

Épaisseur de neige hors-piste

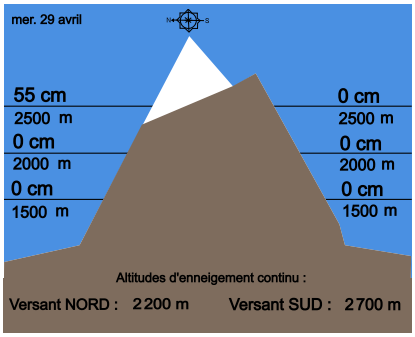

Précipitations à 1800 m

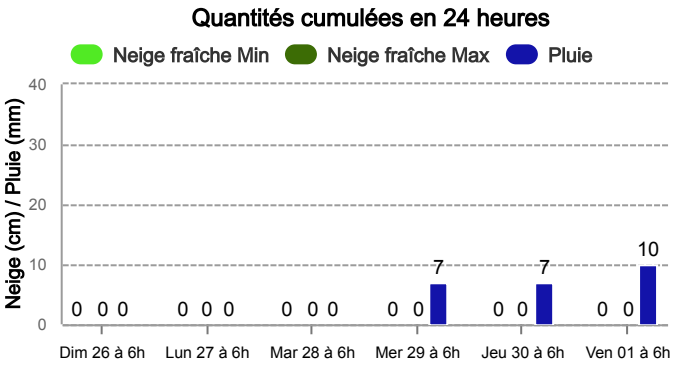

Tendance du vendredi 01 mai

1

Indice de risque faible

Peu d'évolution du risque compte-tenu du faible enneigement.

Pour consulter la vigilance en cours, veuillez vous rendre sur le site https://vigilance.meteofrance.fr/fr

Météo-France - 73 avenue de Paris, 94165 Saint-Mandé cedex - Contact : contact@meteo.fr

Rédigé par Météo-France avec la contribution des observateurs du réseau nivo-météorologiques. Partenariat : ANMSM (Maires de Stations de Montagne), DSF (Domaines Skiables de France), ADSP (Directeurs de Pistes et de la Sécurité des Stations de Sports d'Hiver) et autres acteurs de la montagne.

Bulletin neige & avalanches par téléphone au

0 892 68 10 20 Service 0,35 € / min + prix appel

RÉPUBLIQUE FRANÇAISE
Liberté Égalité Fraternité

METEO FRANCE
À VOS CÔTÉS, DANS UN CLIMAT QUI CHANGE

Bulletin d'estimation du risque d'avalanche

(valable en dehors des pistes balisées et ouvertes)

MASSIF : Embrunais Parpaillon

Rédigé le mercredi 29 avril 2026 à 16h

Conditions nivo-météo des 7 derniers jours

	jeu. 23/04				ven. 24/04				sam. 25/04				dim. 26/04				lun. 27/04				mar. 28/04				mer. 29/04			
	03h	09h	15h	21h	03h	09h	15h	21h	03h	09h	15h	21h	03h	09h	15h	21h	03h	09h	15h	21h	03h	09h	15h	21h	03h	09h	15h	21h
Météo																												
Vent (km/h)	20	20	15	25	20	10	5	5	10	15	10	10	10	5	15	5	10	10	15	15	15	20	30	15	10	10	15	15
à 3000m	↓	↙	↙	←	↙	↘	↘	↑	→	→	↘	↙	↙	←	→	→	→	→	→	→	↗	↗	↗	↗	→	↗	↗	→
Vent (km/h)	10	15	20	10	10	10	20	10	5	10	25	10	10	10	20	10	5	10	15	10	10	15	25	10	10	15	20	10
à 2000m	↓	←	↙	↖	←	↑	↗	↖	↖	↑	↗	←	↘	↑	↗	↑	←	↑	↗	↑	↘	↑	↗	↖	←	↖	↗	↓

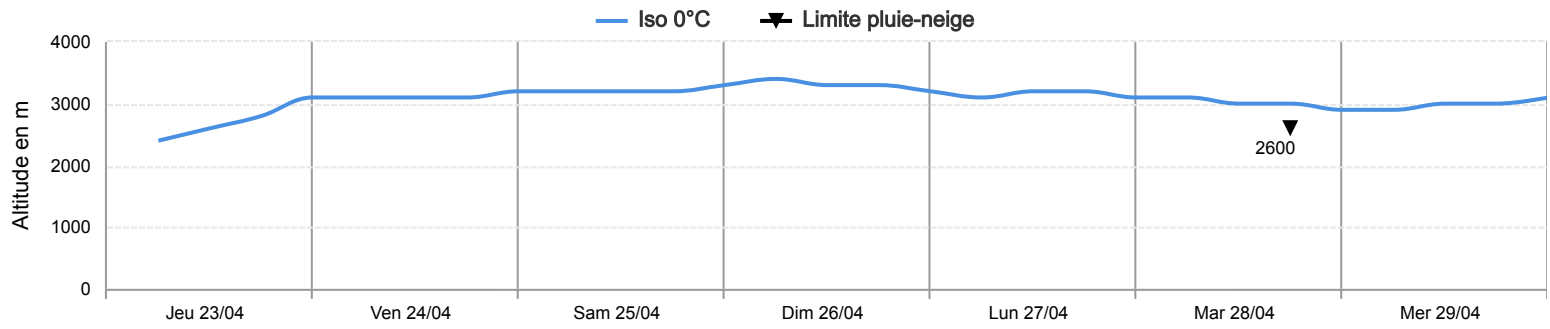

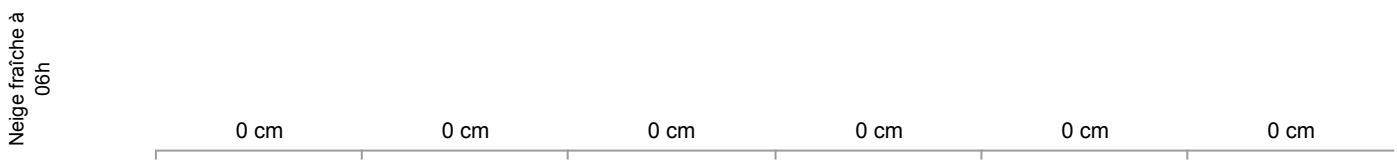

Risque d'avalanche	jeu. 23/04	ven. 24/04	sam. 25/04	dim. 26/04	lun. 27/04	mar. 28/04	mer. 29/04
	2	2	2	2	2	2	2

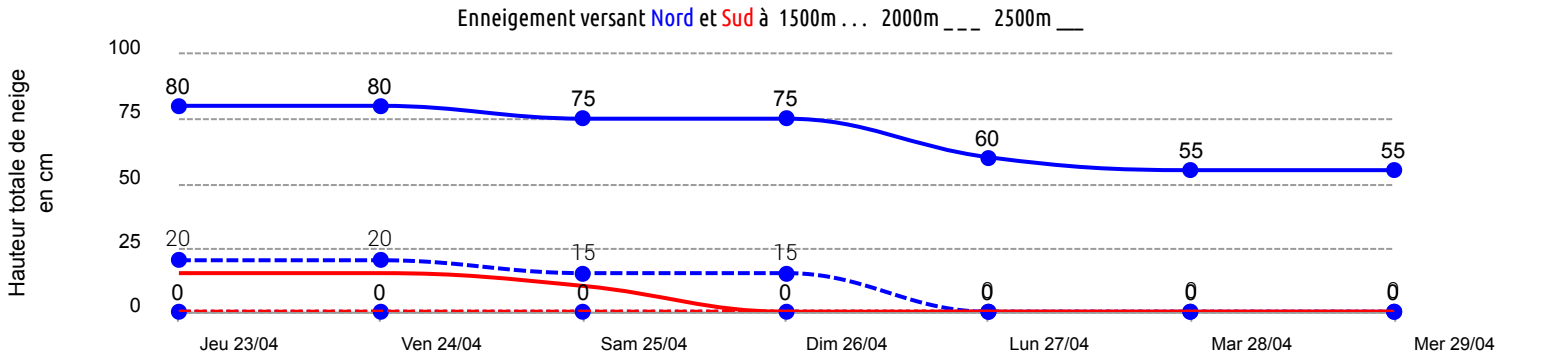

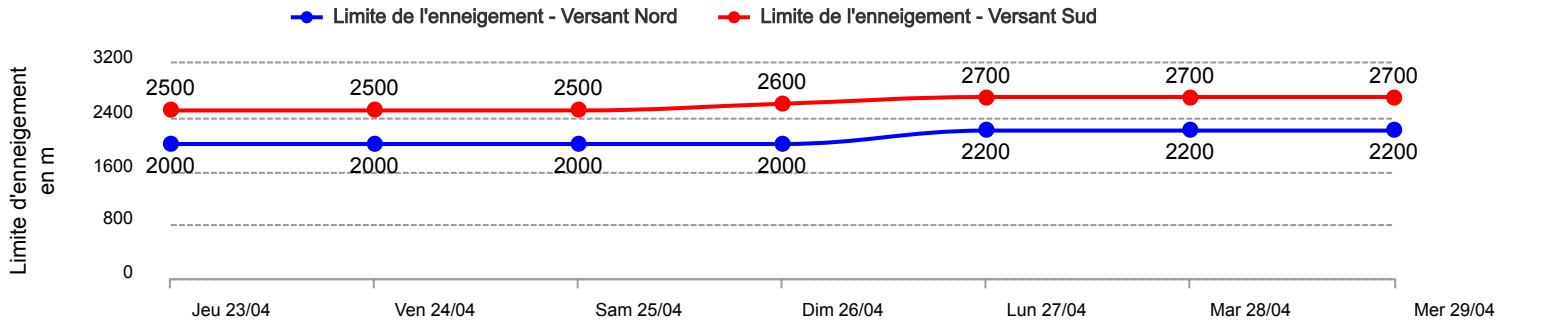

Pour consulter la vigilance en cours, veuillez vous rendre sur le site https://vigilance.meteofrance.fr/fr

Météo-France - 73 avenue de Paris, 94165 Saint-Mandé cedex - Contact : contact@meteo.fr

Bulletin neige & avalanches par téléphone au

0 892 68 10 20 Service 0,35 € / min + prix appel

Rédigé par Météo-France avec la contribution des observateurs du réseau nivo-météorologiques. Partenariat : ANMSM (Maires de Stations de Montagne), DSF (Domaines Skiables de France), ADSP (Directeurs de Pistes et de la Sécurité des Stations de Sports d'Hiver) et autres acteurs de la montagne.