RÉPUBLIQUE FRANÇAISE
Liberté Égalité Fraternité

METEO FRANCE
À VOS CÔTÉS, DANS UN CLIMAT QUI CHANGE

Bulletin d'estimation du risque d'avalanche
(valable en dehors des pistes balisées et ouvertes)

MASSIF : Pelvoux

Rédigé le mercredi 29 avril 2026 à 16h

Estimation des risques pour le : JEUDI 30 AVRIL

MANTEAU NEIGEUX PRINTANIER. RARE ACTIVITÉ EN NEIGE HUMIDE

2

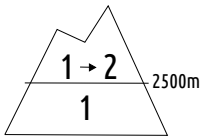

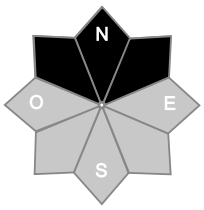

Au-dessus de 2500m indice de risque faible évoluant en limité, plus bas indice faible.

Départs spontanés : rares en neige humide.

Déclenchements provoqués : rares en neige humide.

Indices de risque : 5 très fort - 4 fort - 3 marqué - 2 limité - 1 faible -- En noir : les pentes les plus dangereuses

Stabilité du manteau neigeux

Situation avalancheuse typique : neige humide

Départs spontanés : après un regel nocturne modéré, l'humidification du manteau neigeux se poursuit au soleil, puis sous les averses en cours d'après-midi. Rares avalanches en neige humide généralement par départ ponctuel de petite taille. Très localement départ linéaire possible dans les pentes nord-ouest, nord et nord-est au-dessus de 2500 m environ, de taille moyenne, grande non exclue, en cas d'humidification d'une couche fragile persistante enfouie dans le manteau neigeux.

Déclenchements provoqués : un skieur coupant tardivement une pente raide peut initier un départ de neige humide sous les skis, de petite taille et seulement en ubacs raides de haute altitude.

En dessous de 2500 m, et dans les adrets jusqu'à haute altitude, le manteau neigeux est désormais dense et bien stabilisé.

Dans l'après-midi, les précipitations sous averse ou orage, neigeuses au dessus de 2600 m environ, ne devraient pas sensiblement modifier la stabilité du manteau neigeux.

Qualité de la neige

Enneigement déficitaire sur le massif, particulièrement en adrets.
Hauteurs de neige observées : 203 cm à la nivôse des Écrins à 2970 m.

Limite d'enneigement skiable : très localement vers 1900 m en fond de vallée en cœur de massif, 2300/2400 m en adrets.

État de la neige de surface : manteau neigeux printanier, voire de névé en toute orientation sous 2500 m environ et en adrets de haute altitude. Quelques cm de neige fraîche localement possibles, tombés sous une averse de neige de mercredi après-midi, au delà de 2700/2800 m. Regel nocturne modéré, puis reprise de l'humidification en journée.

Aperçu météo pour le jeudi 30 avril

	nuit	matin	après-midi	soir
	Nuages et soleil, puis averses l'après-midi, accompagnées d'un risque orageux.			
Pluie-Neige	2 700 m	2 600 m	2 600 m	
Iso 0 °C	3 100 m	3 200 m	3 300 m	3 000 m
Vent 2000 m	↙ 5 km/h	↙ 15 km/h	← 20 km/h	↙ 5 km/h
Vent 3000 m	↗ 15 km/h	↑ 10 km/h	↗ 15 km/h	↙ 10 km/h

Épaisseur de neige hors-piste

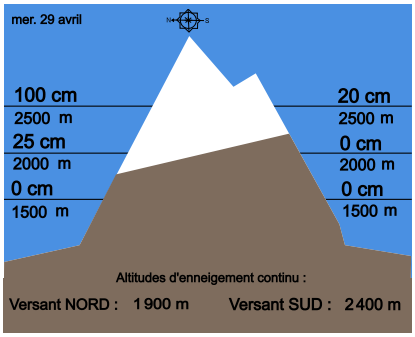

Précipitations à 1800 m

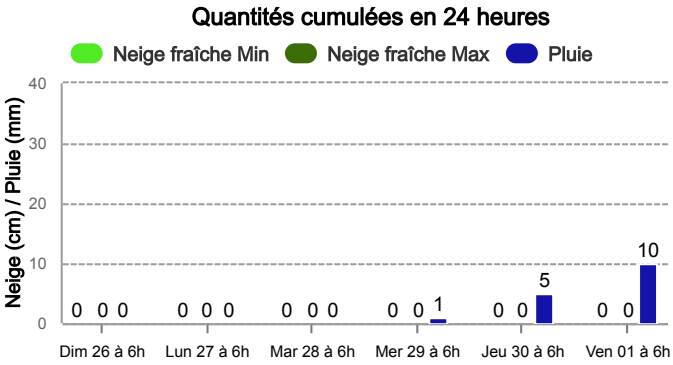

Tendance du vendredi 01 mai

2

Indice de risque limité

Peu d'évolution des conditions, avec la poursuite de l'humidification du manteau neigeux au soleil. Quelques averses l'après-midi.

Pour consulter la vigilance en cours, veuillez vous rendre sur le site https://vigilance.meteofrance.fr/fr

Météo-France - 73 avenue de Paris, 94165 Saint-Mandé cedex - Contact : contact@meteo.fr

Rédigé par Météo-France avec la contribution des observateurs du réseau nivo-météorologiques. Partenariat : ANMSM (Maires de Stations de Montagne), DSF (Domaines Skiables de France), ADSP (Directeurs de Pistes et de la Sécurité des Stations de Sports d'Hiver) et autres acteurs de la montagne.

Bulletin neige & avalanches par téléphone au
0 892 68 10 20 Service 0,35 € / min + prix appel

RÉPUBLIQUE FRANÇAISE
Liberté Égalité Fraternité

METEO FRANCE
À VOS CÔTÉS, DANS UN CLIMAT QUI CHANGE

Bulletin d'estimation du risque d'avalanche
(valable en dehors des pistes balisées et ouvertes)

MASSIF : Pelvoux

Rédigé le mercredi 29 avril 2026 à 16h

Conditions nivo-météo des 7 derniers jours

	jeu. 23/04				ven. 24/04				sam. 25/04				dim. 26/04				lun. 27/04				mar. 28/04				mer. 29/04			
	03h	09h	15h	21h	03h	09h	15h	21h	03h	09h	15h	21h	03h	09h	15h	21h	03h	09h	15h	21h	03h	09h	15h	21h	03h	09h	15h	21h
Météo																												
Vent (km/h)	20	15	15	10	10	10	10	10	10	15	15	10	10	10	15	10	10	10	15	15	15	20	30	15	10	10	15	10
à 3000m																												
Vent (km/h)	10	15	15	5	5	10	15	5	5	10	20	10	10	10	20	5	5	10	15	10	10	15	25	10	5	5	10	5
à 2000m																												

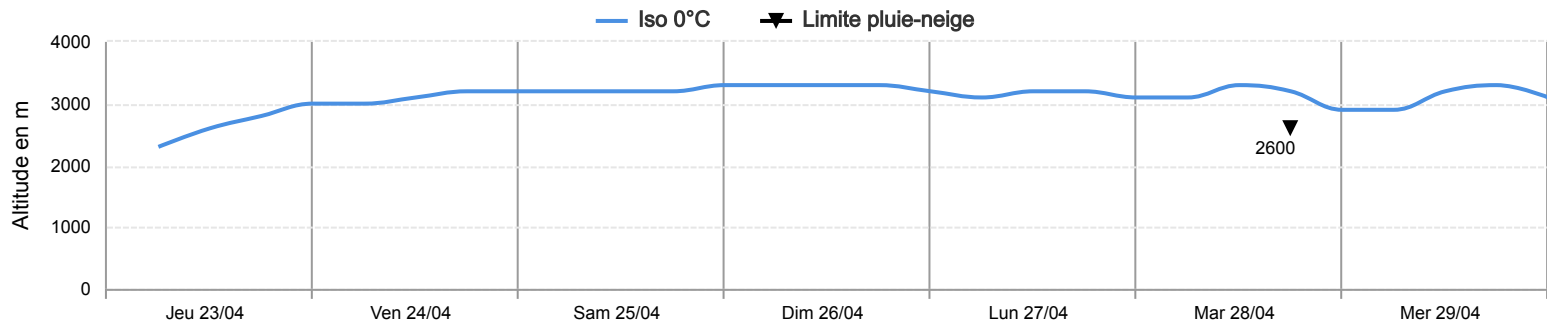

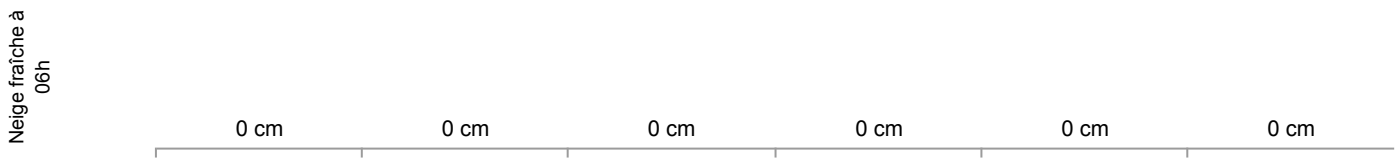

Risque d'avalanche	jeu. 23/04	ven. 24/04	sam. 25/04	dim. 26/04	lun. 27/04	mar. 28/04	mer. 29/04
	2	2	2	2	2	2	2

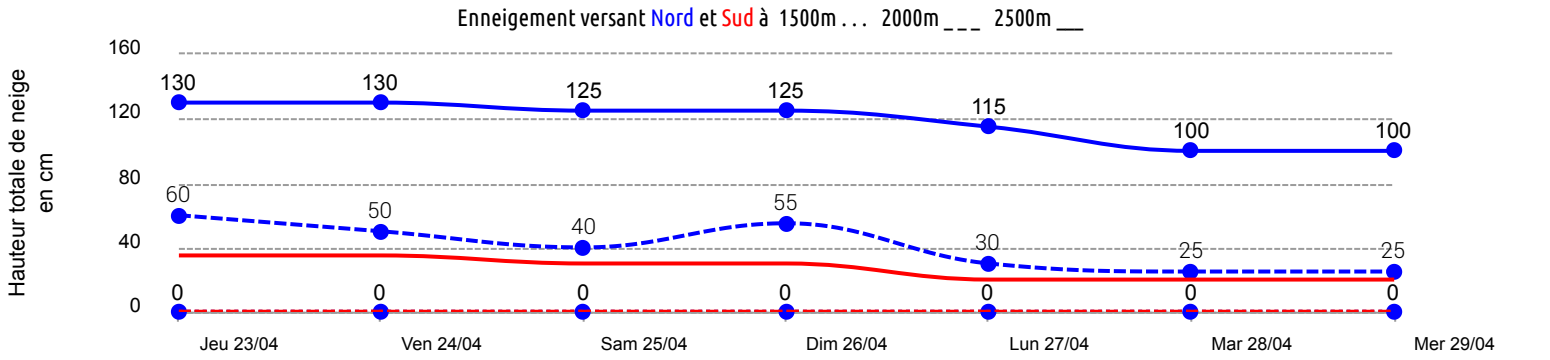

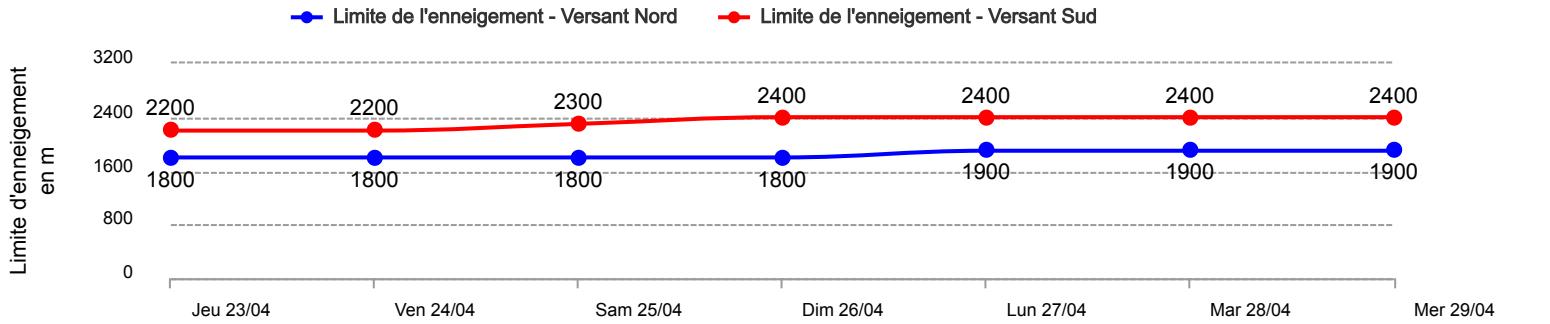

Pour consulter la vigilance en cours, veuillez vous rendre sur le site https://vigilance.meteofrance.fr/fr

Météo-France - 73 avenue de Paris, 94165 Saint-Mandé cedex - Contact : contact@meteo.fr

Rédigé par Météo-France avec la contribution des observateurs du réseau nivo-météorologiques. Partenariat : ANMSM (Maires de Stations de Montagne), DSF (Domaines Skiables de France), ADSP (Directeurs de Pistes et de la Sécurité des Stations de Sports d'Hiver) et autres acteurs de la montagne.

Bulletin neige & avalanches par téléphone au
0 892 68 10 20 Service 0,35 € / min + prix appel