Bulletin d'estimation du risque d'avalanche
(valable en dehors des pistes balisées et ouvertes)

MASSIF : Ubaye

Rédigé le mercredi 29 avril 2026 à 16h

Estimation des risques pour le : JEUDI 30 AVRIL

MANTEAU NEIGEUX PRINTANIER DE FIN DE SAISON BIEN STABLE

1

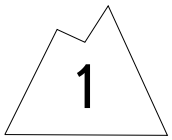

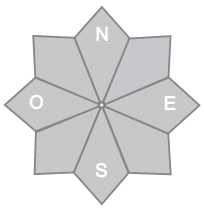

Indice de risque faible.

Départs spontanés : peu probables, manteau neigeux très stable

Déclenchements provoqués : peu probables, manteau neigeux très stable

Indices de risque : 5 très fort - 4 fort - 3 marqué - 2 limité - 1 faible -- En noir : les pentes les plus dangereuses

Stabilité du manteau neigeux

Situation avalancheuse typique : pas de situation prédominante

Déclenchements provoqués : le manteau neigeux est très faible pour une fin avril, et très stable. Les averses orageuses jeudi, plus actives sur le sud du massif, vers les Trois Evêchés, ne sont pas en mesure d'aggraver le danger d'avalanches.

Départs spontanés : peu probables, le manteau neigeux est entièrement humidifié et bien stable jusqu'à haute altitude.

Qualité de la neige

Enneigement exceptionnellement faible pour la période, après plus d'un mois sans précipitations notables et avec un isotherme 0 degré souvent à plus de 3000 m, l'enneigement est digne d'une fin mai, voire début juin. Il n'y a plus de neige à la nivôse de Restefond, c'est la première fois en 30 ans de mesure que l'enneigement disparaît avant le 1er mai à cet endroit.

Enneigement skiable à partir de 2200/2300 m en ubacs, avec beaucoup de relief en surface en raison de l'intense fonte jusqu'à 2500/2600 m environ

État de la neige en surface : manteau neigeux sous forme de névé qui continue de fondre rapidement. Les pentes nord de haute altitude (> 2800 m) ne sont pas encore totalement transformées. Faible regel nocturne, puis reprise rapide de l'humidification et de la fonte en cours de journée dans toutes les expositions. En fin de journée, les averses orageuses donnent un peu de neige fraîche très humide à partir de 2500/2600 m, notamment vers les Trois Evêchés.

Aperçu météo pour le jeudi 30 avril

	nuit	matin	après-midi	soir
	rapidement instable à la mi-journée, orages possiblement très pluvieux sur l'ouest du massif			
Pluie-Neige	2 500 m			
Iso 0 °C	3 100 m	3 000 m	2 900 m	2 700 m
Vent 2000 m	↖ 10 km/h	← 15 km/h	↗ 20 km/h	← 10 km/h
Vent 3000 m	↘ 10 km/h	↖ 10 km/h	↖ 15 km/h	↙ 15 km/h

Épaisseur de neige hors-piste

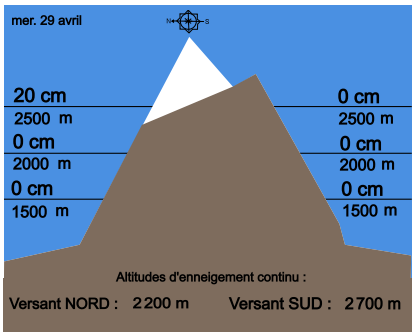

Précipitations à 1800 m

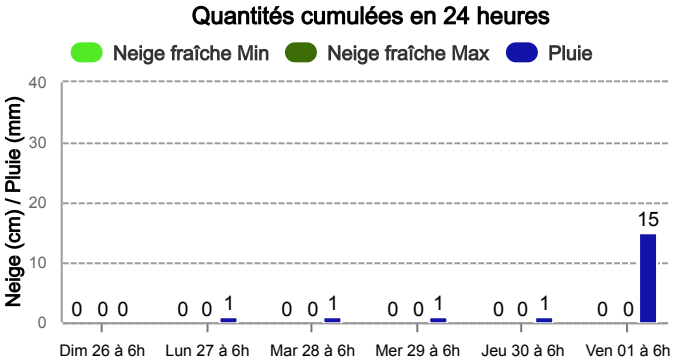

Tendance du vendredi 01 mai

1

Indice de risque faible

Peu d'évolution de la situation nivologique. Temps sec et chaud. Maintien d'un risque faible.

Pour consulter la vigilance en cours, veuillez vous rendre sur le site https://vigilance.meteofrance.fr/fr

Météo-France - 73 avenue de Paris, 94165 Saint-Mandé cedex - Contact : contact@meteo.fr

Rédigé par Météo-France avec la contribution des observateurs du réseau nivo-météorologiques. Partenariat : ANMSM (Maires de Stations de Montagne), DSF (Domaines Skiables de France), ADSP (Directeurs de Pistes et de la Sécurité des Stations de Sports d'Hiver) et autres acteurs de la montagne.

Bulletin neige & avalanches par téléphone au 0 892 68 10 20 Service 0,35 € / min + prix appel

RÉPUBLIQUE FRANÇAISE
Liberté Égalité Fraternité

METEO FRANCE
À VOS CÔTÉS, DANS UN CLIMAT QUI CHANGE

Bulletin d'estimation du risque d'avalanche

(valable en dehors des pistes balisées et ouvertes)

MASSIF : Ubaye

Rédigé le mercredi 29 avril 2026 à 16h

Conditions nivo-météo des 7 derniers jours

	jeu. 23/04				ven. 24/04				sam. 25/04				dim. 26/04				lun. 27/04				mar. 28/04				mer. 29/04			
	03h	09h	15h	21h	03h	09h	15h	21h	03h	09h	15h	21h	03h	09h	15h	21h	03h	09h	15h	21h	03h	09h	15h	21h	03h	09h	15h	21h
Météo																												
Vent (km/h)	15	15	20	10	15	15	20	15	15	20	20	15	10	15	20	10	10	15	20	20	15	15	15	15	15	10	10	10
à 3000m																												
Vent (km/h)	10	10	15	10	10	10	20	5	5	10	25	5	5	10	20	10	5	10	20	15	5	15	25	10	10	15	20	10
à 2000m																												

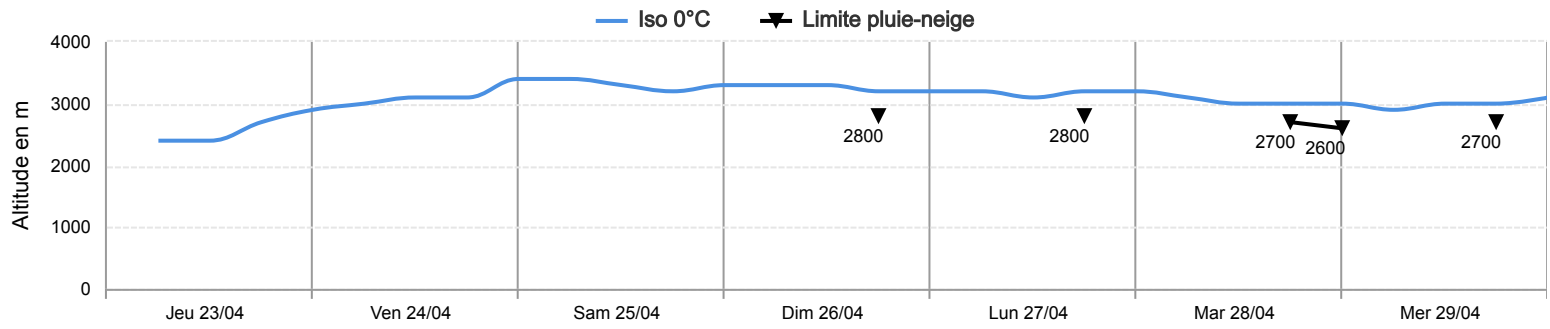

Neige fraîche à 06h						
	0 cm	0 cm	0 cm	0 cm	0 cm	0 cm

Risque d'avalanche						
jeu. 23/04	ven. 24/04	sam. 25/04	dim. 26/04	lun. 27/04	mar. 28/04	mer. 29/04

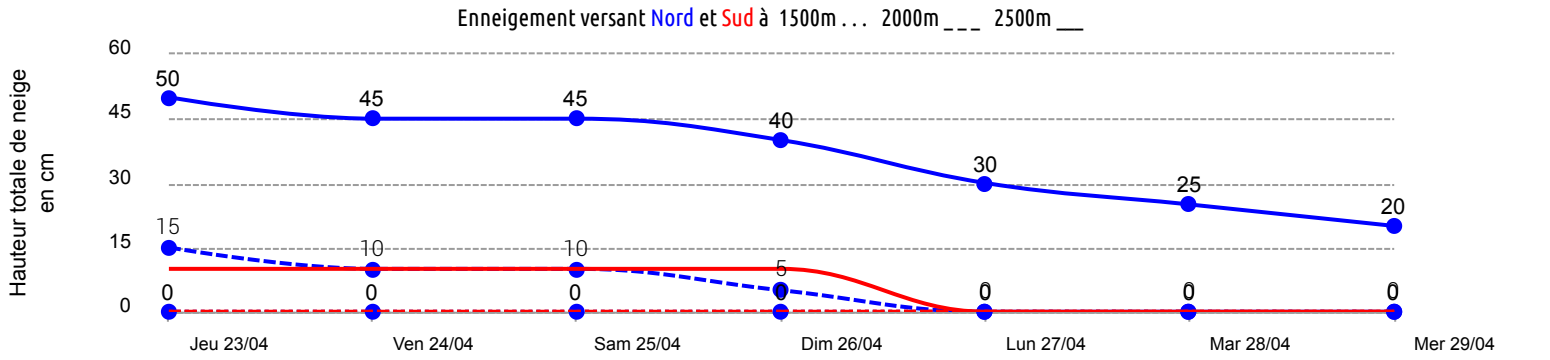

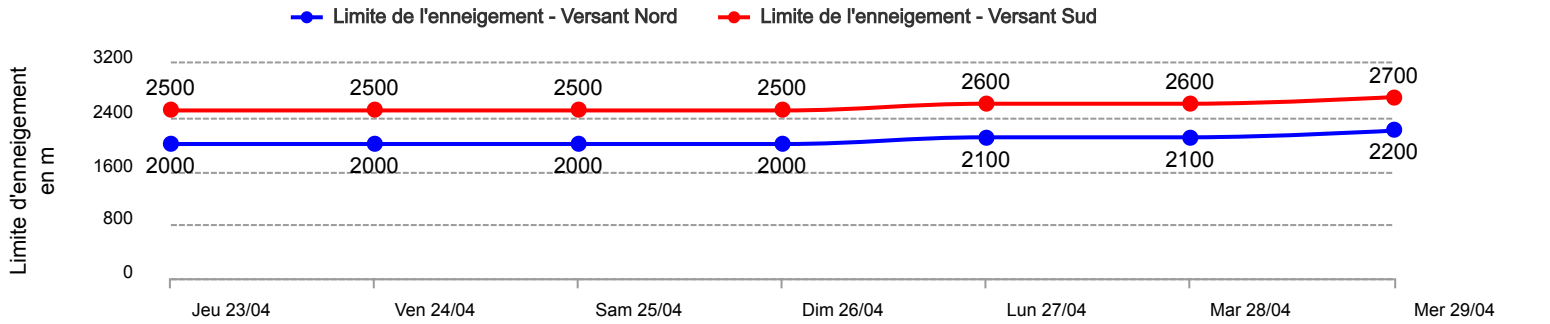

Pour consulter la vigilance en cours, veuillez vous rendre sur le site https://vigilance.meteofrance.fr/fr

Météo-France - 73 avenue de Paris, 94165 Saint-Mandé cedex - Contact : contact@meteo.fr

Bulletin neige & avalanches par téléphone au 0 892 68 10 20 Service 0,35 € / min + prix appel

Rédigé par Météo-France avec la contribution des observateurs du réseau nivo-météorologiques. Partenariat : ANMSM (Maires de Stations de Montagne), DSF (Domaines Skiables de France), ADSP (Directeurs de Pistes et de la Sécurité des Stations de Sports d'Hiver) et autres acteurs de la montagne.