# Bulletin d'estimation du risque d'avalanche
(valable en dehors des pistes balisées et ouvertes)

# MASSIF : Vanoise

Rédigé le mercredi 29 avril 2026 à 16h

## Estimation des risques pour le : JEUDI 30 AVRIL

**L'HUMIDIFICATION EN PROFONDEUR CONTINUE**

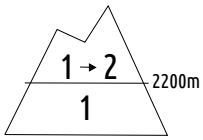


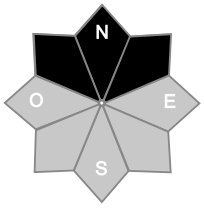


Au-dessus de 2200m indice de risque faible évoluant en limité, plus bas indice faible.

**Départs spontanés :** rares mais possibles grands départs en neige humide.

**Déclenchements provoqués :** coulées humides sous les skis.

Indices de risque : 5 très fort - 4 fort - 3 marqué - 2 limité - 1 faible -- En noir : les pentes les plus dangereuses

## Stabilité du manteau neigeux

**Situation avalancheuse typique :** neige humide

**Départs spontanés :**
- Au dessus de 2200 m en versants Est et Ouest d'altitude, mais surtout en Nord, l'humidification marquée se poursuit et gagne encore en profondeur. **Un rare départ linéaire est possible** quand l'humidification atteint une couche fragile enfouie (très présentes à la base du manteau dans les versants Nord), **moyenne à grande avalanche (taille 2 voire 3)**.
- Sous 2200 m en Nord et à toute altitude en Sud, les pentes sont maintenant bien stabilisées, avec une neige dense de type névé sur toute l'épaisseur du manteau.

**Déclenchements provoqués :** peu probables sauf avalanche de neige humide (pourrie) sous les skis en coupant une pente trop humidifiée.

**Autres :** chutes de corniches signalées et attendues.

## Qualité de la neige

**Enneigement :** déficitaire pour la saison à cause de la chaleur durablement excessive. La très haute montagne est quasi sèche à cause des épisodes de vent de l'hiver et de l'absence de précipitations significative ces dernières semaines.

**Limite skiable :** vers 1700/1800 m en nord, 2000/2200 m en sud en pente douce, bien plus haut en pente sud raide.

**Qualité de la neige** : Sous 2200 m en Nord et bien plus haut dans les autres orientations, neige de névé qui reste dense toute la journée. Regel correct, neige de printemps le matin qui chauffe et pourrit vite en Est, cet état de neige se généralise l'après-midi avec la chaleur et les averses. Il faut monter au-dessus de 3200 m en plein Nord pour espérer trouver de la neige froide.

## Aperçu météo pour le jeudi 30 avril

| | nuit | matin | après-midi | soir |
|---|---|---|---|---|
| | | | | |

Beau temps chaud, dans l'après midi les cumulus se développent, possible averse ORAGEUSE.

| | | | | |
|---|---|---|---|---|
| **Pluie-Neige** | 2 600 m | | 2 700 m | |
| **Iso 0 °C** | 3 000 m | 3 000 m | 3 100 m | 3 100 m |
| **Vent 2500 m** | ↘ 5 km/h | → 10 km/h | → 20 km/h | ← 5 km/h |
| **Vent 3500 m** | ↘ 10 km/h | ↗ 15 km/h | ↘ 25 km/h | ← 15 km/h |

## Épaisseur de neige hors-piste

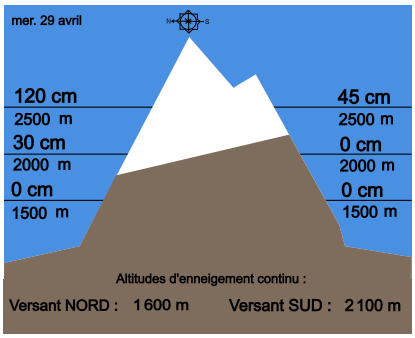


## Précipitations à 1800 m

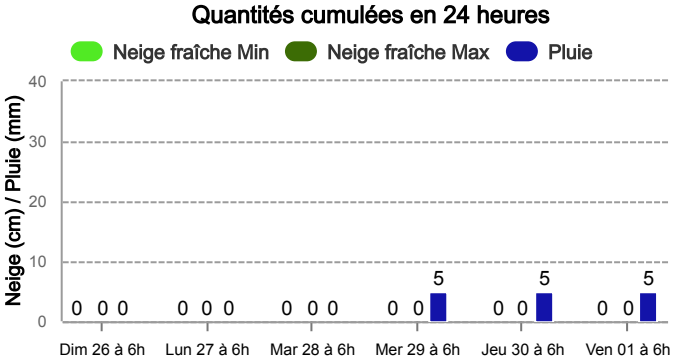


## Tendance du vendredi 01 mai

**Indice de risque limité**

Risque stationnaire, temps chaud et petites averses, départs humides l'après-midi.

Pour consulter la vigilance en cours, veuillez vous rendre sur le site https://vigilance.meteofrance.fr/fr

Météo-France - 73 avenue de Paris, 94165 Saint-Mandé cedex - Contact : contact@meteo.fr

Rédigé par Météo-France avec la contribution des observateurs du réseau nivo-météorologiques. Partenariat : ANMSM (Maires de Stations de Montagne), DSF (Domaines Skiables de France), ADSP (Directeurs de Pistes et de la Sécurité des Stations de Sports d'Hiver) et autres acteurs de la montagne.

Bulletin neige & avalanches par téléphone au
0 892 68 10 20 Service 0,35 € / min + prix appel

RÉPUBLIQUE FRANÇAISE
*Liberté Égalité Fraternité*

METEO FRANCE
À VOS CÔTÉS, DANS UN CLIMAT QUI CHANGE

# Bulletin d'estimation du risque d'avalanche
## (valable en dehors des pistes balisées et ouvertes)

# MASSIF : Vanoise

Rédigé le mercredi 29 avril 2026 à 16h

## Conditions nivo-météo des 7 derniers jours

| | jeu. 23/04 | | | | ven. 24/04 | | | | sam. 25/04 | | | | dim. 26/04 | | | | lun. 27/04 | | | | mar. 28/04 | | | | mer. 29/04 | | | |
|---|---|---|---|---|---|---|---|---|---|---|---|---|---|---|---|---|---|---|---|---|---|---|---|---|---|---|---|---|
| | 03h | 09h | 15h | 21h | 03h | 09h | 15h | 21h | 03h | 09h | 15h | 21h | 03h | 09h | 15h | 21h | 03h | 09h | 15h | 21h | 03h | 09h | 15h | 21h | 03h | 09h | 15h | 21h |
| Météo | | | | | | | | | | | | | | | | | | | | | | | | | | | | |
| Vent (km/h) | 15 | 30 | 25 | 15 | 10 | 5 | 20 | 10 | 10 | 20 | 20 | 10 | 10 | 10 | 10 | 10 | 15 | 20 | 20 | 20 | 20 | 20 | 25 | 25 | 25 | 15 | 20 | 10 |
| à 3500m | | | | | | | | | | | | | | | | | | | | | | | | | | | | |
| Vent (km/h) | 10 | 10 | 10 | 5 | 5 | 5 | 15 | 5 | 5 | 15 | 15 | 5 | 5 | 5 | 5 | 5 | 10 | 10 | 10 | 10 | 5 | 10 | 5 | 10 | 10 | 10 | 15 | 5 |
| à 2500m | | | | | | | | | | | | | | | | | | | | | | | | | | | | |

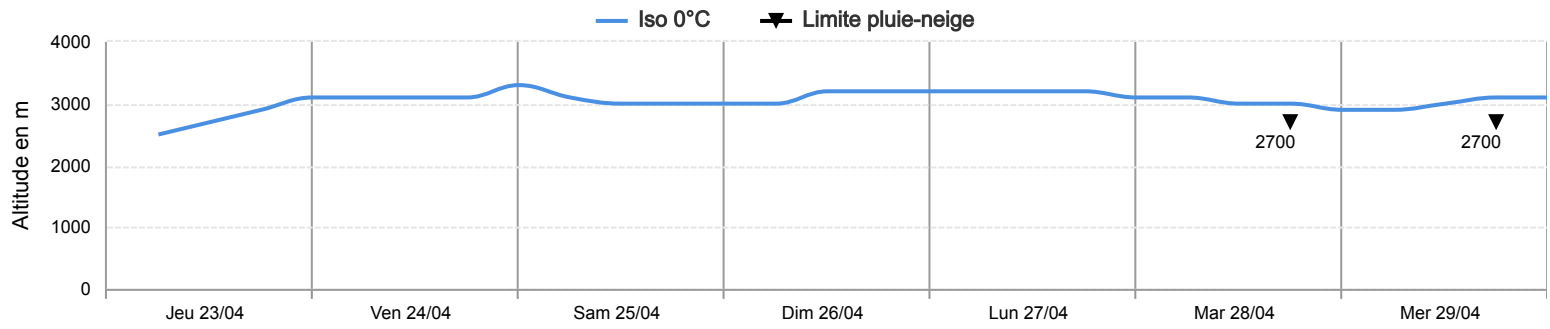


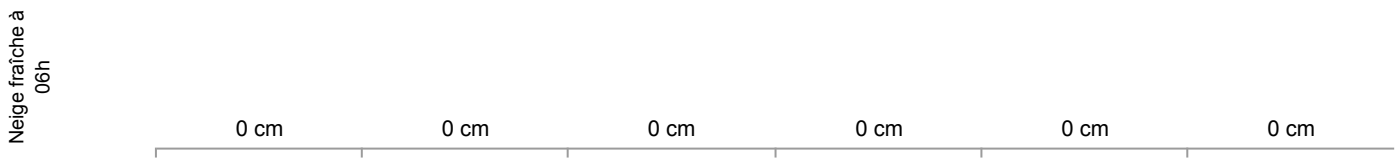


| Risque d'avalanche | jeu. 23/04 | ven. 24/04 | sam. 25/04 | dim. 26/04 | lun. 27/04 | mar. 28/04 | mer. 29/04 |
|---|---|---|---|---|---|---|---|
| | 2 | 2 | 2 | 2 | 2 | 2 | 2 |

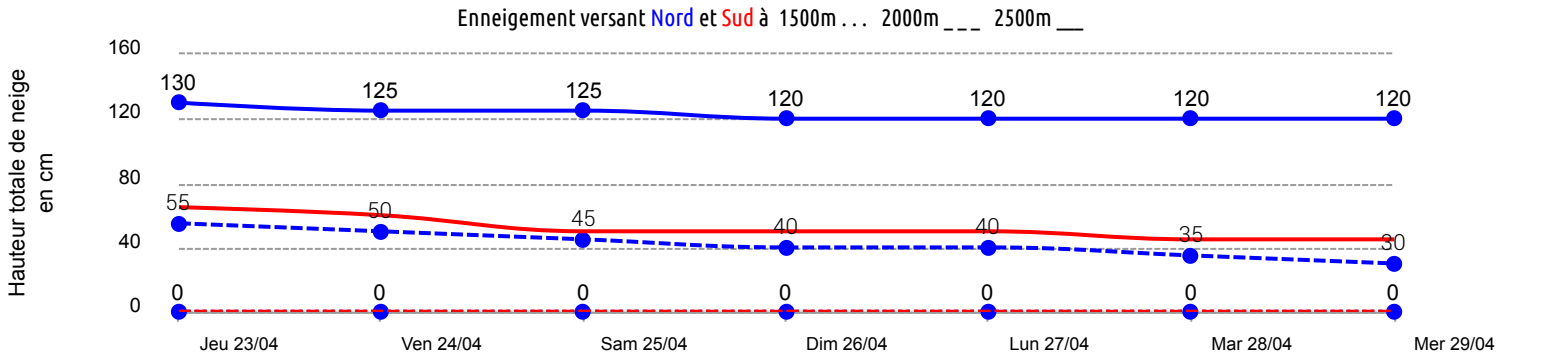


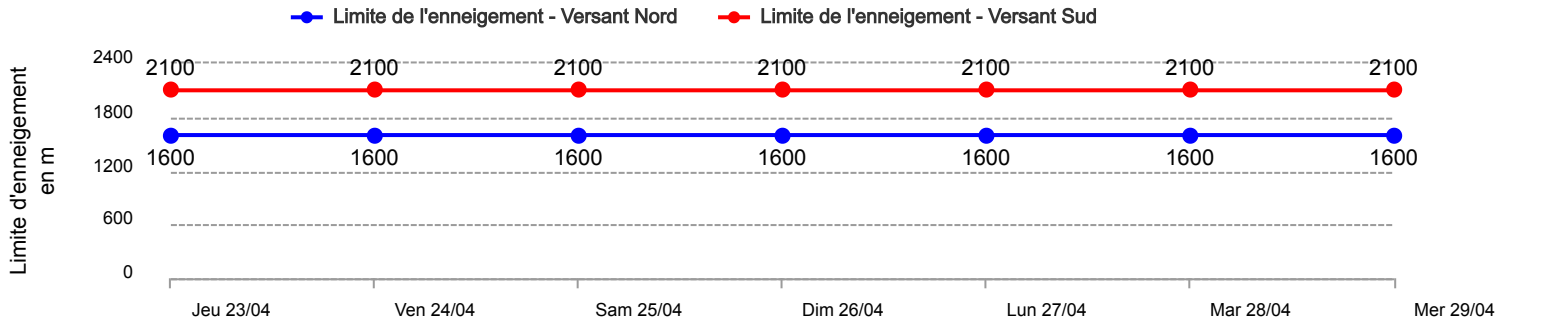


Pour consulter la vigilance en cours, veuillez vous rendre sur le site https://vigilance.meteofrance.fr/fr


Météo-France - 73 avenue de Paris, 94165 Saint-Mandé cedex - Contact : contact@meteo.fr


Bulletin neige & avalanches par téléphone au
0 892 68 10 20 Service 0,35 € / min + prix appel


Rédigé par Météo-France avec la contribution des observateurs du réseau nivo-météorologiques. Partenariat : ANMSM (Maires de Stations de Montagne), DSF (Domaines Skiables de France), ADSP (Directeurs de Pistes et de la Sécurité des Stations de Sports d'Hiver) et autres acteurs de la montagne.