GOBIERNO DE ESPAÑA
VICEPRESIDENCIA TERCERA DEL GOBIERNO
MINISTERIO PARA LA TRANSICIÓN ECOLÓGICA Y EL RETO DEMOGRÁFICO

Boletín de información nivológica y de peligro de aludes

# Pirineo Navarro y Aragonés

aemet Agencia Estatal de Meteorología

**jueves, 30 de abril de 2026**

## Pronóstico hasta las 24 horas del viernes, día 1 de mayo

(Válido fuera de pistas de esquí balizadas y abiertas)

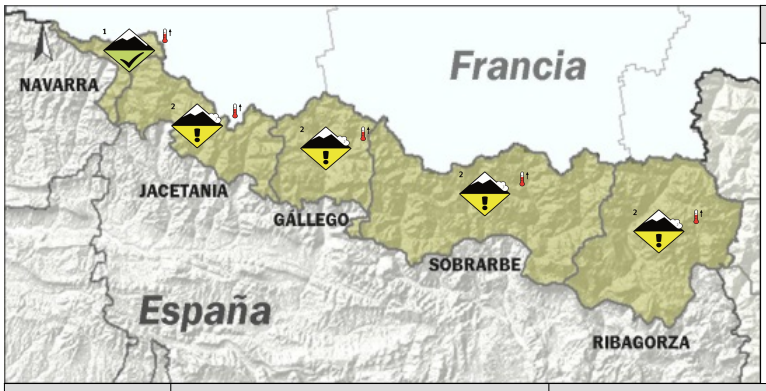


### Problemas de aludes

Nieve húmeda

Deslizamientos basales

| Macizo | Peligro | Problemas de aludes, cota, orientación, tamaño | Innivación observada (m) |
|---|---|---|---|
| Navarra | 1 Débil | Nieve húmeda: 1 | 2026-04-30 Cota más baja caras N |
| Jacetania | 2 Limitado | Nieve húmeda: 2<br>Deslizamientos basales: 2 | 2026-04-30 Cota más baja caras N |
| Gállego | 2 Limitado | Nieve húmeda: 2<br>Deslizamientos basales: 2 | 2026-04-30 Cota más baja caras N |
| Sobrarbe | 2 Limitado | Nieve húmeda: 2<br>Deslizamientos basales: 2 | 2026-04-30 Cota más baja caras N |


AEMET. Se autoriza la reproducción de su contenido citando la fuente.

Boletín de información nivológica y de peligro de aludes

# Pirineo Navarro y Aragonés



| | | | |
|---|---|---|---|
| **Ribagorza** | 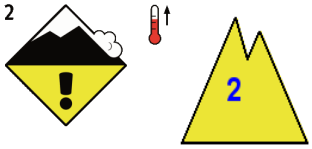  **Limitado** | **Nieve húmeda** 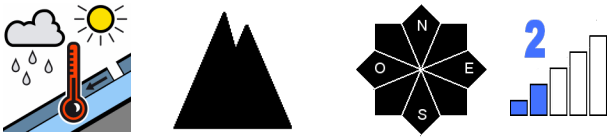  **Deslizamientos basales** 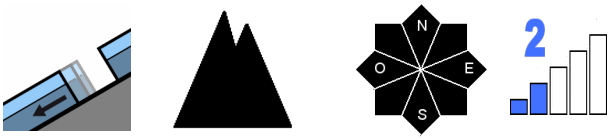  | 2026-04-30 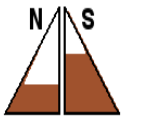  Cota más baja caras N |

## Estado del manto y observaciones recientes

Sigue la fusión acelerada del manto como consecuencia de la insolación, las temperaturas elevadas, y las precipitaciones en forma de chubascos que se van sucediendo desde hace días. Aun así, presenta cierta continuidad desde cotas altas, aunque las solanas se encuentran bastante peladas hasta altitudes considerables; en las umbrías la situación es mejor, pero van en progresivo aumento los afloramientos rocosos. Dadas las copiosas nevadas registradas durante esta temporada aún podemos encontrar espesores superiores a 100 cm por encima de 2.200 metros, pero cada vez en menos ubicaciones.
El manto está muy humidificado, con nieve vieja y densa donde predomina el grano redondo y algún estrato encostrado en el interior.

## Evolución del manto y peligro de aludes para el viernes, día 1

Situación de nieve húmeda y de deslizamientos basales.

Misma tónica que en jornadas previas, pudiendo darse algunas purgas naturales o accidentales de nieve húmeda en pendientes con suficiente inclinación y sin orientación preferente, siendo más probables en horas centrales y en áreas donde se produzcan precipitaciones en forma líquida. En general serán de tamaño pequeño o, en algunos casos, mediano, aunque no se descarta que en laderas herbosas o de roca lisa pueda producirse algún deslizamiento basal que arrastre una mayor cantidad de nieve, por lo que se recomienda tomar precauciones durante el tránsito.

## Predicción meteorológica para el viernes, día 1

Predominio de cielos nubosos o muy nubosos. Se esperan chubascos y tormentas ocasionales durante el día, que podrán ser localmente fuertes y con granizo, generalmente de tamaño pequeño. Cota de nieve: 2.700 ó 2.800 metros. Temperaturas sin cambios o en ligero descenso. Heladas débiles en los tresmiles. Vientos flojos o moderados de componentes este y sur, que tenderán a intensificarse al final del día, pudiendo ser más intensos, racheados y de dirección variable durante los chubascos o tormentas.


AEMET. Se autoriza la reproducción de su contenido citando la fuente.

Datos en la atmósfera libre:

Altitud de la isoterma de 0 ºC: 3.100 m
Altitud de la isoterma de -10 ºC: 4.700 m

Viento a 1500 m: SE 25 km/h
Viento a 3000 m: S 30 km/h

## Evolución para el sábado día 2

Nivel de peligro con pocos cambios.

(Información elaborada a partir de los datos recibidos de los refugios de Linza, Lizara, Respomuso, Panticosa, Góriz, Pineta, Angel Orús, Cap de Llauset y Belagua y de las estaciones de esquí de Formigal y Panticosa (lagos))

Escala europea de peligro de aludes

Débil Limitado Notable Fuerte Muy Fuerte

Problemas de aludes

Nieve reciente Placas de viento Capas débiles persistentes Nieve húmeda Deslizamientos basales Sin problema evidente

Nota1: Se recuerda que, siempre que haya nieve, la ausencia total de peligro no existe. Hay que tener presente que en circunstancias desfavorables, con aludes de tamaño 1 (alud pequeño o colada) y tamaño 2 (alud mediano), se pueden sufrir severos daños personales.

Nota2: Los BPA se elaboran en base a información meteorológica así como al estado del manto nivoso a través de sondeos puntuales. Se advierte a los usuarios de la variabilidad de esta información al extrapolarla a zonas extensas de montaña. Por ello, AEMET no se hace responsable de su uso para la toma de decisiones que conciernen a la seguridad personal, ni de los riesgos físicos o materiales de ellas derivadas.


AEMET. Se autoriza la reproducción de su contenido citando la fuente.