ICGC Institut Cartogràfic i Geològic de Catalunya

Servei Meteorològic de Catalunya meteo.cat

Boletín de peligro de aludes para el Pirineo de Catalunya
Del 30/04/2026 al 02/05/2026

(Válido fuera pistas de esquí y zonas no controladas)

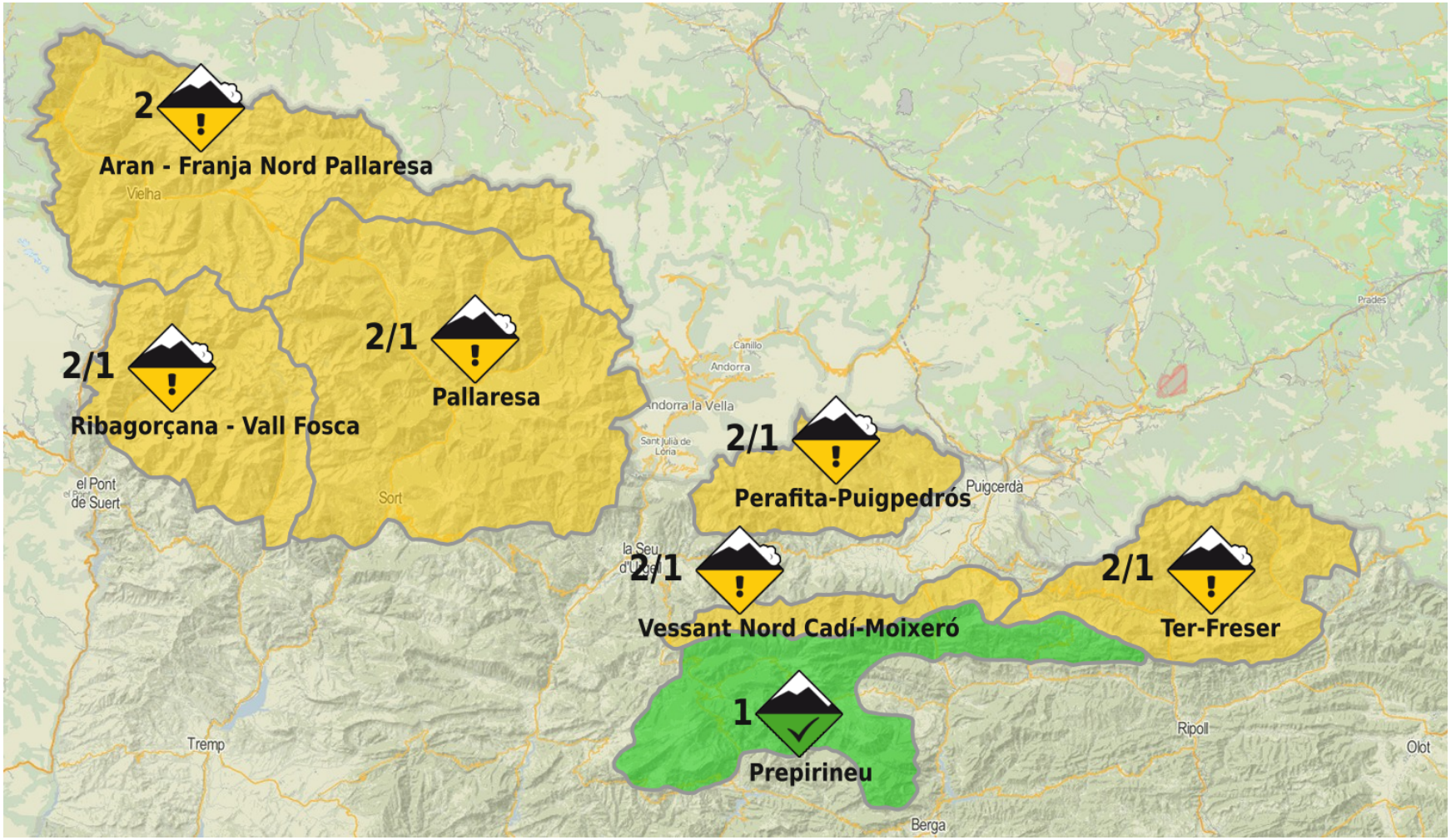

5 MUY FUERTE	4 FUERTE	3 NOTABLE	2 LIMITADO	1 DÉBIL

ICGC Institut Cartogràfic i Geològic de Catalunya

Servei Meteorològic de Catalunya

Boletín de peligro de aludes Aran - Franja Nord Pallaresa Del 30/04/2026 al 02/05/2026

(Válido fuera pistas de esquí y zonas no controladas)

LIMITADO (2)

Situación primaria

Deslizamientos basales **Distribución** **Tamaño** **Origen** **Tendencia**

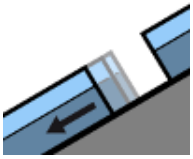

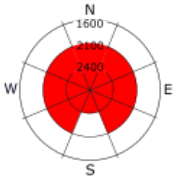

Situación secundaria

Nieve húmeda **Distribución** **Tamaño** **Origen** **Tendencia**

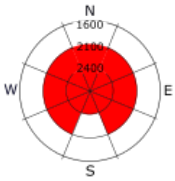

Estado del manto nivoso

El manto puede todavía incrementar su humedecimiento y densidad por la previsión de nuevas lluvias, en forma de chubasco, hasta cota alta, y por la nubosidad abundante, y las elevadas temperatura y humedad. No se prevé rehielo matinal para los próximos días.

Es probable actividad de deslizamientos basales, por encima de unos 2.000 m y en cualquier orientación y momento del día, en vertientes propicias de superficie lisa herbosa o rocosa, que podrán alcanzar hasta tamaño 2, medio.

Pueden esperarse también aludes naturales de nieve húmeda, de tamaño pequeño o medio, así como caída de bolas, sobre todo en vertientes de fuerte inclinación, más probables en momentos de chubasco.

En caso de excursión a la montaña hay que evitar zonas donde el manto muestre grietas y laderas inclinadas con fuerte humedecimiento y ablandamiento del manto.

Distribución del manto nivoso

Hay nieve en el suelo con cierta continuidad y esquiable por encima de unos 2.100 m en umbrías y es más discontinua en solanas, a partir de 2.200 m. Los espesores a unos 2.300 m rondan los 100-130 cm, con sobreacumulaciones que aún superan los 150 cm. Los valores son los normales para la época.

Tendencia para las próximas 48-72h

El manto continuará muy húmedo y con pocos cambios en cuanto a estabilidad. Evolución del peligro: ESTACIONARIO.

El próximo boletín será emitido el día 2026-05-02

5 MUY FUERTE	4 FUERTE	3 NOTABLE	2 LIMITADO	1 DÉBIL

EAWS EUROPEAN AVALANCHE WARNING SERVICES

ICGC Institut Cartogràfic i Geològic de Catalunya

meteo.cat Servei Meteorològic de Catalunya

Boletín de peligro de aludes Ribagorçana - Vall Fosca Del 30/04/2026 al 02/05/2026

(Válido fuera pistas de esquí y zonas no controladas)

LIMITADO (2) por encima de 2.200 m, DÉBIL (1) por debajo

Situación primaria

Nieve húmeda

Distribución

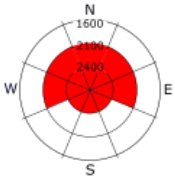

Tamaño

Origen

Tendencia

Situación secundaria

Deslizamientos basales

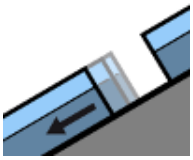

Distribución

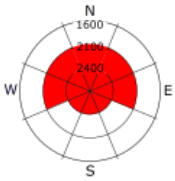

Tamaño

Origen

Tendencia

Estado del manto nivoso

Las lluvias hasta cota muy alta continuarán en los próximos días, a menudo en forma de chubasco. No ha habido ni se espera para los próximos días rehielo matinal, con una superficie del manto que se mantiene ablandada a lo largo de todo el día, aunque internamente todavía hay capas con altas durezas en un manto húmedo en su totalidad.

Continúa la probabilidad de aludes naturales de nieve húmeda y de deslizamientos basales, a cualquier hora del día, más probables en momentos de chubasco, por encima de unos 2.200 m, en cualquier orientación. Los deslizamientos podrán desencadenarse sobre superficies lisas herbosas o rocosas, y alcanzar tamaño medio. La caída de bolas y los aludes de nieve húmeda podrán afectar sobre todo vertientes de fuerte inclinación y serán por lo general de tamaño pequeño o medio.

En caso de excursión a la montaña hay que evitar zonas donde el manto muestre grietas y laderas inclinadas con fuerte humedecimiento y ablandamiento del manto.

Distribución del manto nivoso

Hay nieve por encima de unos 2.000 m en N, de forma más continua por encima de unos 2.100 m, y por encima de 2.300-2.400 m en S, a veces discontinua hasta las cumbres, y más continua en cubetas. Los grosores son irregulares pero están alrededor de 50-60 cm de media a unos 2.500 m.

Tendencia para las próximas 48-72h

El manto continuará muy húmedo y con pocos cambios en cuanto a estabilidad. Evolución del peligro: ESTACIONARIO.

El próximo boletín será emitido el día 2026-05-02

5 MUY FUERTE	4 FUERTE	3 NOTABLE	2 LIMITADO	1 DÉBIL

EAWS EUROPEAN AVALANCHE WARNING SERVICES

ICGC Institut Cartogràfic i Geològic de Catalunya

Servei Meteorològic de Catalunya

Boletín de peligro de aludes Pallaresa
Del 30/04/2026 al 02/05/2026

(Válido fuera pistas de esquí y zonas no controladas)

LIMITADO (2) por encima de 2.200 m, DÉBIL (1) por debajo

Situación primaria

Nieve húmeda

Distribución

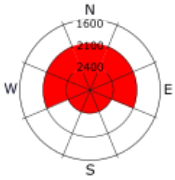

Tamaño

Origen

Tendencia

Situación secundaria

Deslizamientos basales

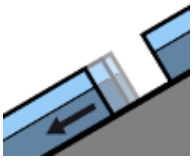

Distribución

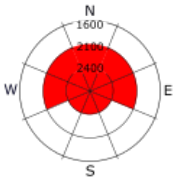

Tamaño

Origen

Tendencia

Estado del manto nivoso

Las lluvias hasta cota muy alta continuarán en los próximos días, a menudo en forma de chubasco. No ha habido ni se espera para los próximos días rehielo matinal, con una superficie del manto que se mantiene ablandada a lo largo de todo el día, aunque internamente todavía hay capas con altas durezas en un manto húmedo en su totalidad.

Continúa la probabilidad de aludes naturales de nieve húmeda y de deslizamientos basales, a cualquier hora del día, más probables en momentos de chubasco, por encima de unos 2.200 m, en cualquier orientación. Los deslizamientos podrán desencadenarse sobre superficies lisas herbosas o rocosas, y alcanzar tamaño medio. La caída de bolas y los aludes de nieve húmeda podrán afectar sobre todo vertientes de fuerte inclinación y serán por lo general de tamaño pequeño o medio.

En caso de excursión a la montaña hay que evitar zonas donde el manto muestre grietas y laderas inclinadas con fuerte humedecimiento y ablandamiento del manto.

Distribución del manto nivoso

Hay nieve por encima de unos 2.000 m en N, de forma más continua por encima de unos 2.100 m, y por encima de 2.300-2.400 m en S, a veces discontinua hasta las cumbres, y más continua en cubetas. El manto se presenta con espesores irregulares y variables, retrocediendo progresivamente en espesor y extensión.

Tendencia para las próximas 48-72h

El manto continuará muy húmedo y con pocos cambios en cuanto a estabilidad. Evolución del peligro: ESTACIONARIO.

El próximo boletín será emitido el día 2026-05-02

5 MUY FUERTE	4 FUERTE	3 NOTABLE	2 LIMITADO	1 DÉBIL

EAWS EUROPEAN AVALANCHE WARNING SERVICES

ICGC Institut Cartogràfic i Geològic de Catalunya

Servei Meteorològic de Catalunya

Boletín de peligro de aludes Perafita-Puigpedrós Del 30/04/2026 al 02/05/2026

(Válido fuera pistas de esquí y zonas no controladas)

LIMITADO (2) por encima de 2.300 m, DÉBIL (1) por debajo

Situación primaria

Nieve húmeda

Distribución

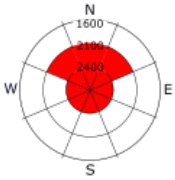

Tamaño

Origen

Tendencia

Situación secundaria

Deslizamientos basales

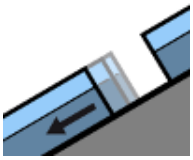

Distribución

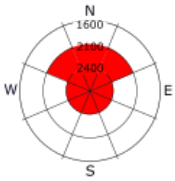

Tamaño

Origen

Tendencia

Estado del manto nivoso

Continúan para los próximos días las predicciones de lluvias hasta cotas altas, en forma de chubascos, con temperaturas positivas todo el día y elevada humedad y nubosidad abundante. Con estas condiciones, se esperan que se incremente más la humedad del manto y ausencia de rehielo matinal.

Se mantiene la probabilidad de desencadenamiento de aludes naturales de nieve húmeda y de deslizamientos basales, más alta en momentos de chubascos, por encima de unos 2.300 m, en cualquier orientación. Los aludes de nieve húmeda afectarán sobre todo vertientes de fuerte inclinación y serán por lo general de tamaño pequeño o medio. Los deslizamientos basales podrán desencadenarse sobre vertientes lisas herbosas o rocosas, y alcanzar tamaño medio.

En caso de excursión a la montaña hay que evitar zonas donde el manto muestre grietas y laderas inclinadas con fuerte humedecimiento y ablandamiento del manto.

Distribución del manto nivoso

Hay nieve esquiable en umbrías por encima de unos 2.200 m en orientaciones N y presencia de nieve en S por encima de unos 2.300 m. El manto se presenta a menudo discontinuo, sobre todo en S, y con espesores irregulares, retrocediendo progresivamente en espesor y extensión.

Tendencia para las próximas 48-72h

El manto continuará muy húmedo y con pocos cambios en cuanto a estabilidad. Evolución del peligro: ESTACIONARIO.

El próximo boletín será emitido el día 2026-05-02

5 MUY FUERTE	4 FUERTE	3 NOTABLE	2 LIMITADO	1 DÉBIL

EAWS EUROPEAN AVALANCHE WARNING SERVICES

ICGC Institut Cartogràfic i Geològic de Catalunya

Servei Meteorològic de Catalunya

Boletín de peligro de aludes Vessant Nord Cadí-Moixeró Del 30/04/2026 al 02/05/2026

(Válido fuera pistas de esquí y zonas no controladas)

LIMITADO (2) por encima de 2.200 m, DÉBIL (1) por debajo

Situación primaria

Nieve húmeda

Distribución

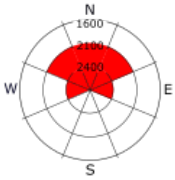

Tamaño

Origen

Tendencia

Estado del manto nivoso

Continuará la dinámica de precipitaciones en forma de lluvia en todas las cotas y temperatura y humedad elevadas. El manto se encuentra húmedo en su totalidad y con estas previsiones se podrá humedecer y densificar aún más. No se espera rehielo matinal.

Son posibles aludes naturales de nieve húmeda y caída de bolas, en cualquier orientación, más probables en momentos de chubasco. Los aludes podrán desencadenarse sobre todo en canales y laderas de fuerte pendiente. Serán por lo general aludes de pequeño tamaño (con capacidad de hacernos caer) o medio (con capacidad para enterrar a una persona).

Hay que prestar atención al terreno trampa donde un alud pequeño podría tener mayores consecuencias.

Distribución del manto nivoso

Hay nieve por encima de unos 2.100 m en N, y en S, de forma discontinua y a menudo escasa, por encima de unos 2.300 m. Los espesores rondan, en umbrías, los 70-90 cm a unos 2.300 m. Estos valores están por encima de los normales para la época.

Tendencia para las próximas 48-72h

El manto continuará muy húmedo y con pocos cambios en cuanto a estabilidad. Evolución del peligro: ESTACIONARIO.

El próximo boletín será emitido el día 2026-05-02

5 MUY FUERTE	4 FUERTE	3 NOTABLE	2 LIMITADO	1 DÉBIL

EAWS EUROPEAN AVALANCHE WARNING SERVICES

ICGC Institut Cartogràfic i Geològic de Catalunya

Servei Meteorològic de Catalunya

Boletín de peligro de aludes Prepirineu
Del 30/04/2026 al 02/05/2026

(Válido fuera pistas de esquí y zonas no controladas)

DÉBIL (1)

Situación primaria

Nieve húmeda

Distribución

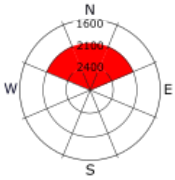

Tamaño

Origen

Tendencia

Estado del manto nivoso

Las previsiones para los próximos días indican la continuidad de las precipitaciones en forma de agua en todas las cotas, y humedad y temperaturas elevadas. Con estas condiciones no se prevé rehielo matinal, con un manto ablandado superficialmente a lo largo de todo el día y que sigue menguando en extensión y espesor, quedando restringido progresivamente a las cotas más altas del sector y dentro de canales y pequeñas cuencas.
Con las lluvias previstas el manto se humedecerá más. Son probables caídas de bolas y aludes naturales de nieve húmeda que pueden producirse a cualquier hora del día pero más probables en momentos de chubasco, afectando cualquier orientación, sobre todo en vertientes de fuerte inclinación. Los aludes serán por lo general en forma de purgas o de pequeño tamaño.

Distribución del manto nivoso

En orientación S el manto es discontinuo y escaso hasta las cimas, en N hay presencia de nieve por encima de unos 2.100 m. El manto se presenta a menudo discontinuo y con espesores irregulares, retrocediendo progresivamente en espesor y extensión.

Tendencia para las próximas 48-72h

El manto continuará muy húmedo y con pocos cambios en cuanto a estabilidad. Evolución del peligro: ESTACIONARIO.

El próximo boletín será emitido el día 2026-05-02

5 MUY FUERTE	4 FUERTE	3 NOTABLE	2 LIMITADO	1 DÉBIL

EAWS EUROPEAN AVALANCHE WARNING SERVICES

ICGC Institut Cartogràfic i Geològic de Catalunya

meteo.cat Servei Meteorològic de Catalunya

Boletín de peligro de aludes Ter-Freser
Del 30/04/2026 al 02/05/2026

(Válido fuera pistas de esquí y zonas no controladas)

LIMITADO (2) por encima de 2.300 m, DÉBIL (1) por debajo

Situación primaria

Deslizamientos basales | **Distribución** | **Tamaño** | **Origen** | **Tendencia**

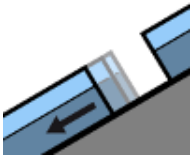

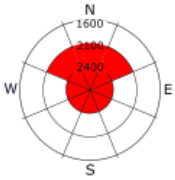

Situación secundaria

Nieve húmeda | **Distribución** | **Tamaño** | **Origen** | **Tendencia**

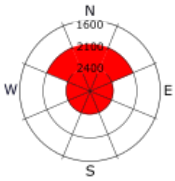

Estado del manto nivoso

Continúan para los próximos días las predicciones de lluvias hasta cotas altas, en forma de chubascos, con temperaturas positivas todo el día y elevada humedad y nubosidad abundante. Con estas condiciones, se esperan que se incremente más la humedad del manto y ausencia de rehielo matinal.

Se mantiene la probabilidad de desencadenamiento de aludes naturales de nieve húmeda y de deslizamientos basales, más alta en momentos de chubascos, por encima de unos 2.300 m, en cualquier orientación. Los aludes de nieve húmeda afectarán sobre todo vertientes de fuerte inclinación y serán por lo general de tamaño pequeño o medio. Los deslizamientos basales podrán desencadenarse sobre vertientes lisas herbosas o rocosas, y alcanzar tamaño medio.

En caso de excursión a la montaña hay que evitar zonas donde el manto muestre grietas y laderas inclinadas con fuerte humedecimiento y ablandamiento del manto.

Distribución del manto nivoso

Hay nieve por encima de unos 2.000 m en N y de unos 2.200 m en S, de forma discontinua. El manto se presenta a menudo discontinuo y con espesores irregulares, retrocediendo progresivamente en espesor y extensión.

Tendencia para las próximas 48-72h

El manto continuará muy húmedo y con pocos cambios en cuanto a estabilidad. Evolución del peligro: ESTACIONARIO.

El próximo boletín será emitido el día 2026-05-02

5 MUY FUERTE	4 FUERTE	3 NOTABLE	2 LIMITADO	1 DÉBIL

EAWS EUROPEAN AVALANCHE WARNING SERVICES