Bulletin d'estimation du risque d'avalanche
(valable en dehors des pistes balisées et ouvertes)

MASSIF : Aure Louron

Rédigé le jeudi 30 avril 2026 à 15h

Estimation des risques pour le : VENDREDI 01 MAI

MANTEAU NEIGEUX HUMIDE

2

1 → 2

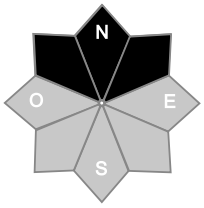

Neige humide.

Indices de risque : 5 très fort - 4 fort - 3 marqué - 2 limité - 1 faible -- En noir : les pentes les plus dangereuses

Indice de risque faible évoluant en limité.

Départs spontanés : En neige humide, avalanches de fond, rarement grandes plus nombreuses en journée..

Déclenchements provoqués : En neige humide, difficiles.

Stabilité du manteau neigeux

Situation avalancheuse typique : neige humide — avalanches de fond

Départs spontanés :
Activité devenue faible, sous forme de départs ponctuels de neige humide plus faciles au gré des éclaircies, en général de taille petite à moyenne. De rares grandes avalanches sont possibles par départ d'une avalanche de fond, en général depuis une fissure déjà ouverte. Les zones de départs se situent en général en secteurs nord-est à nord-ouest où sont les plus grosses épaisseurs de neige, au-dessus de 2300 m. Départs de fond possibles la nuit, plus probables avec le soleil.

Déclenchements provoqués : en neige humide seulement.
Le passage d'un skieur ou d'un randonneur dans la neige très humide peut favoriser un départ ponctuel en général de petite taille, rarement moyenne, plutôt à la faveur de l'ensoleillement, le manteau étant probablement ressaisi au-dessus de 2500 m au lever du soleil.
Autres :
- **corniches et ponts de neige** encore en place **fragiles et peu résistants**, pouvant **céder spontanément** ou sous le **poids d'une seule personne, même s'ils semblent épais.**
- les **chemins de randonnée déjà déneigés situés sous les secteurs raides d'altitude encore chargés** peuvent être **atteints pas une avalanche de fond de taille moyenne à rarement grande** dans l'après-midi.

Qualité de la neige

Enneigement : Encore correct pour la saison au-dessus de 2300 m, plutôt déficitaire plus bas, débutant par endroits vers 1950 m en nord et au-dessus de 2400 m en sud. Les limites de cet enneigement remontent progressivement en journée
État de la neige :
Neige humide souvent assez portante le matin au-dessus de 2400 m, se ramollissant facilement et rapidement au fil de la journée, avec des enfoncements à pied vite profonds.

Aperçu météo pour le vendredi 01 mai

	nuit	matin	après-midi	soir
Pluie-Neige	2 700 m	2 600 m	2 800 m	
Iso 0 °C	3 100 m	3 000 m	3 100 m	3 100 m
Vent 1500 m	20 km/h	15 km/h	20 km/h	20 km/h
Vent 3000 m	35 km/h	30 km/h	35 km/h	40 km/h

Assez dégagé en matinée sous un ciel voilé, formation de nuages en après-midi pouvant donner de petites averses.

Épaisseur de neige hors-piste

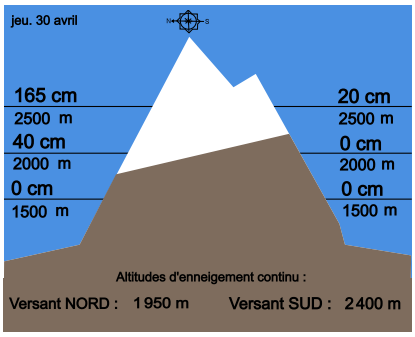

Précipitations à 1800 m

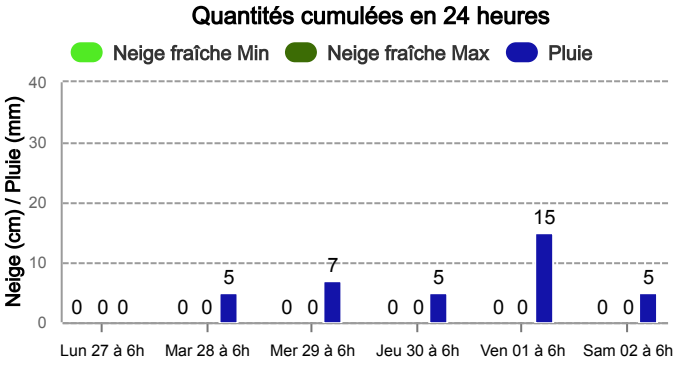

Tendance du samedi 02 mai

2

Indice de risque limité

Risques inchangés.

Pour consulter la vigilance en cours, veuillez vous rendre sur le site https://vigilance.meteofrance.fr/fr

Météo-France - 73 avenue de Paris, 94165 Saint-Mandé cedex - Contact : contact@meteo.fr

Rédigé par Météo-France avec la contribution des observateurs du réseau nivo-météorologiques. Partenariat : ANMSM (Maires de Stations de Montagne), DSF (Domaines Skiables de France), ADSP (Directeurs de Pistes et de la Sécurité des Stations de Sports d'Hiver) et autres acteurs de la montagne.

Bulletin neige & avalanches par téléphone au 0 892 68 10 20 Service 0,35 € / min + prix appel

RÉPUBLIQUE FRANÇAISE
Liberté Égalité Fraternité

METEO FRANCE
À VOS CÔTÉS, DANS UN CLIMAT QUI CHANGE

Bulletin d'estimation du risque d'avalanche

(valable en dehors des pistes balisées et ouvertes)

MASSIF : Aure Louron

Rédigé le jeudi 30 avril 2026 à 15h

Conditions nivo-météo des 7 derniers jours

	ven. 24/04				sam. 25/04				dim. 26/04				lun. 27/04				mar. 28/04				mer. 29/04				jeu. 30/04			
	03h	09h	15h	21h	03h	09h	15h	21h	03h	09h	15h	21h	03h	09h	15h	21h	03h	09h	15h	21h	03h	09h	15h	21h	03h	09h	15h	21h
Météo																												
Vent (km/h)	25	25	20	15	20	25	15	25	25	20	20	20	20	20	20	15	20	25	35	35	55	65	65	70	60	35	40	40
à 3000m																												
Vent (km/h)	15	15	10	10	10	15	5	10	5	15	10	10	10	5	2	5	10	15	20	15	20	25	40	40	25	20	25	20
à 1500m																												

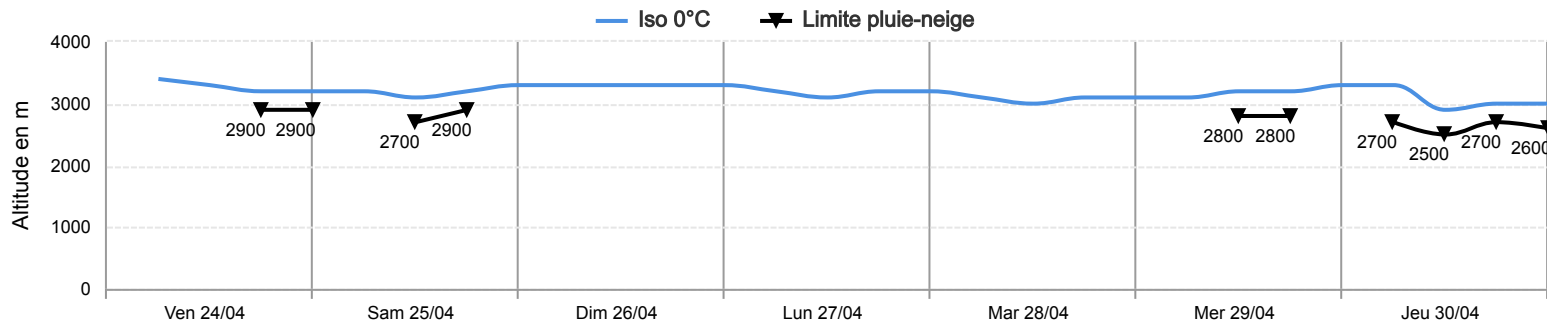

Neige fraîche à 06h

0 cm	0 cm	0 cm	0 cm	0 cm	0 cm

Risque d'avalanche	ven. 24/04	sam. 25/04	dim. 26/04	lun. 27/04	mar. 28/04	mer. 29/04	jeu. 30/04
	3	3	3	2	2	2	2

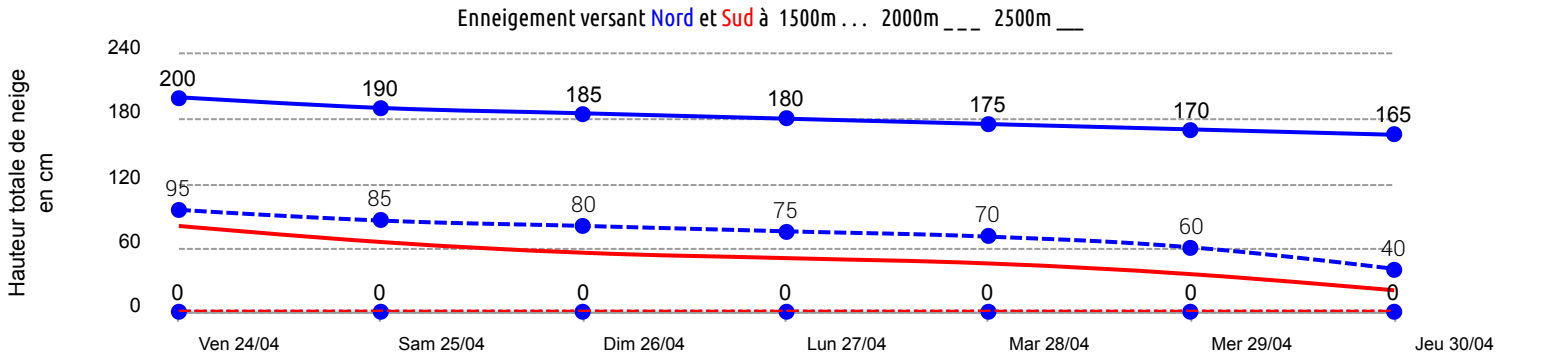

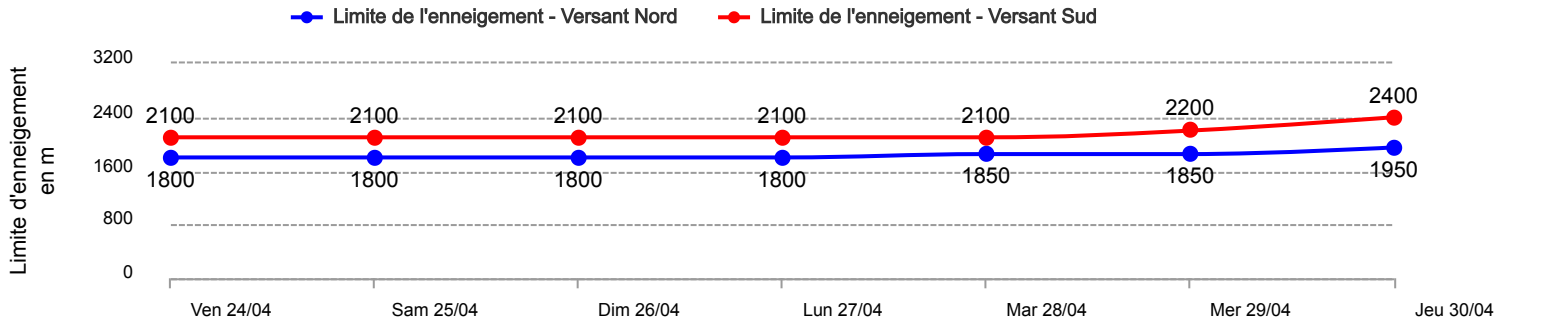

Pour consulter la vigilance en cours, veuillez vous rendre sur le site https://vigilance.meteofrance.fr/fr

Météo-France - 73 avenue de Paris, 94165 Saint-Mandé cedex - Contact : contact@meteo.fr

Bulletin neige & avalanches par téléphone au

0 892 68 10 20 Service 0,35 € / min + prix appel

Rédigé par Météo-France avec la contribution des observateurs du réseau nivo-météorologiques. Partenariat : ANMSM (Maires de Stations de Montagne), DSF (Domaines Skiables de France), ADSP (Directeurs de Pistes et de la Sécurité des Stations de Sports d'Hiver) et autres acteurs de la montagne.